TRIBUNALE DI SASSARI

SEZIONE EE.II.

Perizia dell'Esperto ex art. 568 c.p.c. Geom. Pinna Raffaele, nell'Esecuzione Immobiliare 118/2024 del R.G.E.

promossa da

******* Omissis *******

contro

******* Omissis *******

******* Omissis *******

Firmato Da: RAFFAELE PINNA Emesso Da: ARUBAPEC EU QUALIFIED CERTIFICATES CA G1 Serial#: 21f5b8d2d530589ecb330649702a56a8

SOMMARIO

Incarico 3
Premessa 3
Descrizione 3
Lotto Unico 3
Titolarità 4
Confini 4
Consistenza 4
Cronistoria Dati Catastali 5
Dati Catastali 5
Precisazioni 6
Patti 6
Stato conservativo 6
Parti Comuni 6
Servitù, censo, livello, usi civici 6
Caratteristiche costruttive prevalenti 6
Stato di occupazione 7
Provenienze Ventennali 7
Formalità pregiudizievoli 8
Normativa urbanistica 9
Regolarità edilizia 11
Vincoli od oneri condominiali 12
Stima / Formazione lotti 12
Riepilogo bando d'asta 16
Lotto Unico 16
Schema riassuntivo Esecuzione Immobiliare 118/2024 del R.G.E. 18
Lotto Unico - Prezzo base d'asta: € 132.350,42 18

Firmato Da: RAFFAELE PINNA Emesso Da: ARUBAPEC EU QUALIFIED CERTIFICATES CA G1 Serial#: 21f5b8d2d530589ecb330649702a56a8

INCARICO

All'udienza del 08/04/2025, il sottoscritto Geom. Pinna Raffaele, con studio in Piazza Col. Serra, 12 A - 07100 - Sassari (SS), email raf.pinna@libero.it, PEC raffaele.pinna@geopeg.it, Tel. 079 5903784 - 347 7771472, veniva nominato Esperto ex art. 568 c.p.c., accettava l'incarico e prestava giuramento di rito.

PREMESSA

I beni oggetto di pignoramento sono costituiti dai seguenti immobili:

- **Bene N° 1** - Appartamento ubicato a Sassari (SS) - Via Luigi Pirandello n 1/Z SCALA G, edificio 3, scala G, piano 1 (Coord. Geografiche: 40°44'36.2"N - 8°33'34.2"E)

DESCRIZIONE

Il bene immobiliare oggetto della presente procedura è costituito da un appartamento ad uso residenziale abitativo, questo fa parte di un complesso residenziale denominato "Le Rose" ubicato nella periferia della città e precisamente nella Via Luigi Pirandello n 1/Z scala G al piano 1. L'appartamento è costituito da un ingresso soggiorno, una cucina, un disimpegno, un bagno, due camere da letto e due terrazzi per una superficie utile di mq. 72,00 ed una superficie coperta di mq. 86,20. L'immobile è identificato presso l'Agenzia delle Entrate della Provincia di Sassari Sezione Territorio al Fg. 55 Mappale 167 Sub. 149 nella Via Luigi Pirandello N 1/Z piano primo Scala G Rendita: Euro 406,71, Zona censuaria 2, Categoria A/3a, Classe 3, Consistenza 4,5 vani della superficie Catastale di mq. 77 intestato a **** Omissis **** (CF.
Diritto di: Proprietà per 1/2 in regime di separazione dei beni e **** Omissis **** (CF.
Diritto di: Proprietà per 1/2 in regime di separazione dei beni. L'appartamento è costituto da un ingresso-soggiorno con antistante un terrazzo chiuso da vetrate trasformato in cucina abitabile, un disimpegno che da accesso a due camere da letto, un bagno e un balcone chiuso da vetrate utilizzato come ripostiglio, l'altezza interna e di mt. 2,68. L'immobile in oggetto è ubicato nella periferia della città dove si trovano parcheggi pubblici, negozi di quartiere oltre alle urbanizzazioni primarie e secondarie.

La vendita del bene non è soggetta IVA.

Per il bene in questione non è stato effettuato un accesso forzoso.

L'immobile non risulta realizzato in regime di edilizia residenziale pubblica convenzionata e agevolata e finanziata in tutto o in parte con risorse pubbliche, con vincoli ancora vigenti a carico del proprietario debitore.

LOTTO UNICO

Il lotto è formato dai seguenti beni:

- **Bene N° 1** - Appartamento ubicato a Sassari (SS) - Via Luigi Pirandello n 1/Z - SCALA G, edificio 3, scala G, piano 1

Firmato Da: RAFFAELE PINNA Emesso Da: ARUBAPEC EU QUALIFIED CERTIFICATES CA G1 Serial#: 21f5b8d2d530589ecb330649702a56a8

TITOLARITÀ

L'immobile oggetto dell'esecuzione, appartiene ai seguenti esecutati:

- **** Omissis **** (Proprietà 1/2)
- **** Omissis **** (Proprietà 1/2)

L'immobile viene posto in vendita per i seguenti diritti:

- **** Omissis **** (Proprietà 1/2)
- **** Omissis **** (Proprietà 1/2)

Regime patrimoniale di separazione legale dei beni.

CONFINI

Il fabbricato oggetto di pignoramento a sud confina con area cortilizia condominiale, a nord con altra proprietà, a est con vano scala condominiale e a ovest con altra unità immobiliare.

CONSISTENZA

Destinazione	Superficie Netta	Superficie Lorda	Coefficiente	Superficie Convenzionale	Altezza	Piano
Ingresso Soggiorno	20,25 mq	26,00 mq	1,00	24,00 mq	2,70 m	Primo
Cucina	12,32 mq	13,50 mq	1,00	13,50 mq	2,70 m	Primo
Disimpegno	2,86 mq	3,40 mq	1,00	3,40 mq	2,70 m	Primo
Camera	15,74 mq	17,00 mq	1,00	17,00 mq	2,70 m	Primo
Camera	13,12 mq	15,10 mq	1,00	15,10 mq	2,70 m	Primo
Bagno	6,70 mq	7,80 mq	1,00	7,80 mq	2,70 m	Primo
Balcone (Rip.)	0,90 mq	1,00 mq	0,45	0,45 mq	2,70 m	Primo
			Totale superficie convenzionale:	**81,25 mq**		
			Incidenza condominiale:	**0,00**	**%**	
			Superficie convenzionale complessiva:	**81,25 mq**		

I beni non sono comodamente divisibili in natura.

Firmato Da: RAFFAELE PINNA Emesso Da: ARUBAPEC EU QUALIFIED CERTIFICATES CA G1 Serial#: 21f5b8d2d530589ecb330649702a56a8

CRONISTORIA DATI CATASTALI

Periodo	Proprietà	Dati catastali
Dal **21/11/1992** al **09/06/1993**	**** Omissis ****	Catasto **Fabbricati** Fg. 55, Part. 167, Sub. 149, Zc. 2 Categoria A3 Cl.3, Cons. 4,5 vani Superficie catastale 77 mq Rendita € 406,71 Piano 1
Dal **09/06/1993** al **25/09/2007**	**** Omissis ****	Catasto **Fabbricati** Fg. 55, Part. 167, Sub. 149, Zc. 2 Categoria A3 Cl.3, Cons. 4,5 Vani Superficie catastale 77 mq Rendita € 406,71 Piano 1
Dal **25/09/2007** al **11/04/2025**	**** Omissis ****	Catasto **Fabbricati** Fg. 55, Part. 167, Sub. 149, Zc. 2 Categoria A3 Cl.3, Cons. 4,5 Vani Superficie catastale 77 mq Rendita € 406,71 Piano 1

Dalle verifiche e gli accertamenti effettuati i titolari catastali corrispondono a quelli reali.

DATI CATASTALI

Catasto fabbricati (CF)											
Dati identificativi				Dati di classamento							
Sezione	Foglio	Part.	Sub.	Zona Cens.	Categoria	Classe	Consistenza	Superficie catastale	Rendita	Piano	Graffato
	55	167	149	2	A3	3	4,5 vani	77 mq	406,71 €	Primo	

Corrispondenza catastale

Sussiste corrispondenza tra lo stato dei luoghi e la planimetria catastale esistente nonché con quanto presente nell'atto di pignoramento.

Dalle verifiche e gli accertamenti effettuati dal sottoscritto è emerso che la distribuzione interna dell'immobile (soggiorno - cucina e terrazzo) è differente a quanto rappresentato nella planimetria catastale per tanto sarà necessario ripristinare lo stato dei luoghi alla distribuzione interna precedente, in quanto non è possibile regolarizzarla.

Firmato Da: RAFFAELE PINNA Emesso Da: ARUBAPEC EU QUALIFIED CERTIFICATES CA G1 Serial#: 21f5b8d2d530589ecb330649702a56a8

PRECISAZIONI

Dalle verifiche e gli accertamenti non emerge nessuna precisazione.

PATTI

Dalle verifiche e gli accertamenti non emerge patti.

STATO CONSERVATIVO

Dalle verifiche e il sopraluogo effettuato in data 09.05.2025 è emerso che l'immobile oggetto della presente procedura è in buone condizioni.

PARTI COMUNI

Il fabbricato oggetto di esecuzione immobiliare fa parte di un complesso residenziale denominato "Le Rose" l'appartamento in oggetto è identificato presso l'Agenzia delle Entrate Sezione Territorio della provincia di Sassari al Fg. 55 mapp.le 167 sub.149 zona censuaria 2 Categoria A/3 della di classe 3 della superficie catastale di mq. 77 escluse superfici scoperte mq. 75 al piano primo ed una rendita pari a euro 406,71 (appartamento uno residenziale), intestati a **** Omissis **** (CF.
Diritto di: Proprietà per 1/2 in regime di separazione dei beni e **** Omissis **** (CF.
Diritto di: Proprietà per 1/2 in regime di separazione dei beni. Ad esso si accede per mezzo di un ingresso e un vano scale condominiale che danno accesso agli appartamenti, in comune con gli altri 13 (quattordici) unità immobiliari che costituiscono la palazzina oltre alle autorimesse e cantine ubicati al piano seminterrato, è presente vano tecnico condominiale ubicato al piano seminterrato con accesso dal vano scale esterno dove è ubicato l'impianto autoclave con relativa riserva idrica e i rispettivi contattori, mentre al piano seminterrato si trova uno spazio di manovra per l'accesso alle autorimesse e uno spazio antistante il fabbricato di pertinenza dello stesso stabile. Sono presenti parti comuni a tutte le unità immobiliari che costituiscono la palazzina, detti spazi sono costituiti da ingresso con accesso dalla Via L. Pirandello snc per mezzo di una rampa carrabile esterna scoperta.

SERVITÙ, CENSO, LIVELLO, USI CIVICI

Dalle verifiche e gli accertamenti non emerge servitù, censo, livello, usi civici.

CARATTERISTICHE COSTRUTTIVE PREVALENTI

Al cespite in oggetto ci si arriva percorrendo la Via L. Pirandello in direzione della rotatoria verso Sorso con la Via Buddi Buddi, sulla sinistra prima di arrivare a detta rotatoria, troviamo sulla sinistra uno slargo con dei parcheggi pubblici dove a ridosso di questi troviamo il complesso residenziale "Le Rose". Il complesso è stato realizzato tra il 1990-1993 dall'impresa **** Omissis **** costituito da quattro corpi e sette scale l'immobile oggetto della presente procedura è ubicata nella scala G ad essa ci si arriva percorrendo la stessa Via, arrivando al piazzale dove sono ubicati i parcheggi pubblici, sempre sulla sx troviamo la Palazzina che costituisce gli immobili oggetto di perizia. L'accesso al lotto su cui insiste il bene è per mezzo di un portone pedonale

Firmato Da: RAFFAELE PINNA Emesso Da: ARUBAPEC EU QUALIFIED CERTIFICATES CA G1 Serial#: 21f5b8d2d530589ecb330649702a56a8

precisamente al nc. della Via L. Pirandello n. 1 Z, il lotto risulta essere tutto recintato con muro in blocchi e sovrastante ringhiera zincata, antistante il portone che da accesso alla scala si trova una rampa scoperta esterna al corpo di fabbrica che da accesso a due piani interrati dove sono ubicate le cantine e le autorimesse facente parte dell'intero complesso residenziale, mentre lo stabile si sviluppa su quattro piani fuori terra.
L'immobile in oggetto è ubicato al piano primo esso si trova per chi esce dall'ascensore sulla sx, ed è cosi costituito: un ingresso soggiorno con annessa cucina, un disimpegno, un bagno e due camere con altezza utile interna di mt. 2,68 per una superficie complessiva mq.72,00 (superficie utile) ed una superficie coperta di mq.86,20. L'immobile ha una copertura a due falde, L'immobile è identificato presso l'Agenzia delle Entrate della Provincia di Sassari Sezione Territorio al Fg. 55 Mappale 167 Sub. 149 nella Via Luigi Pirandello N 1/Z piano primo Scala G Rendita: Euro 406,71, Zona censuaria 2, Categoria A/3a), Classe 3, Consistenza 4,5 vani della superficie Catastale di mq. 77 intestato a **** Omissis **** (CF

Diritto di: Proprietà per 1/2 in regime di separazione dei beni **** Omissis ****

Diritto di: Proprietà per 1/2 in regime di separazione dei beni. Il fabbricato ha struttura portante in c.a. oltre a tamponatura in laterizio su travi rovesce e plinti di fondazioni in cls armato, i solai piani ed inclinati di copertura risultano essere in latero cemento, costituiti da pignatte e travetti con sovrastante caldana in cls. I tramezzi divisori interni sono in mattoni di laterizio, inoltre è presente sulla muratura perimetrale in laterizio una rifodera di coibentazione costituita da mattoni forati di laterizio. Gli intonaci interni ed esterni sono costituiti da malta cementizia premiscelata a base di cemento frattazzati a civile, sono presenti sia le pitture interne che quelle esterne di protezione dell'intonaco. Gli impianti idrici/fognari ed elettrici dell'unità in oggetto sono idonei ed adeguati alle nuove norme in materia di conformità, questi risultano tutti sotto traccia. E' presente un impianto di riscaldamento a gas di città con elementi radianti in tutti gli ambienti, sono presenti inoltre due pompe di calore costituito da due unità una interna ed una esterna ma non sono funzionanti. E' presente un impianto di video citofonico. I servizi igienici sono forniti di tutti i sanitari del tipo simile Ideal Standar essi sono completi di rubinetteria con miscelatore, le pareti risultano essere piastrellate per un'altezza di mt. 2,00.
I pavimenti dell'immobile sono stati sostituiti con piastrelle in gress porcellanato di varie dimensioni. Gli infissi interni ed esterni sono di pregio in legno massello del tipo meranti con vetro camera a taglio termico di adeguato spessore, sono presenti inoltre le avvolgibili in pvc esterne mentre le porte interne sono in legno massello. La copertura del fabbricato è a due falde inclinate con sovrastante manto di tegole. L'unità immobiliare si presenta in buono stato di conservazione come si evince dalla documentazione fotografica allegata alla presente.

STATO DI OCCUPAZIONE

Il presente immobile è abitato dai coniugi **** Omissis **** (CF:

Diritto di: Proprietà per 1/2 in regime di separazione dei beni **** Omissis **** (CF:

Diritto di: Proprietà per 1/2 in regime di separazione dei beni oltre la propria figlia minore.

PROVENIENZE VENTENNALI

Per quanto riguarda l'immobile oggetto di pignoramento:

- Sussiste continuità nelle trascrizioni per il ventennio precedente alla data di trascrizione del pignoramento;

Firmato Da: RAFFAELE PINNA Emesso Da: ARUBAPEC EU QUALIFIED CERTIFICATES CA G1 Serial#: 21f5b8d2d530589ecb330649702a56a8

- La situazione della proprietà antecedente il ventennio della trascrizione del pignoramento risulta variata;
- La situazione della proprietà risulta variata.

Dalle verifiche e gli accertamenti non sono emersi atti successivi al pignoramento oggetto della presente procedura.

FORMALITÀ PREGIUDIZIEVOLI

Dalle visure ipotecarie effettuate presso l'Agenzia delle entrate di Sassari aggiornate al 10/04/2025, sono risultate le seguenti formalità pregiudizievoli:

Iscrizioni

- **IPOTECA VOLONTARIA** derivante da Concessione a Garanzia di Mutuo Condizionato
  Iscritto a Sassari il 09/03/1993
  Reg. gen. 3009 - Reg. part. 480
  Importo: € 0,00
  Note: Documenti successivi correlati: - Annotazione n.2149 del 13.11.1993 (QUIETANZA E CONFERMA; - Iscrizione n. 3163 del 27.09.2007; - Annotazione n. 3372 del 15.11.2007 (CANCELLAZIONE TOTALE).
- **IPOTECA VOLONTARIA** derivante da Concessione A Garanzia di Mutuo Fondiario
  Iscritto a Sassari il 27/09/2007
  Reg. gen. 16735 - Reg. part. 3163
  Importo: € 0,00
  Contro **** Omissis ****, **** Omissis ****
  Formalità a carico dell'acquirente
  Rogante: Porqueddu Andrea
  Data: 25/09/2007
  N° repertorio: 5953
  N° raccolta: 3721

Trascrizioni

- **ATTO TRA VIVI -COSTITUZIONE DI VINCOLO DI DESTINAZIONE**
  Trascritto a Sassari il 09/03/1993
  Reg. gen. 3010 - Reg. part. 1998
  Formalità a carico dell'acquirente
- **ATTO TRA VIVI-COMPRAVENDITA**
  Trascritto a Sassari il 25/06/1993
  Reg. gen. 8093 - Reg. part. 5444
  Formalità a carico dell'acquirente
- **ATTO TRA VIVI-COSTITUZIONE DI VINCOLO**
  Trascritto a Sassari il 27/09/2007
  Reg. gen. 16736 - Reg. part. 10687
  Contro **** Omissis ****, **** Omissis ****
  Formalità a carico dell'acquirente

Firmato Da: RAFFAELE PINNA Emesso Da: ARUBAPEC EU QUALIFIED CERTIFICATES CA G1 Serial#: 21f5b8d2d530589ecb330649702a56a8

- **ATTO TRA VIVI-COMPRAVENDITA**
  Trascritto a Sassari il 27/09/2007
  Reg. gen. 16734 - Reg. part. 10686
  A favore di **** Omissis ****, **** Omissis ****
  Formalità a carico dell'acquirente
- **ATTO ESECUTIVO O CAUTELARE-VERBAL DI PIGNORAMENTO IMMOBILI**
  Trascritto a Sassari il 14/03/2023
  Reg. gen. 4420 - Reg. part. 3249
  Contro **** Omissis ****, **** Omissis ****
  Formalità a carico della procedura
  Note: Pubblico Ufficiale UFFICIALE GIUDIZIARIO Repertorio n.232 del 13/02/2023.
- **ATTO ESECUTIVO O CAUTELARE-VERBALE DI PIGNORAMENTO IMMOBILI**
  Trascritto a Sassari il 26/09/2024
  Reg. gen. 15826 - Reg. part. 12578
  Contro **** Omissis ****, **** Omissis ****
  Formalità a carico della procedura
  Note: Pubblico Ufficiale UFF. GIUD. CORTE D'APP. DI CAGLIARI SEZ. DIST.SASSARI Repertorio n.2487 del 03/09/2024.

Oneri di cancellazione

Dalle informative ricevute presso l'Agenzia del territorio si è appurato che l'onere di cancellazione a carico della procedura, consiste nel _____ e, contestualmente, corrispondere per la loro annotazione, importi da calcolarsi come segue e che, in relazione alla formalità da cancellare, per ogni annotamento, attualmente risultano in essere: _____.

NORMATIVA URBANISTICA

Dalle verifiche e gli accertamenti l'immobile oggetto della presente procedura secondo il PRG Comunale e le Norme di Attuazione ricade nell'Ambito 22 zona B e sottozona B8 che citano le norme diseguito riportate:
CAPO 22 - AMBITO 22 –
LATTE DOLCE - S. MARIA DI PISA
ART.148 - SOTTOZONA B2
Sono ammesse le destinazioni d'uso: d0, d1.1, d3, d4.1.
Per quanto attiene la destinazione d2 (commercio), si applicano le disposizioni già dettate per la sottozona B4 dell'Ambito 15.
Per quanto attiene gli interventi si applicano le disposizioni già dettate per le sottozone B2 dell'ambito 2. Deve però essere osservata la modalità M6 per gli interventi I4,I5,I6,I7,I8
ART.149 - SOTTOZONA B6
Sono ammesse le destinazioni d'uso: d0, d4.1.
Per quanto attiene la destinazione d2 (commercio), si applicano le disposizioni già dettate per la sottozona B4 dell'Ambito 15.
Per quanto attiene gli interventi si applicano le disposizioni già dettate per le sottozone B6 dell'ambito 2.
ART.150 - SOTTOZONA B8
Valgono le prescrizioni contenute nel P.E.E.P.
Per quanto attiene la destinazione d2 (commercio), si applicano le disposizioni già dettate per la sottozona B4

Firmato Da: RAFFAELE PINNA Emesso Da: ARUBAPEC EU QUALIFIED CERTIFICATES CA G1 Serial#: 21f5b8d2d530589ecb330649702a56a8

dell'Ambito 15.

CAPO 15 - AMBITO 15 –
SERRA SECCA
ART.105 - SOTTOZONA B4
Sono ammesse le destinazioni d'uso: d0, d1, d3, d4.1.
E' ammessa la destinazione d2 (commercio) con le seguenti limitazioni:
Nuovi interventi.
Si applicano le disposizioni già dettate per la sottozona B2 dell'Ambito 2.
Concentrazioni ed ampliamenti.
Si applicano le disposizioni già dettate per le sottozona B2 dell'Ambito 2.
Centri Commerciali di Strada.
Si applicano le disposizioni già dettate per le sottozona B2 dell'Ambito 2.
Dotazione di parcheggi pertinenziali per la clientela.
L'autorizzazione per l'apertura, il trasferimento, l'accorpamento, l'ampliamento, la modifica del settore merceologico (alimentare e non alimentare) e/o del mix di superficie di vendita tra alimentare e non alimentare delle strutture di vendita è subordinata al rispetto della seguente dotazione minima di parcheggi pertinenziali per la clientela:
41
1) Strutture di Vendita Alimentari (SVA):
Per gli EV
PA alimentare = SP alimentare = 0
Per le MSV con SV <= 1500 mq.
PA alimentare >= 0,112 x SV alimentare - 18
SP alimentare >= 2,80 x SV alimentare – 450
Per le MSV con SV > 1500 mq.
PA alimentare >= 0,10 x SV alimentare
SP alimentare >= 2,50 x SV alimentare
2) Strutture di Vendita Non Alimentari (SVNA):
Per gli EV
PA non alimentare = SP non alimentare = 0
Per le MSV
PA non alimentare >= 0,03 x SV non alimentare
SP non alimentare >= 0,75 x SV non alimentare
3) Strutture di vendita miste (con una SV alimentare non superiore al 20% della SV globale e, comunque, non superiore a 500 mq)::
a) Se l'autorizzazione specifica la SV alimentare e la SV non alimentare, la dotazione minima di parcheggi è pari a:
PA totale = PA alimentare + PA non alimentare
SP totale = Sp alimentare + Sp non alimentare
Per il calcolo delle formule la SV alimentare e la SV non alimentare vengono considerate separatamente.
b) Se la richiesta di autorizzazione per la vendita di alimentari e non alimentari specifica solo la SV totale, si assume convenzionalmente che la stessa sia tutta alimentare e, per la dotazione minima di parcheggi, si applicano le formule di cui al precedente punto 1).
Dotazione di aree di sosta e di movimentazione dei veicoli merci.
Si applicano le disposizioni già dettate per le sottozona B2 dell'Ambito 2.
Verifica delle condizioni di compatibilità.
Si applicano le disposizioni già dettate per le sottozona B2 dell'Ambito 2.
Verifica delle condizioni di accessibilità a livello puntuale.
Si applicano le disposizioni già dettate per le sottozona B2 dell'Ambito 2.

Firmato Da: RAFFAELE PINNA Emesso Da: ARUBAPEC EU QUALIFIED CERTIFICATES CA G1 Serial#: 21f5b8d2d530589ecb330649702a56a8

Verifica dell'impatto trasportistico a livello di rete.
Si applicano le disposizioni già dettate per le sottozona B2 dell'Ambito 2.
Verifica delle condizioni di compatibilità ambientale.
Si applicano le disposizioni già dettate per le verifiche delle condizioni di compatibilità ambientale della sottozona A1 dell'ambito 1.
Per quanto attiene gli interventi si applicano le disposizioni già dettate per le sottozone B4 dell'ambito 7.
CAPO 7 - AMBITO 7
MOLINO A VENTO

32
ART. 63 - SOTTOZONA B1

Sono ammesse le destinazioni d'uso : d0, d1, d3, d4.1
Per quanto attiene la destinazione d2 (commercio), si applicano le disposizioni già dettate per la sottozona B2 dell'Ambito 2.
Per quanto attiene gli interventi si applicano le disposizioni già dettate per le sottozone B1 dell'ambito 3. (1)
Nota (1) - Il C.C. ha dato parere favorevole all'elevazione dell'altezza a mt.18 limitatamente al fabbricato sito in via Catalocchino^ via Genova - Cfr. oss. n.71 U.R.

ART. 64 - SOTTOZONA B4
Sono ammesse le destinazioni d'uso : d0, d1, d3, d4.1
Per quanto attiene la destinazione d2 (commercio), si applicano le disposizioni già dettate per la sottozona B2 dell'Ambito 2.
Nelle sottozone sono ammessi i seguenti interventi:
I1, I2, I3,
I4, I5, I6, I7, I8
con l'osservanza di M12
If non superiore a 6
H non superiore a 18
da non superiore a 4
dc non inferiore a 5 : il rispetto del limite non è obbligatorio nel caso in cui l'edificazione avvenga in aderenza ad un fabbricato preesistente.
df non inferiore a 10: il rispetto del limite non è obbligatorio nel caso in cui l'edificazione avvenga in aderenza ad un fabbricato preesistente.
Rc non superiore al 50%

REGOLARITÀ EDILIZIA

L'immobile risulta regolare per la legge n° 47/1985. La costruzione non è antecedente al 01/09/1967. Non sono presenti vincoli artistici, storici o alberghieri. Non sono presenti diritti demaniali o usi civici. L'immobile risulta agibile.

Il bene immobiliare oggetto della presente procedura fà parte di un complesso residenziale denominato "Le Rose" costituito da quattro corpi siti tra la Via Bellini e la Via Luigi Pirandello, questi sono stati edificati con le seguenti Concessioni edilizie autorizzazioni:
- N. C/90/513 rilasciata il 27.09.1990; C.E. del 06.07.1989;
- N. C/92/167 rilasciata il 22.04.1992; C.E. del 05.11.1991;
- N. C/92/313 rilasciata il 15.07.1993; C.E. del 23.06.1992;
- N. C/93/347 rilasciata il 29.07.1993; C.E. del 08.06.1993;

Firmato Da: RAFFAELE PINNA Emesso Da: ARUBAPEC EU QUALIFIED CERTIFICATES CA G1 Serial#: 21f5b8d2d530589ecb330649702a56a8

- N. C/93/391 rilasciata il 20.09.1993; C.E. del 22.06.1993;
Lavori iniziati nel 01.10.1990 e ultimati il 26.09.1993.
- Certificato di agibilità N./04/4 del 03.02.2004 a .
Appartamenti complessivi N. 70;
Attività Commerciali N 12;
Magazzini N. 6;
Posti Auto coperti N. 71;
Garage N. 03;
Attività Artigianali N. 4;
Altri Locali N. 8.

Dalle verifiche e gli accertamenti effettuati lo stato di fatto dell'immobile non corrisponde al progetto autorizzato, in quanto presenta una diversa distribuzione interna, per tanto necessita il ripristino alla stato originario autorizzato. Dette difformità riscontrate sono la trasformazione del terrazzo coperto in cucina abitabile con la demolizione del tramezzo che delimitava un cucinotto posto a sx del soggiorno antistante il terrazzo di pertinenza.

VINCOLI OD ONERI CONDOMINIALI

Sono presenti vincoli od oneri condominiali che resteranno a carico dell'acquirente.

Spese condominiali

Importo medio annuo delle spese condominiali: € 480,00

Totale spese per l'anno in corso e precedente: € 1.587,08

Dalle verifiche e gli accertamenti effettuati tramite l'amm.tore protempore del Condominio di Via V. Pirandello n. 1Z nella persona del sig. **** Omissis **** è emerso che vi un debito come da riepilogo inviato in data 20.05.2025 che si allega alla presente.

STIMA / FORMAZIONE LOTTI

Lo scrivente ha ritenuto opportuno procedere alla formazione di un lotto unico cosi costituito:

- **Bene N° 1** - Appartamento ubicato a Sassari (SS) - Via Luigi Pirandello n 1/Z - SCALA G, edificio 3, scala G, piano 1
  Il bene immobiliare oggetto della presente procedura è costituito da un appartamento ad uso residenziale abitativo, questo fa parte di un complesso residenziale denominato "Le Rose" ubicato nella periferia della città e precisamente nella Via Luigi Pirandello n 1/Z scala G al piano 1. L'appartamento è costituito da un ingresso soggiorno, una cucina, un disimpegno, un bagno, due camere da letto e due

Firmato Da: RAFFAELE PINNA Emesso Da: ARUBAPEC EU QUALIFIED CERTIFICATES CA G1 Serial#: 21f5b8d2d530589ecb330649702a56a8

terrazzi per una superficie utile di mq. 72,00 ed una superficie coperta di mq. 86,20. L'immobile è identificato presso l'Agenzia delle Entrate della Provincia di Sassari Sezione Territorio al Fg. 55 Mappale 167 Sub. 149 nella Via Luigi Pirandello N 1/Z piano primo Scala G Rendita: Euro 406,71, Zona censuaria 2, Categoria A/3a, Classe 3, Consistenza 4,5 vani della superficie Catastale di mq. 77 intestato a **** Omissis **** (CF Diritto di: Proprietà per 1/2 in regime di separazione dei beni e **** Omissis **** (

Diritto di: Proprietà per 1/2 in regime di separazione dei beni. L'appartamento è costituto da un ingresso-soggiorno con antistante un terrazzo chiuso da vetrate trasformato in cucina abitabile, un disimpegno che da accesso a due camere da letto, un bagno e un balcone chiuso da vetrate utilizzato come ripostiglio, l'altezza interna e di mt. 2,68. L'immobile in oggetto è ubicato nella periferia della città dove si trovano parcheggi pubblici, negozi di quartiere oltre alle urbanizzazioni primarie e secondarie.
Identificato al catasto Fabbricati - Fg. 55, Part. 167, Sub. 149, Zc. 2, Categoria A3
L'immobile viene posto in vendita per il diritto di Proprietà (1/1)
Valore di stima del bene: € 146.250,00
Il metodo di stima utilizzato per ottenere il più probabile valore di mercato è l'attribuzione del prezzo medio di mercato per immobili similari a quello in oggetto (per zona e caratteristiche costruttive del nuovo).
Pertanto stimeremo l'immobile in base ai valori medi di mercato a nuovo detratto del valore della vetusta, alla percentuale per la variazione del valore attuale di mercato immobiliare, oltre al costo per la sua regolarizzazione edilizia per la diversa distribuzione interna e alle spese condominiali insolute. Si determinerà cosi il valore definitivo dell'immobile oggetto di stima: Valore a nuovo dell'immobile, Superficie Convenzionale complessiva pari a mq. 81,25 x €./mq. 1.800,00 = €. 146,250,00 a dedurre il valore per la vetustà dell'immobile (per manutenzione ordinaria e straordinarie), oltre che per variazione di mercato e per la regolarizzazione edilizia con il ripristino delle opere per riportare lo stato originale dell'immobile per la diversa distribuzione degli spazi interni (soggiorno/cucina), si attribuisce una percentuale che potrebbe essere calcolata pari al (2,5%+2,5%) 5%, - il costo per la regolarizzazione edilizia e le spese insolute condominiali, di conseguenza si avrà: VALORE DI STIMA - VETUSTA IMMOBILE pari a 5% -VARIAZIONE DI MERCATO pari a 5% per complessive €. 7.312,50 - REGOLARIZZAZIONE EDILIZIA pari a €. 5.000,00 - €. 1.587,08 spese condominiali insolute, otteniamo un valore di €. 146.250,00 - €. 13.899,58, VALORE FINALE pari a €. 132.350,42.

Identificativo corpo	Superficie convenzionale	Valore unitario	Valore complessivo	Quota in vendita	Totale
Bene N° 1 - Appartamento Sassari (SS) - Via Luigi Pirandello n 1/Z SCALA G, edificio 3, scala G, piano 1	81,25 mq	1.800,00 €/mq	€ 146.250,00	100,00%	€ 146.250,00
				Valore di stima:	€ 146.250,00

Valore di stima: € 146.250,00

Firmato Da: RAFFAELE PINNA Emesso Da: ARUBAPEC EU QUALIFIED CERTIFICATES CA G1 Serial#: 21f5b8d2d530589ecb330649702a56a8

Deprezzamenti

Tipologia deprezzamento	Valore	Tipo
Stato d'uso e di manutenzione	2,50	%
Variazione mercato	2,50	%
Oneri di regolarizzazione urbanistica (ripristino stato dei luoghi soggiorno-cucina-terrazzo allo stato originario)	5000,00	€
Spese condominiali insolute alla data 30.04.2025	1587,08	€

Valore finale di stima: **€ 132.350,42**

Il bene immobiliare oggetto della presente procedura è costituito da un appartamento ad uso residenziale abitativo, questo fa parte di un complesso residenziale denominato "Le Rose" ubicato nella periferia della città e precisamente nel rione "Sassari 2" precisamente nella Via Luigi Pirandello n 1/Z scala G al piano 1. L'appartamento è costituito da un ingresso soggiorno, una cucina, un disimpegno, un bagno, due camere da letto e un ripostiglio per una superficie utile di mq. 72,00 ed una superficie coperta di mq. 86,20. L'immobile è identificato presso l'Agenzia delle Entrate della Provincia di Sassari Sezione Territorio al Fg. 55 Mappale 167 Sub. 149 nella Via Luigi Pirandello N 1/Z Scala G piano primo Rendita: Euro 406,71 Zona censuaria 2, Categoria A/3a, Classe 3, Consistenza 4,5 vani della superficie Catastale di mq. 77 intestato a **** Omissis **** (C.F.: Diritto di: Proprietà per 1/2 in regime di separazione dei beni e **** Omissis **** (C.F.: Diritto di: Proprietà per 1/2 in regime di separazione dei beni.
Il metodo di stima utilizzato per ottenere il più probabile valore di mercato è l'attribuzione del prezzo medio di mercato per immobili similari a quello in oggetto (per zona e caratteristiche costruttive del nuovo).
Pertanto stimeremo l'immobile in base ai valori medi di mercato a nuovo detratto del valore della vetusta, alla percentuale per la variazione del valore attuale di mercato immobiliare, oltre al costo per la sua regolarizzazione edilizia per la diversa distribuzione interna e alle spese condominiali insolute. Si determinerà cosi il valore definitivo dell'immobile oggetto di stima: Valore a nuovo dell'immobile, Superficie Convenzionale complessiva pari a mq. 81,25 x €./mq. 1.800,00 = €. 146,250,00 a dedurre il valore per la vetustà dell'immobile (per manutenzione ordinaria e straordinarie), oltre che per variazione di mercato e per la regolarizzazione edilizia con il ripristino delle opere per riportare lo stato originale dell'immobile per la diversa distribuzione degli spazi interni (soggiorno/cucina), si attribuisce una percentuale che potrebbe essere calcolata pari al (2,5%+2,5%) 5%, - il costo per la regolarizzazione edilizia e le spese insolute condominiali, di conseguenza si avrà: VALORE DI STIMA - VETUSTA IMMOBILE pari a 5% -VARIAZIONE DI MERCATO pari a 5% per complessive €. 7.312,50 - REGOLARIZZAZIONE EDILIZIA pari a €. 5.000,00 - €. 1.587,08 spese condominiali insolute, otteniamo un valore di €. 146.250,00 - €. 13.899,58, VALORE FINALE pari a €. 132.350,42.

Assolto il proprio mandato, il sottoscritto Esperto ex art. 568 c.p.c. deposita la relazione di stima presso questo Spettabile Tribunale, tanto in assolvimento dell'incarico conferitogli dalla S.V. e resta a disposizione per eventuali chiarimenti.

Sassari, li 22/05/2025

L'Esperto ex art. 568 c.p.c.
Geom. Pinna Raffaele

Firmato Da: RAFFAELE PINNA Emesso Da: ARUBAPEC EU QUALIFIED CERTIFICATES CA G1 Serial#: 21f5b8d2d530589ecb330649702a56a8

ELENCO ALLEGATI:

- ✓ N° 5 Concessione edilizia - Concessioni Edilizie (Aggiornamento al 20/09/1993)
- ✓ N° 1 Planimetrie catastali - Planimetria Catastale (Aggiornamento al 10/04/2025)
- ✓ N° 4 Visure e schede catastali - Visure Catastali e Ispezioni Ipotecarie (Aggiornamento al 10/04/2025)
- ✓ N° 1 Foto - Documentazione Fotografica (Aggiornamento al 21/05/2025)
- ✓ N° 2 Tavola del progetto - Progetto Autorizzato (Aggiornamento al 18/05/1989)
- ✓ N° 3 Altri allegati - APE 02-2025 (Aggiornamento al 21/05/2025)
- ✓ N° 1 Altri allegati - Perizia Privacy (Aggiornamento al 21/05/2025)
- ✓ N° 1 Altri allegati - Verbale IVG (Aggiornamento al 09/05/2025)
- ✓ N° 2 Altri allegati - Certificato di Agibilità (Aggiornamento al 03/02/2004)
- ✓ N° 1 Altri allegati - Rilievo Stato Attuale (Aggiornamento al 20/05/2025)

Firmato Da: RAFFAELE PINNA Emesso Da: ARUBAPEC EU QUALIFIED CERTIFICATES CA G1 Serial#: 21f5b8d2d530589ecb330649702a56a8

LOTTO UNICO

- **Bene N° 1** - Appartamento ubicato a Sassari (SS) - Via Luigi Pirandello n 1/Z - SCALA G, edificio 3, scala G, piano 1
  Il bene immobiliare oggetto della presente procedura è costituito da un appartamento ad uso residenziale abitativo, questo fa parte di un complesso residenziale denominato "Le Rose" ubicato nella periferia della città e precisamente nella Via Luigi Pirandello n 1/Z scala G al piano 1. L'appartamento è costituito da un ingresso soggiorno, una cucina, un disimpegno, un bagno, due camere da letto e due terrazzi per una superficie utile di mq. 72,00 ed una superficie coperta di mq. 86,20. L'immobile è identificato presso l'Agenzia delle Entrate della Provincia di Sassari Sezione Territorio al Fg. 55 Mappale 167 Sub. 149 nella Via Luigi Pirandello N 1/Z piano primo Scala G Rendita: Euro 406,71, Zona censuaria 2, Categoria A/3a, Classe 3, Consistenza 4,5 vani della superficie Catastale di mq. 77 intestato a **** Omissis **** (CF Diritto di: Proprietà per 1/2 in regime di separazione dei beni e **** Omissis **** (Diritto di: Proprietà per 1/2 in regime di separazione dei beni. L'appartamento è costituto da un ingresso-soggiorno con antistante un terrazzo chiuso da vetrate trasformato in cucina abitabile, un disimpegno che da accesso a due camere da letto, un bagno e un balcone chiuso da vetrate utilizzato come ripostiglio, l'altezza interna e di mt. 2,68. L'immobile in oggetto è ubicato nella periferia della città dove si trovano parcheggi pubblici, negozi di quartiere oltre alle urbanizzazioni primarie e secondarie.
  Identificato al catasto Fabbricati - Fg. 55, Part. 167, Sub. 149, Zc. 2, Categoria A3
  L'immobile viene posto in vendita per il diritto di Proprietà (1/1)
  Destinazione urbanistica: Dalle verifiche e gli accertamenti l'immobile oggetto della presente procedura secondo il PRG Comunale e le Norme di Attuazione ricade nell'Ambito 22 zona B e sottozona B8 che citano le norme diseguito riportate: CAPO 22 - AMBITO 22 – LATTE DOLCE - S. MARIA DI PISA ART.148 - SOTTOZONA B2 Sono ammesse le destinazioni d'uso: d0, d1.1, d3, d4.1. Per quanto attiene la destinazione d2 (commercio), si applicano le disposizioni già dettate per la sottozona B4 dell'Ambito 15. Per quanto attiene gli interventi si applicano le disposizioni già dettate per le sottozone B2 dell'ambito 2. Deve però essere osservata la modalità M6 per gli interventi I4,I5,I6,I7,I8 ART.149 - SOTTOZONA B6 Sono ammesse le destinazioni d'uso: d0, d4.1. Per quanto attiene la destinazione d2 (commercio), si applicano le disposizioni già dettate per la sottozona B4 dell'Ambito 15. Per quanto attiene gli interventi si applicano le disposizioni già dettate per le sottozone B6 dell'ambito 2. ART.150 - SOTTOZONA B8 Valgono le prescrizioni contenute nel P.E.E.P. Per quanto attiene la destinazione d2 (commercio), si applicano le disposizioni già dettate per la sottozona B4 dell'Ambito 15. CAPO 15 - AMBITO 15 – SERRA SECCA ART.105 - SOTTOZONA B4 Sono ammesse le destinazioni d'uso: d0, d1, d3, d4.1. E' ammessa la destinazione d2 (commercio) con le seguenti limitazioni: Nuovi interventi. Si applicano le disposizioni già dettate per la sottozona B2 dell'Ambito 2. Concentrazioni ed ampliamenti. Si applicano le disposizioni già dettate per le sottozona B2 dell'Ambito 2. Centri Commerciali di Strada. Si applicano le disposizioni già dettate per le sottozona B2 dell'Ambito 2. Dotazione di parcheggi pertinenziali per la clientela. L'autorizzazione per l'apertura, il trasferimento, l'accorpamento, l'ampliamento, la modifica del settore merceologico (alimentare e non alimentare) e/o del mix di superficie di vendita tra alimentare e non alimentare delle strutture di vendita è subordinata al rispetto della seguente dotazione minima di parcheggi pertinenziali per la clientela: 41 1) Strutture di Vendita Alimentari (SVA): Per gli EV PA alimentare = SP alimentare = 0 Per le MSV con SV <= 1500 mq. PA alimentare >= 0,112 x SV alimentare - 18 SP alimentare >= 2,80 x SV alimentare – 450 Per le MSV con SV > 1500 mq. PA alimentare >= 0,10 x SV alimentare SP alimentare >= 2,50 x SV alimentare 2) Strutture di Vendita Non Alimentari (SVNA): Per gli EV PA non alimentare = SP non alimentare = 0 Per le MSV PA non alimentare >= 0,03 x SV non alimentare SP non alimentare >= 0,75 x SV non alimentare 3) Strutture di vendita miste (con una SV alimentare non superiore al 20% della SV globale e,

Firmato Da: RAFFAELE PINNA Emesso Da: ARUBAPEC EU QUALIFIED CERTIFICATES CA G1 Serial#: 21f5b8d2d530589ecb330649702a56a8

comunque, non superiore a 500 mq):: a) Se l'autorizzazione specifica la SV alimentare e la SV non alimentare, la dotazione minima di parcheggi è pari a: PA totale = PA alimentare + PA non alimentare SP totale = Sp alimentare + Sp non alimentare Per il calcolo delle formule la SV alimentare e la SV non alimentare vengono considerate separatamente. b) Se la richiesta di autorizzazione per la vendita di alimentari e non alimentari specifica solo la SV totale, si assume convenzionalmente che la stessa sia tutta alimentare e, per la dotazione minima di parcheggi, si applicano le formule di cui al precedente punto 1). Dotazione di aree di sosta e di movimentazione dei veicoli merci. Si applicano le disposizioni già dettate per le sottozona B2 dell'Ambito 2. Verifica delle condizioni di compatibilità. Si applicano le disposizioni già dettate per le sottozona B2 dell'Ambito 2. Verifica delle condizioni di accessibilità a livello puntuale. Si applicano le disposizioni già dettate per le sottozona B2 dell'Ambito 2. Verifica dell'impatto trasportistico a livello di rete. Si applicano le disposizioni già dettate per le sottozona B2 dell'Ambito 2. Verifica delle condizioni di compatibilità ambientale. Si applicano le disposizioni già dettate per le verifiche delle condizioni di compatibilità ambientale della sottozona A1 dell'ambito 1. Per quanto attiene gli interventi si applicano le disposizioni già dettate per le sottozone B4 dell'ambito 7. CAPO 7 - AMBITO 7 MOLINO A VENTO 32 ART. 63 - SOTTOZONA B1 Sono ammesse le destinazioni d'uso : d0, d1, d3, d4.1 Per quanto attiene la destinazione d2 (commercio), si applicano le disposizioni già dettate per la sottozona B2 dell'Ambito 2. Per quanto attiene gli interventi si applicano le disposizioni già dettate per le sottozone B1 dell'ambito 3. (1) Nota (1) - Il C.C. ha dato parere favorevole all'elevazione dell'altezza a mt.18 limitatamente al fabbricato sito in via Catalocchino^via Genova - Cfr. oss. Angius Giovanni n.71 U.R. ART. 64 - SOTTOZONA B4 Sono ammesse le destinazioni d'uso : d0, d1, d3, d4.1 Per quanto attiene la destinazione d2 (commercio), si applicano le disposizioni già dettate per la sottozona B2 dell'Ambito 2. Nelle sottozone sono ammessi i seguenti interventi: I1, I2, I3, I4, I5, I6, I7, I8 con l'osservanza di M12 If non superiore a 6 H non superiore a 18 da non superiore a 4 dc non inferiore a 5 : il rispetto del limite non è obbligatorio nel caso in cui l'edificazione avvenga in aderenza ad un fabbricato preesistente. df non inferiore a 10: il rispetto del limite non è obbligatorio nel caso in cui l'edificazione avvenga in aderenza ad un fabbricato preesistente. Rc non superiore al 50%

Prezzo base d'asta: **€ 132.350,42**

Firmato Da: RAFFAELE PINNA Emesso Da: ARUBAPEC EU QUALIFIED CERTIFICATES CA G1 Serial#: 21f5b8d2d530589ecb330649702a56a8

SCHEMA RIASSUNTIVO
ESECUZIONE IMMOBILIARE 118/2024 DEL R.G.E.

LOTTO UNICO - PREZZO BASE D'ASTA: € 132.350,42

Bene N° 1 - Appartamento			
Ubicazione:	Sassari (SS) - Via Luigi Pirandello n 1/Z - SCALA G, edificio 3, scala G, piano 1		
Diritto reale:	Proprietà	**Quota**	1/1
Tipologia immobile:	Appartamento Identificato al catasto Fabbricati - Fg. 55, Part. 167, Sub. 149, Zc. 2, Categoria A3	**Superficie**	81,25 mq
Stato conservativo:	Dalle verifiche e il sopraluogo effettuato in data 09.05.2025 è emerso che l'immobile oggetto della presente procedura è in buone condizioni.		
Descrizione:	Il bene immobiliare oggetto della presente procedura è costituito da un appartamento ad uso residenziale abitativo, questo fa parte di un complesso residenziale denominato "Le Rose" ubicato nella periferia della città e precisamente nella Via Luigi Pirandello n 1/Z scala G al piano 1. L'appartamento è costituito da un ingresso soggiorno, una cucina, un disimpegno, un bagno, due camere da letto e due terrazzi per una superficie utile di mq. 72,00 ed una superficie coperta di mq. 86,20. L'immobile è identificato presso l'Agenzia delle Entrate della Provincia di Sassari Sezione Territorio al Fg. 55 Mappale 167 Sub. 149 nella Via Luigi Pirandello N 1/Z piano primo Scala G Rendita: Euro 406,71, Zona censuaria 2, Categoria A/3a, Classe 3, Consistenza 4,5 vani della superficie Catastale di mq. 77 intestato a **** Omissis **** (CF. Diritto di: Proprietà per 1/2 in regime di separazione dei beni e **** Omissis **** (CF. Diritto di: Proprietà per 1/2 in regime di separazione dei beni. L'appartamento è costituto da un ingresso-soggiorno con antistante un terrazzo chiuso da vetrate trasformato in cucina abitabile, un disimpegno che da accesso a due camere da letto, un bagno e un balcone chiuso da vetrate utilizzato come ripostiglio, l'altezza interna e di mt. 2,68. L'immobile in oggetto è ubicato nella periferia della città dove si trovano parcheggi pubblici, negozi di quartiere oltre alle urbanizzazioni primarie e secondarie.		
Vendita soggetta a IVA:	NO		
Continuità trascrizioni ex art. 2650 c.c.:	SI		
Stato di occupazione:	Il presente immobile è abitato dai coniugi **** Omissis **** (CF: Diritto di: Proprietà per 1/2 in regime di separazione dei beni **** Omissis **** (CF: Diritto di: Proprietà per 1/2 in regime di separazione dei beni oltre la propria figlia minore.		

Firmato Da: RAFFAELE PINNA Emesso Da: ARUBAPEC EU QUALIFIED CERTIFICATES CA G1 Serial#: 21f5b8d2d530589ecb330649702a56a8

STUDIO TECNICO PINNA geom. Raffaele Pinna P.zza Col. Serra n.c. 12/a tel. 079/59.03.784 - cell. 347/7771472
e-mail raf.pinna@libero.it - pec raffaele.pinna@geopec.it- 07100 Sassari -

Es. imm.118/2024;

DOCUMENTAZIONE FOTOGRAFICA

Sullo stato di fatto dell'immobile ad uso abitazione sito nel Comune di Sassari nel rione Sassari 2 precisamente nella Via Pirandello n° 1Z – Scala G, il lotto è identificato al N.C.E.U. (catasto fabbricati) al foglio 55 mappale 167 sub. 149.

1. Vista aereo – fotogrammetrico con ubicazione dell'edificio interessato alla procedura;

2. Vista sullo stralcio catastale sull'ubicazione del fabbricato sito nella Via Pirandello n 1 Z;

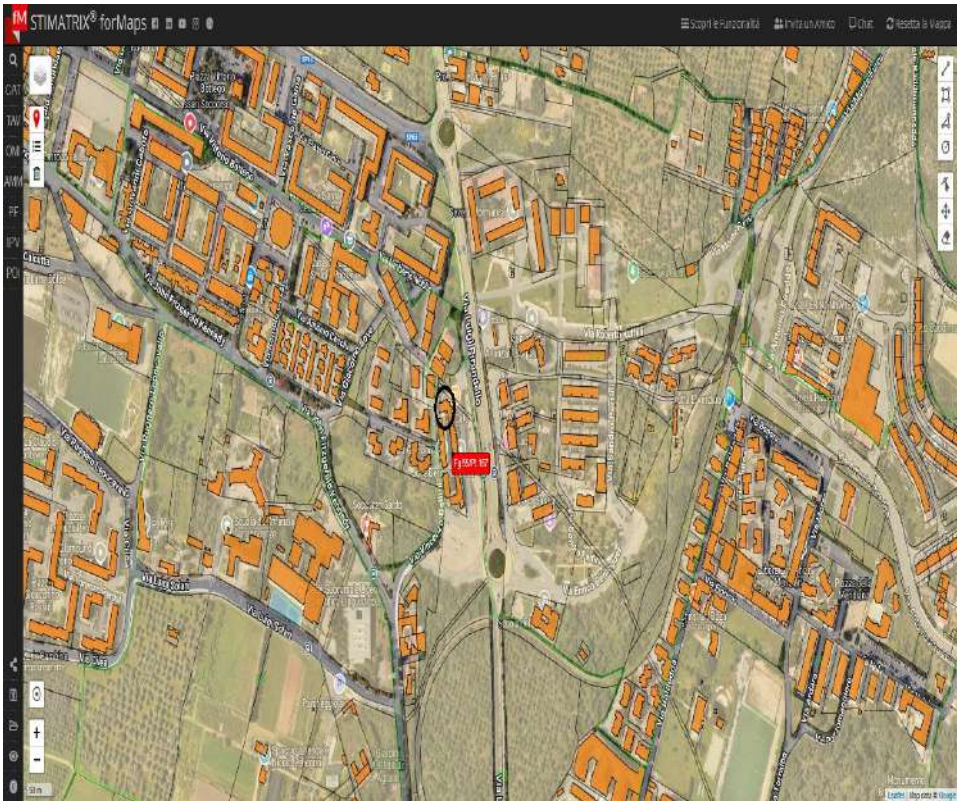

Firmato Da: RAFFAELE PINNA Emesso Da: ARUBAPEC EU QUALIFIED CERTIFICATES CA G1 Serial#: 21f5b8d2d530589ecb330649702a56a8

3. Vista dello stralcio del PRG Comunale Ambito 22 zona B sottozona B6 dell'area dove insiste il fabbricato oggetto della presente procedura;

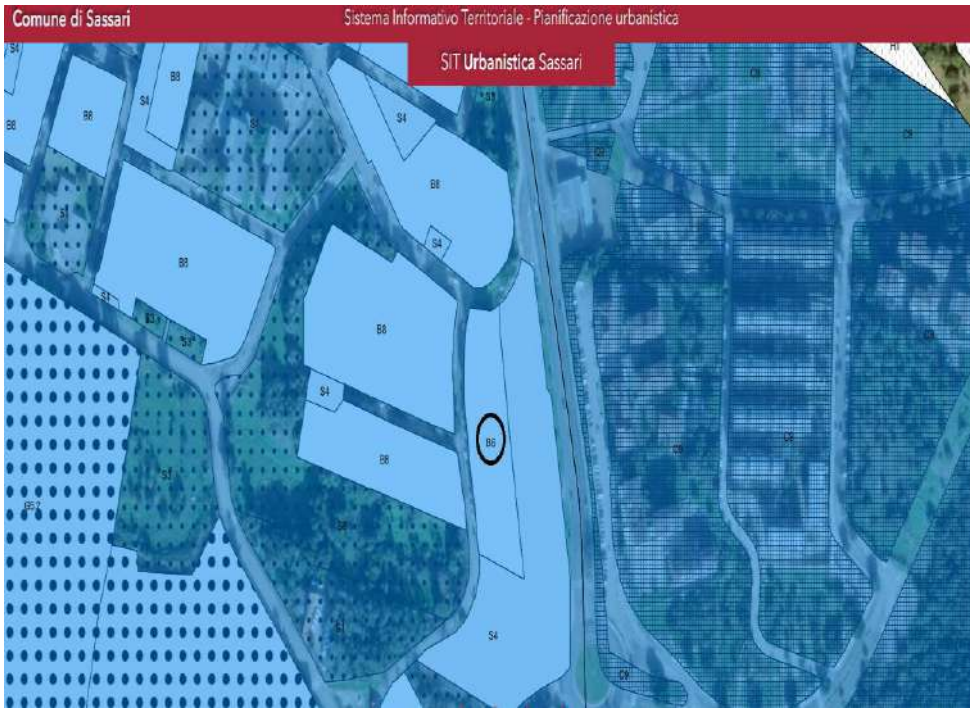

4. Vista del complesso immobiliare in cui insiste l'immobile in oggetto dalla Via Pirandello;

Firmato Da: RAFFAELE PINNA Emesso Da: ARUBAPEC EU QUALIFIED CERTIFICATES CA G1 Serial#: 21f5b8d2d530589ecb330649702a56a8

5. Vista del complesso immobiliare dalla Via V. Bellieni;

Firmato Da: RAFFAELE PINNA Emesso Da: ARUBAPEC EU QUALIFIED CERTIFICATES CA G1 Serial#: 21f5b8d2d530589ecb330649702a56a8

6. Vista sull'accesso carrabile al cortile interno ubicato sulla Via Pirandello;

7. Vista del complesso dal cortile interno dove sono ubicati i piani interrati;

Firmato Da: RAFFAELE PINNA Emesso Da: ARUBAPEC EU QUALIFIED CERTIFICATES CA G1 Serial#: 21f5b8d2d530589ecb330649702a56a8

8. del prospetto principale dell'immobile dalla Via Pirandello;

9. Vista del prospetto lato interno cortile piano primo;

Firmato Da: RAFFAELE PINNA Emesso Da: ARUBAPEC EU QUALIFIED CERTIFICATES CA G1 Serial#: 21f5b8d2d530589ecb330649702a56a8

10. Vista sull'ingresso al fabbricato ubicato sulla Via Pirandello n 1Z – Scala G piano terra;

11. Vista sui citofoni condominiali ubicati al piano terra;

Firmato Da: RAFFAELE PINNA Emesso Da: ARUBAPEC EU QUALIFIED CERTIFICATES CA G1 Serial#: 21f5b8d2d530589ecb330649702a56a8

12. Vista sull'interno dell'ingresso androne, vano scale e ascensore di accesso all'unità immobiliare;

Firmato Da: RAFFAELE PINNA Emesso Da: ARUBAPEC EU QUALIFIED CERTIFICATES CA G1 Serial#: 21f5b8d2d530589ecb330649702a56a8

Firmato Da: RAFFAELE PINNA Emesso Da: ARUBAPEC EU QUALIFIED CERTIFICATES CA G1 Serial#: 21f5b8d2d530589ecb330649702a56a8

13. Vista sul portoncino di ingresso dell'unità immobiliare ubicata al piano primo per chi sale le scale difronte a sx;

14. Vista all'interno dell'unità immobiliare ubicata al piano primo – ingresso soggiorno;

Firmato Da: RAFFAELE PINNA Emesso Da: ARUBAPEC EU QUALIFIED CERTIFICATES CA G1 Serial#: 21f5b8d2d530589ecb330649702a56a8

REGIONE AUTÒNOMA DE SARDIGNA
REGIONE AUTONOMA DELLA SARDEGNA

DATI RIASSUNTIVI DELLA CERTIFICAZIONE ENERGETICA

Nome e Cognome /Denominazione del certificatore: Raffele Pinna
Tipologia della certificazione: APE 2015
Data certificazione: 21/05/2025
Data di scadenza della certificazione: 21/05/2026

Dati generali

Destinazione d'uso: Residenziale
Classificazione edificio DPR 412: E.1 (1) - Abitazioni adibite a resi denza con carattere continuativo, quali abitazioni civili e rurali
Codice edificio scolastico:
Identificativo catastale edifici pubblici:
Oggetto dell'attestato: Unità immobiliare
Numero di unità immobiliari: 1
Motivo della certificazione: Passaggio di proprietà
Altro motivo:

Dati identificativi

Piano dell'unità immobiliare:
Interno dell'unità immobiliare:
Proprietà edificio: Privato
Zona climatica: C
Gradi Giorno: 1185
Anno di costruzione: 1000
Tipologia costruttiva: Struttura in c.a. (con chiusure in laterizi)
Tipologia edilizia: Edificio a Torre
Superficie utile riscaldata [m²]: 60.3
Superficie utile raffrescata [m²]: 0
Volume lordo riscaldato [m³]: 224.84
Volume lordo raffrescato [m³]: 0

Prestazione energetica globale e del fabbricato

Prestazione energetica del fabbricato

Indicatore prestazione invernale dell'involucro: Media

Indicatore prestazione invernale dell'involucro: Media

Prestazione energetica globale

Classe energetica dell'immobile: Classe C

Indice di prestazioni energetica globale non rinnovabile EPgl,nren (kwh/m² anno): 63.63

Edificio a energia quasi zero: No

Classe media per immobili simili di nuova costruzione: Classe A1

Indice nuovi [kWh/m² anno]: 44.66

Classe media per immobili simili già esistenti: Classe C

Indice esistenti [kWh/m² anno]: 63.63

Prestazione energetica degli impianti e consumi stimati

Fonte energetica utilizzata	Quantità annua consumata in uso standard	Unità di misura della quantità annua
Gas naturale	387	Smc

Indice prestazione energetica non rinnovabile: 63.63

Indice prestazione energetica globale rinnovabile EPgl,ren [kWh/m² anno]: 0

Emissioni di CO^2 [kg/m² anno]: 12.73

Raccomandazioni

Codice intervento	Tipo di intervento raccomandato	Comporta una ristrutturazione importante	Tempo di ritorno dell'investimento	Classe energetica raggiungibile con l'intervento	Indice di prestazione energetica raggiungibile con l'intervento (EPgl,nren kWh/m²anno)
REN2	Sostituzione infissi (Uw: 2,200) e applicazione	No	26	Classe C	61.11

	di schermature (Tipo: Tende bianche - INTERNA)				
REN3	Rimozione dell'impianto/i Caldaia a GAS e installazione dei seguenti nuovi impianti: Caldaia a condensazione	No	26	Classe B	53.14
REN6	Installazione dei seguenti impianti: Solare termico	No	26	Classe C	55.05

Classe energetica raggiungibile con tutti gli interventi raccomandati: Classe A1

Indice di prestazione energetica raggiungibile con tutti gli interventi raccomandati [kWh/m² anno]: 44.52

Altri dati energetici generali

Energia esportata [kWh/anno]: 0

Vettore energetico: Energia elettrica

Altri dati di dettaglio del fabbricato

V-Volume riscaldato [m³]: 224.84

S-Superficie disperdente [m²]: 100.28

Rapporto Superficie/Volume: 0.446

Limite EPH,nd - indice di prestazione termica utile per il riscaldamento: 10.130000114440918

Asol/Asup,utile - area solare equivalente estiva per unità di superficie utile: 0.056

YIE - trasmittanza termica periodica [W/m² K]: 0.1286

Dati di dettaglio degli impianti

Servizio energetico	Tipo di impianto	Anno di installazione	Codice catasto regionale	Descrizione impianto	Potenza Nominale	Vettore energetico

			impianti termici		kW	
Climatizzazione invernale	Caldaia standard	1000	Non presente	Caldaia a GAS	24	Gas naturale
Prod. acqua calda sanitaria	Caldaia standard	1000	Non presente	Caldaia a GAS	24	Gas naturale

Servizi energetici

Servizio energetico	EPren	EPnren	Impianto simulato	Efficienza media stagionale
Climatizzazione invernale	0	39.46	No	0.43
Prod. acqua calda sanitaria	0	24.17	No	0.72

Informazioni sul miglioramento della prestazione energetica: si rileva l'assenza del libretto della caldaia per tanto si dichiara la validità ad un anno

Sopralluoghi e dati di ingresso: Sì

Data sopralluogo: 09/05/2025

Il software utilizzato risponde ai requisiti di rispondenza e garanzia di scostamento massimo dei risultati conseguiti rispetto ai valori ottenuti per mezzo dello strumento di riferimento nazionale: Sì

Ai fini della redazione del presente attestato è stato utilizzato un software che impieghi un metodo di calcolo semplificato: No

Riferimento standard epglnren: 44.65999984741211

Numero del certificato (cti) del software utilizzato: 64

Indice prestazione energetica non rinnovabile: 63.63

Riscaldamento: indice di prestazione termica utile: 17.03

Software utilizzato per la classificazione: Blumatica Energy 6

Software certificato dal CTI: Sì

Soggetto certificatore

Titolo soggetto certificatore: Geometra

Indirizzo: Piazza Col. G. Serra, 12a - 07100 - SASSARI (SS)

Tipologia soggetto: Tecnico abilitato

Ordine iscrizione: Collegio dei Geometri della Provincia di Sassari al n 2129

Informazioni aggiuntive:

Dichiarazione di indipendenza:

Il sottoscritto certificatore, consapevole delle responsabilità assunte ai sensi degli artt.359 e 481 del Codice Penale, DICHIARA di aver svolto con indipendenza ed imparzialità di giudizio l'attività di Soggetto Certificatore del sistema edificio impianto oggetto del presente attestato e l'assenza di conflitto di interessi ai sensi dell'art.3 del D.P.R. 16 aprile 2013, n. 75

ATTESTATO DI PRESTAZIONE ENERGETICA DEGLI EDIFICI

CODICE CERTIFICATO: APE_02_2025_RP_ES

VALIDO FINO AL: 21/05/2026

DATI GENERALI

Destinazione d'uso

- [X] Residenziale
- [ ] Non residenziale

Classificazione D.P.R. 412/93: E.1.1

Oggetto dell'attestato

- [ ] Intero edificio
- [X] Unità immobiliare
- [ ] Gruppo di unità immobiliari

numero di unità immobiliari di cui è composto l'edificio:

- [ ] Nuova costruzione
- [X] Passaggio di proprietà
- [ ] Locazione
- [ ] Ristrutturazione importante
- [ ] Riqualificazione energetica
- [ ] Altro:

Dati identificativi

Regione:	Sardegna
Comune:	Sassari
Indirizzo:	Via Pirandello, n. 1Z
Piano:	
Interno:	
Coordinate GIS:	40,740307 ; 8,560204

Zona climatica:	C
Anno di costruzione:	
Superficie utile riscaldata (m^2):	60,30
Superficie utile raffrescata (m^2):	0,00
Volume lordo riscaldato (m^3):	224,84
Volume lordo raffrescato (m^3):	0,00

Comune catastale	Sassari								Sezione				Foglio		55		Particella		167	
Subalterni	da	149	a	149		da		a			da		a			da		a		
Altri subalterni																				

Servizi energetici presenti

- [X] Climatizzazione invernale
- [ ] Ventilazione meccanica
- [ ] Illuminazione
- [ ] Climatizzazione estiva
- [X] Prod. acqua calda sanitaria
- [ ] Trasporto di persone o cose

PRESTAZIONE ENERGETICA GLOBALE E DEL FABBRICATO

La sezione riporta l'indice di prestazione energetica globale non rinnovabile in funzione del fabbricato e dei servizi energetici presenti, nonché la prestazione energetica del fabbricato, al netto del rendimento degli impianti presenti.

Prestazione energetica del fabbricato

INVERNO	ESTATE

Prestazione energetica globale

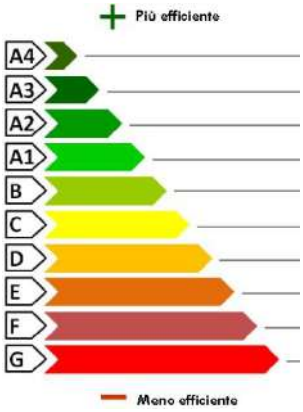

EDIFICIO A ENERGIA QUASI ZERO [ ]

CLASSE ENERGETICA

C

63,63 kWh/m^2 anno

Riferimenti

Gli immobili simili a questo avrebbero in media la seguente classificazione:

se nuovi:

A1

44,66 kWh/m^2 anno

Firmato Da: RAFFAELE PINNA Emesso Da: ARUBAPEC EU QUALIFIED CERTIFICATES CA G1 Serial#: 21f5b8d2d530589ecb330649702a56a8

PRESTAZIONE ENERGETICA DEGLI IMPIANTI E CONSUMI STIMATI

La sezione riporta l'indice di prestazione energetica rinnovabile e non rinnovabile, non chè una stima dell'energia annua consumata annualmente dall'immobile secondo un uso standard.

Prestazioni energetiche degli impianti e stima dei consumi di energia

	FONTI ENERGETICHE UTILIZZATE	Quantità annua consumata in uso standard
☐	Energia elettrica da rete	-
X	Gas naturale	386,69 m^3
☐	GPL	-
☐	Carbone	-
☐	Gasolio	-
☐	Olio combustibile	-
☐	Propano	-
☐	Butano	-
☐	Kerosene	-
☐	Antracite	-
☐	Biomasse	-
☐	Solare fotovoltaico	-
☐	Solare termico	-
☐	Eolico	-
☐	Teleriscaldamento	-
☐	Teleraffrescamento	-
☐	Altro	-

Indici di prestazione energetica globali ed emissioni

Indice della prestazione energetica non rinnovabile
EPgl,nren
kWh/m^2 anno
63,63

Indice della prestazione energetica rinnovabile
EPgl,ren
kWh/m^2 anno
0,00

Emissioni di CO_2
kg/m^2 anno
12,73

RACCOMANDAZIONI

La sezione riporta gli interventi raccomandati e la stima dei risultati conseguibili, con il singolo intervento o con la realizzazione dell'insieme di essi, esprimendo una valutazione di massima del potenziale di miglioramento dell'edificio o dell'immobile oggetto dell'attestato di prestazione energetica.

RIQUALIFICAZIONE ENERGETICA E RISTRUTTURAZIONE IMPORTANTE

INTERVENTI RACCOMANDATI E RISULTATI CONSEGUIBILI

Codice	TIPO DI INTERVENTO RACCOMANDATO	Comporta una ristrutturazione importante	Tempo di ritorno dell'investimento [anni]	Classe energetica raggiungibile con l'intervento [EPgl,nren - kWh/m^2 anno]	CLASSE ENERGETICA raggiungibile se si realizzano tutti gli interventi raccomandati
REN1					A1 44,52 kWh/m^2 anno 26 anni
REN2	Sostituzione infissi (Uw: 2,200) e applicazione di schermature (Tipo: Tende bianche - INTERNA)	No	26,0	C - 61,11	
REN3	Rimozione dell'impianto/i Caldaia a GAS e installazione dei seguenti nuovi impianti: Caldaia a condensazione	No	26,0	B - 53,14	
REN4					
REN5					
REN6	Installazione dei seguenti impianti: Solare termico	No	26,0	C - 55,05	

Firmato Da: RAFFAELE PINNA Emesso Da: ARUBAPEC EU QUALIFIED CERTIFICATES CA G1 Serial#: 21f5b8d2d530589ecb330649702a56a8

ALTRI DATI ENERGETICI GENERALI

Energia esportata	0,00 kWh/anno	Vettore energetico: -

ALTRI DATI DI DETTAGLIO DEL FABBRICATO

V - Volume riscaldato	224,840	m^3
S - Superficie disperdente	100,285	m^2
Rapporto S/V	0,446	
$EP_{H,nd}$	17,0	kWh/m^2 anno
$A_{sol,est}/A_{sup,utile}$	0,06	-
Y_{IE}	0,13	W/m^2K

DATI DI DETTAGLIO DEGLI IMPIANTI

Servizio energetico	Tipo di impianto	Anno di installazione	Codice catasto regionale impianti termici	Vettore energetico utilizzato	Potenza Nominale kW	Efficienza media stagionale		EPren kWh/m^2 anno	EPnren kWh/m^2 anno
Climatizzazione invernale						0,431	η_H	0,0	39,5
Climatizzazione estiva							η_C		
Prod. acqua calda sanitaria						0,723	η_W	0,0	24,2
Impianti combinati	Caldaia a GAS			Gas naturale (Metano)	24,0	0,820	η_{gn}		
Produzione da fonti rinnovabili									
Ventilazione meccanica									
Illuminazione									
Trasporto di persone o cose									

Firmato Da: RAFFAELE PINNA Emesso Da: ARUBAPEC EU QUALIFIED CERTIFICATES CA G1 Serial#: 21f5b8d2d530589ecb330649702a56a8

INFORMAZIONI SUL MIGLIORAMENTO DELLA PRESTAZIONE ENERGETICA

La sezione riporta informazioni sulle opportunità, anche in termini di strumenti di sostegno nazionali o locali, legate all'esecuzione di diagnosi energetiche e interventi di riqualificazione energetica, comprese le ristrutturazioni importanti.

si rileva l'assenza del libretto della caldaia per tanto si dichiara la validità ad un anno

SOGGETTO CERTIFICATORE

☐ Ente / Organismo pubblico	☒ Tecnico abilitato	☐ Organismo / Società

Nome e Cognome / Denominazione	Raffele Pinna
Indirizzo	Piazza Col. G. Serra, 12a - 07100 - SASSARI (SS)
E-mail	raf.pinna@libero.it
Telefono	
Titolo	Geometra
Ordine/Iscrizione	Collegio dei Geometri della Provincia di Sassari al n 2129
Dichiarazione di indipendenza	*Consapevole delle responsabilità assunte in relazione ai contenuti del presente attestato di prestazione energetica, ai sensi degli artt. 359, 481 del Codice Penale, DICHIARO di poter svolgere con indipendenza ed imparzialità di giudizio, l'attività di soggetto certificatore per il sistema edificio/impianto di cui al punto 1 "informazioni generali" vista l'assenza di conflitti di interesse come esplicitati nel DPR n. 75 del 16 aprile 2013, articolo 3, comma 1, lettere a) e b).*
Informazioni aggiuntive	

SOPRALLUOGHI E DATI DI INGRESSO

E' stato eseguito almeno un sopralluogo/rilievo sull'edificio obbligatorio per la redazione del presente APE?	**Sì**

SOFTWARE UTILIZZATO

Il software utilizzato risponde ai requisiti di rispondenza e garanzia di scostamento massimo dei risultati conseguiti rispetto ai valori ottenuti per mezzo dello strumento di riferimento nazionale?	**Sì**
Ai fini della redazione del presente attestato è stato utilizzato un software che impieghi un metodo di calcolo semplificato?	**No**

Il presente attestato è reso, dal sottoscritto, in forma di dichiarazione sostitutiva di atto notorio ai sensi dell'articolo 47 del D.P.R. 445/2000 e dell'articolo 15, comma 1 del D.Lgs. 192/2005 così come modificato dall'articolo 12 del D.L. 63/2013

Data di emissione 21/05/2025 Firma e timbro del tecnico o firma digitale Geom. Raffaele Pinna

Firmato Da: RAFFAELE PINNA Emesso Da: ARUBAPEC EU QUALIFIED CERTIFICATES CA G1 Serial#: 21f5b8d2d530589ecb330649702a56a8

Il presente documento attesta la **prestazione** e la **classe energetica** dell'edificio o dell'unità immobiliare, ovvero la quantità di energia necessaria ad assicurare il confort attraverso i diversi servizi erogati dai sistemi tecnici presenti, in condizioni convenzionali d'uso. Al fine di individuare le potenzialità di miglioramento della prestazione energetica, l'attestato riporta informazioni specifiche sulle prestazioni energetiche del fabbricato e degli impianti. Viene altresì indicata la classe energetica più elevata raggiungibile in caso di realizzazione delle misure migliorative consigliate, così come descritte nella sezione "**raccomandazioni**" (pag. 2).

PRIMA PAGINA

Informazioni generali: tra le informazioni generali è riportata la motivazione alla base della redazione dell'APE. Nell'ambito del periodo di validità, ciò non preclude l'uso dell'APE stesso per i fini di legge, anche se differenti da quelli ivi indicati.
Prestazione energetica globale (EPgl,nren): fabbisogno annuale di energia primaria non rinnovabile relativa a tutti i servizi erogati dai sistemi tecnici presenti, in base al quale è identificata la classe di prestazione dell'edificio in una scala da A4 (edificio più efficiente) a G (edificio meno efficiente).
Prestazione energetica del fabbricato: indice qualitativo del fabbisogno di energia necessario per il soddisfacimento del confort interno, indipendente dalla tipologia e dal rendimento degli impianti presenti. Tale indice da un'indicazione di come l'edificio, d'estate e d'inverno, isola termicamente gli ambienti interni rispetto all'ambiente esterno. La scala di valutazione qualitativa utilizzata osserva il seguente criterio:

QUALITA' ALTA	QUALITA' MEDIA	QUALITA' BASSA

I valori di soglia per la definizione del livello di qualità, suddivisi per tipo di indicatore, sono riportati nelle Linee guida per l'attestazione energetica degli edifici di cui al decreto previsto dall'articolo 6, comma 12 del D.Lgs. 192/2005.
Edificio a energia quasi zero: edificio ad altissima prestazione energetica, calcolata conformemente alle disposizioni del decreto legislativo 19 agosto 2005, n. 192 e del decreto ministeriale sui requisiti minimi previsto dall'articolo 4, comma 1 del D.Lgs. 192/2005. Il fabbisogno energetico molto basso o quasi nullo è coperto in misura significativa da energia da fonti rinnovabili, prodotta all'interno del confine del sistema (in situ). Una spunta sull'apposito spazio adiacente alla scala di classificazione indica l'appartenenza dell'edificio oggetto dell'APE a questa categoria.
Riferimenti: raffronto con l'indice di prestazione globale non rinnovabile di un edificio simile ma dotato dei requisiti minimi degli edifici nuovi, nonchè con la media degli indici di prestazione degli edifici esistenti simili, ovvero contraddistinti da stessa tipologia d'uso, tipologia costruttiva, zona climatica, dimensioni ed esposizione di quella oggetto dell'attestato.

SECONDA PAGINA

Prestazioni energetiche degli impianti e consumi stimati: la sezione riporta l'indice di prestazione energetica rinnovabile e non rinnovabile dell'immobile oggetto di attestazione. Tali indici informano sulla percentuale di energia rinnovabile utilizzata dall'immobile rispetto al totale. La sezione riporta infine una stima del quantitativo di energia consumata annualmente dall'immobile secondo un uso standard, suddivisi per tipologia di fonte energetica utilizzata.
Raccomandazioni: di seguito si riporta la tabella che classifica le tipologie di intervento raccomandate per la riqualificazione energetica e la ristrutturazione importante.

RIQUALIFICAZIONE ENERGETICA E RISTRUTTURAZIONE IMPORTANTE EDIFICIO/UNITA' IMMOBILIARE - Tabella dei Codici

Codice	TIPO DI INTERVENTO
REN1	FABBRICATO - INVOLUCRO OPACO
REN2	FABBRICATO - INVOLUCRO TRASPARENTE
REN3	IMPIANTO CLIMATIZZAZIONE - INVERNO
REN4	IMPIANTO CLIMATIZZAZIONE - ESTATE
REN5	ALTRI IMPIANTI
REN6	FONTI RINNOVABILI

TERZA PAGINA

La terza pagina riporta la quantità di energia prodotta in situ ed esportata annualmente, non chè la sua tipologia.
Riporta infine, suddivise in due sezioni relative rispettivamente al fabbricato e agli impianti, i dati di maggior dettaglio alla base del calcolo.

Firmato Da: RAFFAELE PINNA Emesso Da: ARUBAPEC EU QUALIFIED CERTIFICATES CA G1 Serial#: 21f5b8d2d530589ecb330649702a56a8