TRIBUNALE DI SASSARI

SEZIONE EE.II.

Perizia dell'Esperto ex art. 568 c.p.c. Arch. Cocco Paola, nell'Esecuzione Immobiliare 26/2022 del R.G.E.

promossa da

******* Omissis *******

contro

******* Omissis *******

******* Omissis *******

******* Omissis *******

******* Omissis *******

******* Omissis *******

SOMMARIO

Incarico 3
Premessa 3
Descrizione 3
Lotto Unico 3
Completezza documentazione ex art. 567 3
Titolarità 4
Confini 4
Consistenza 4
Cronistoria Dati Catastali 5
Dati Catastali 5
Stato conservativo 6
Parti Comuni 6
Caratteristiche costruttive prevalenti 6
Stato di occupazione 6
Provenienze Ventennali 7
Formalità pregiudizievoli 8
Normativa urbanistica 9
Regolarità edilizia 9
Vincoli od oneri condominiali 10
Stima / Formazione lotti 10
Riepilogo bando d'asta 14
Lotto Unico 14
Schema riassuntivo Esecuzione Immobiliare 26/2022 del R.G.E. 15
Lotto Unico - Prezzo base d'asta: € 215.373,00 15
Formalità da cancellare con il decreto di trasferimento 16

INCARICO

All'udienza del 16/01/2023, il sottoscritto Arch. Cocco Paola, con studio in Viale Europa, 55 - 07041 - Alghero (SS), email paolacoccoarchitetto@gmail.com, PEC paola.cocco@archiworldpec.it, Tel. 392 4191272, veniva nominato Esperto ex art. 568 c.p.c. e in data 17/01/2023 accettava l'incarico e prestava giuramento di rito.

PREMESSA

I beni oggetto di pignoramento sono costituiti dai seguenti immobili:

- **Bene N° 1** - Appartamento ubicato a Sassari (SS) - Via Monsignor Marongiu Delrio 29

DESCRIZIONE

L'immobile oggetto di pignoramento si trova all'interno di un fabbricato di maggior consistenza distribuito su tre livelli fuori terra e che ha accesso dalla via Marongiu; si affaccia inoltre sulla via Savoia.
Il bene pignorato è costituito da:
- una porzione di appartamento al piano terra, con accesso indipendente dal piano stradale, composto da una camera un wc e un disimpegno; questa porzione risulta in grezzo ed è utilizzata come deposito.
- un appartamento al piano primo composto da cucina, tre camere da letto, un bagno e un disimpegno; completa il bene un terrazzino per il quale l'appartamento censito al sub 3 ha una servitù per stendere (Atto di compravendita rep. 16722 del 22/11/1966). L'appartamento è in discrete condizioni, ovvero presenta evidenti tracce di umidità nelle pareti. Si accede all'immobile mediante una scala esterna condominiale.

L'immobile non risulta realizzato in regime di edilizia residenziale pubblica convenzionata e agevolata e finanziata in tutto o in parte con risorse pubbliche, con vincoli ancora vigenti a carico del proprietario debitore.

La vendita del bene non è soggetta IVA.

Per il bene in questione non è stato effettuato un accesso forzoso.

LOTTO UNICO

Il lotto è formato dai seguenti beni:

- **Bene N° 1** - Appartamento ubicato a Sassari (SS) - Via Monsignor Marongiu Delrio 29

COMPLETEZZA DOCUMENTAZIONE EX ART. 567

Si attesta che la documentazione di cui all'art. 567 c.p.c., comma 2 risulta completa.

Si precisa che non è presente denuncia di morte del sig. **** Omissis **** e/o denuncia di successione.

TITOLARITÀ

L'immobile oggetto dell'esecuzione, appartiene ai seguenti esecutati:

- **** Omissis **** (Proprietà 2/6)
- **** Omissis **** (Proprietà 1/6)
- **** Omissis **** (Proprietà 1/6)
- **** Omissis **** (Proprietà 1/6)
- **** Omissis **** (Proprietà 1/6)

L'immobile viene posto in vendita per i seguenti diritti:

- **** Omissis **** (Proprietà 2/6)
- **** Omissis **** (Proprietà 1/6)
- **** Omissis **** (Proprietà 1/6)
- **** Omissis **** (Proprietà 1/6)
- **** Omissis **** (Proprietà 1/6)

CONFINI

L'immobile per la porzione a livello del piano primo confina con il sub. 3 sullo stesso piano e con il sub 6 al piano superiore. Inferiormente confina con il sub 2,4,6,13.

In merito ai confini si precisa esserci una procedura in corso con il confinante al piano superiore, ovvero il sub. 6 di cui R.G. 1330/2017.

CONSISTENZA

Destinazione	Superficie Netta	Superficie Lorda	Coefficiente	Superficie Convenzionale	Altezza	Piano
Abitazione	85,00 mq	108,30 mq	1,00	108,30 mq	3,28 m	1
Abitazione	50,00 mq	64,00 mq	1,00	64,00 mq	3,40 m	T
Terrazza	10,00 mq	11,20 mq	0,25	2,80 mq	0,00 m	1
			Totale superficie convenzionale:	**175,10 mq**		
			Incidenza condominiale:	**0,00**	**%**	

Superficie convenzionale complessiva:	**175,10 mq**	

I beni sono comodamente divisibili in natura.

I due piani possono essere divisi in due unità separate in quanto hanno entrambi accesso autonomo e non sono collegati direttamente.

CRONISTORIA DATI CATASTALI

Periodo	Proprietà	Dati catastali
Dal **08/05/2015** al **09/11/2015**	**** Omissis ****	Catasto **Fabbricati** Fg. 87, Part. 1175, Sub. 15, Zc. 2 Categoria A3 Cl.2, Cons. 5,5 vani Rendita € 426,08 Piano T-1
Dal **09/11/2015** al **22/02/2016**	**** Omissis ****	Catasto **Fabbricati** Fg. 87, Part. 1175, Sub. 15, Zc. 2 Categoria A3 Cl.2, Cons. 5,5 vani Superficie catastale 171 mq Rendita € 426,08 Piano T-1
Dal **22/02/2016** al **29/03/2016**	**** Omissis ****	Catasto **Fabbricati** Fg. 89, Part. 721, Sub. 1, Zc. 2 Categoria A3 Cl.2, Cons. 5,5 vani Superficie catastale 171 mq Rendita € 426,08 Piano T-1
Dal **29/03/2016** al **09/05/2016**	**** Omissis ****	Catasto **Fabbricati** Fg. 89, Part. 721, Sub. 1, Zc. 2 Categoria A3 Cl.2, Cons. 5,5 vani Superficie catastale 171 mq Rendita € 426,08 Piano T-1

Il F87 M1175 S15 è stato originato dalla soppressione dei sub 7 e 8, entrambi di proprietà di **** Omissis **** dal 10/12/2012. Precedentemente entrambi i sub erano di proprietà di **** Omissis **** dall'impianto meccanografico del 30/06/1987

DATI CATASTALI

Catasto fabbricati (CF)		
Dati identificativi	**Dati di classamento**	

Sezione	Foglio	Part.	Sub.	Zona Cens.	Categoria	Classe	Consistenza	Superficie catastale	Rendita	Piano	Graffato
	89	721	1	2	A3	2	5,5 vani	171 mq	426,08 €	T-1	

Corrispondenza catastale

Sussiste corrispondenza tra lo stato dei luoghi e la planimetria catastale esistente nonché con quanto presente nell'atto di pignoramento.

STATO CONSERVATIVO

L'immobile è in discreto stato conservativo, sono presenti tracce di umidità e muffe, e sono necessari interventi di manutenzione ordinaria e straordinaria.

PARTI COMUNI

Sono parti comuni le scale condominiali.

CARATTERISTICHE COSTRUTTIVE PREVALENTI

L'edificio è costituto in muri in tufo e pietrame. Durante dei lavori recenti per consolidare sono stati realizzati dei plinti in cls armato e dei solai SAP tra il piano terra e il piano primo.
Sono presenti delle Pompe di Calore, non funzionanti.
L'acqua calda sanitaria è garantita da un boiler elettrico.
Gli infissi sono in legno vetro singolo i quali andrebbero sostituiti o manutenzionati.

Tra i lavori da eseguire risultano le nuove linee ABBANOA e ENEL e relativo posizionamento dei contatori all'esterno, sul muro perimetrale.

STATO DI OCCUPAZIONE

L'immobile è occupato dagli esecutati, ovvero **** Omissis **** con due figli minorenni, di cui uno con handicap grave ex art 3 comma 3 legge 104/1992, e con la figlia maggiorenne **** Omissis ****.

Nell'immobile è esercitata inoltre la professione di geometra della sig.ra **** Omissis ****.

PROVENIENZE VENTENNALI

Periodo	Proprietà	Atti			
Dal **01/07/1980** al **10/12/2012**	**** Omissis ****	**DENUNZIA (NEI PASSAGGI PER CAUSA DI MORTE)**			
		Rogante	**Data**	**Repertorio N°**	**Raccolta N°**
		Trascrizione			
		Presso	**Data**	**Reg. gen.**	**Reg. part.**
		Registrazione			
		Presso	**Data**	**Reg. N°**	**Vol. N°**
Dal **10/12/2012** al **29/03/2016**	**** Omissis ****	**DENUNZIA (NEI PASSAGGI PER CAUSA DI MORTE)**			
		Rogante	**Data**	**Repertorio N°**	**Raccolta N°**
		Trascrizione			
		Presso	**Data**	**Reg. gen.**	**Reg. part.**
		Registrazione			
		Presso	**Data**	**Reg. N°**	**Vol. N°**
Dal **29/03/2016**	**** Omissis ****	**ATTO TRA VIVI - COMPRAVENDITA**			
		Rogante	**Data**	**Repertorio N°**	**Raccolta N°**
		CARRIERI COSIMO	29/03/2016	49435	21733
		Trascrizione			
		Presso	**Data**	**Reg. gen.**	**Reg. part.**
		SASSARI	01/04/2016	4025	3083
		Registrazione			
		Presso	**Data**	**Reg. N°**	**Vol. N°**

Per quanto riguarda l'immobile oggetto di pignoramento:

- Sussiste continuità nelle trascrizioni per il ventennio precedente alla data di trascrizione del pignoramento;

- La situazione della proprietà antecedente il ventennio della trascrizione del pignoramento risulta invariata;
- La situazione della proprietà risulta variata.

E' PRESENTE UN PROVVEDIMENTO DI ASSEGNAZIONE IN GODIMENTO DELLA CASA FAMILIARE
Registro generale n. 9980
Registro particolare n. 7222
Presentazione n. 27 del 24/07/2018
A FAVORE DI **** Omissis ****

Il sig. **** Omissis **** è deceduto in data 24/06/2019, e i suoi eredi risultano gli attuali esecutati. Si fa presente che l'esecutato **** Omissis **** con R.G. 6596/2021 del Tribunale di Cagliari ha rinunciato all'eredità.

FORMALITÀ PREGIUDIZIEVOLI

Dalle visure ipotecarie effettuate presso l'Agenzia delle entrate di Sassari aggiornate al 13/05/2023, sono risultate le seguenti formalità pregiudizievoli:

Iscrizioni

- **IPOTECA VOLONTARIA** derivante da CONCESSIONE A GARANZIA DI MUTUO
  Iscritto a Sassari il 01/04/2016
  Reg. gen. 4026 - Reg. part. 581
  Quota: 1/1
  Importo: € 156.800,00
  A favore di **** Omissis ****
  Contro **** Omissis ****
  Capitale: € 78.400,00
  Percentuale interessi: 8,50 %
  Rogante: Carrieri Cosimo
  Data: 29/03/2016
  N° repertorio: 49436
  N° raccolta: 21734
  Note: Si fa presente che il sig. **** Omissis **** è deceduto, e risultano suoi eredi gli attuali esecutati.

Trascrizioni

- **PROVVEDIMENTO DI ASSEGNAZIONE IN GODIMENTO DELLA CASA FAMILIARE**
  Trascritto a Sassari il 24/07/2018
  Reg. gen. 9980 - Reg. part. 7222
  Quota: 1/1
  A favore di **** Omissis ****
  Contro **** Omissis ****
  Note: Si precisa che la sig.ra **** Omissis **** è attualmente tra i soggetti esecutati in quanto erede del sig. **** Omissis ****.

- **VERBALE DI PIGNORAMENTO IMMOBILI**
  Trascritto a Cagliari il 16/03/2022
  Reg. gen. 3784 - Reg. part. 2780
  Quota: 1/1
  A favore di **** Omissis ****
  Contro **** Omissis ****, **** Omissis ****, **** Omissis ****, **** Omissis ****, **** Omissis ****
  Formalità a carico della procedura

NORMATIVA URBANISTICA

L'appartamento è situato nella zona urbanistica B1.2, ovvero ambiti di sostanziale conferma dell'edificato esistente in zone urbanistiche sature o di parziale completamento.
Gli interventi sono orientati in prevalenza al consolidamento dell'impianto urbanistico, al mantenimento e al miglioramento dei caratteri architettonici degli edifici e della conformazione del tessuto urbano.

Destinazioni ammesse
d0 – d1 – d2.1 come da Allegato E2 Piano del Commercio per le relative sottozone, d2.2 - d2.3- d3 (con esclusione di d3.3, d3.4) – d3.5 (con esclusione di d3.5.12) - d4.1 – d9 – d10 – d11 – d12 – d13 – d14.
Categorie d'intervento
I1, I2, I3, I4, I4bis I5, I6, I7, I8, I9, I12

REGOLARITÀ EDILIZIA

L'immobile risulta regolare per la legge n° 47/1985. La costruzione è antecedente al 01/09/1967. Non sono presenti vincoli artistici, storici o alberghieri. Non sono presenti diritti demaniali o usi civici. L'immobile risulta agibile.

- Autorizzazione della Commissione Edilizia del 19/01/1948
- C.E. C/11/00152 con oggetto: "Accertamento di conformità fabbricato in via M. Marongiu ang. via Savoia"
- Suape 261434/2021

- Abitabilità 23/02/1956

Certificazioni energetiche e dichiarazioni di conformità

- Esiste il certificato energetico dell'immobile / APE.
- Non esiste la dichiarazione di conformità dell'impianto elettrico.
- Non esiste la dichiarazione di conformità dell'impianto termico.
- Non esiste la dichiarazione di conformità dell'impianto idrico.

Esiste corrispondenza tra lo stato dei luoghi e l'ultimo progetto autorizzato, ovvero la C/11/00152

VINCOLI OD ONERI CONDOMINIALI

Non sono presenti vincoli od oneri condominiali.

Servitù relativa al terrazzo da parte del sub 3.

STIMA / FORMAZIONE LOTTI

Il valore commerciale dei beni pignorati è stato determinato sulla base delle seguenti variabili: ubicazione dell'immobile, caratteristiche e peculiarità della zona oltre che dalla facilità di raggiungimento, stato di manutenzione, conservazione, finitura e confort, consistenza, regolarità geometrica della forma, sussistenza di eventuali vincoli e servitù passive o attive, suoi dati metrici ed infine la situazione del mercato e della domanda e dell'offerta. Tutti questi elementi, in coesistenza all'esame di alcune documentazioni ufficiali ed esperita un'attenta e puntuale ricerca volta a determinare l'attuale valore di mercato indicando sia il valore per metro quadro che il valore complessivo, tenendo conto altresì di eventuali adeguamenti e correzioni della stima, hanno concorso a determinare il più probabile valore di compravendita da attribuire agli immobili oggetto della stima.

Lo scrivente ha ritenuto opportuno procedere alla formazione di un lotto unico cosi costituito:

- **Bene N° 1** - Appartamento ubicato a Sassari (SS) - Via Monsignor Marongiu Delrio 29
  L'immobile oggetto di pignoramento si trova all'interno di un fabbricato di maggior consistenza distribuito su tre livelli fuori terra e che ha accesso dalla via Marongiu; si affaccia inoltre sulla via Savoia. Il bene pignorato è costituito da: - una porzione di appartamento al piano terra, con accesso indipendente dal piano stradale, composto da una camera un wc e un disimpegno; questa porzione risulta in grezzo ed è utilizzata come deposito. - un appartamento al piano primo composto da cucina, tre camere da letto, un bagno e un disimpegno; completa il bene un terrazzino per il quale l'appartamento censito al sub 3 ha una servitù per stendere (Atto di compravendita rep. 16722 del 22/11/1966). L'appartamento è in discrete condizioni, ovvero presenta evidenti tracce di umidità nelle pareti. Si accede all'immobile mediante una scala esterna condominiale.
  Identificato al catasto Fabbricati - Fg. 89, Part. 721, Sub. 1, Zc. 2, Categoria A3
  L'immobile viene posto in vendita per il diritto di Proprietà (1/1)
  Valore di stima del bene: € 215.373,00
  Per arrivare all'importo stabilito di 1.220 €/mq sono stati utilizzati differenti metodologie:

  1. Comparazione diretta
  La valutazione dei cespiti è stata effettuata per confronto con altri beni aventi stesse caratteristiche intrinseche ed estrinseche, e ubicati nella zona di interesse, da cui è emerso che il valore medio è pari a 1.345 €/mq.
  E' stato poi calcolato il coefficiente di merito che viene individuato in 0,92 viste le caratteristiche qualitative e quantitative. E in particolare:

1DISPONIBILITA' - Libero o occupato dal proprietario1,00
2EFFICIENZA ENERGETICA - Classe G0,94
3FINESTRATURA - Con vetri ordinari0,98
4FINITURA - Ordinaria1,00
5LIVELLI DI PIANO - EDIFICI SENZA ASCENSORE - Piano primo1,00
6QUALITA' EDIFICIO - Civile1,00
7TIPOLOGIA EDILIZIA - Edificio plurifamiliare fino a tre piani fuori terra1,00

Coefficiente globale0,92

Si è fatto quindi riferimento al "Codice delle Valutazioni Immobiliari. Italian Property Valuation Standard" edito da Tecnoborsa, il quale definisce la formula matematica:
Valore di mercato (V) = Superficie commerciale (SuC) * Quotazione al metro quadro (Q) * Coefficienti di merito (CoM)
V = 175,10 mq * 1.345 €/mq * 0,92 = 216.668,74 €
valore unitario finale €/mq = 216.668,74 € / 175,10 mq = 1.237,40 €/mq

2. Valore OMI
Si è fatto riferimento ai dati forniti dall'Osservatorio del Mercato Immobiliare dell'Agenzia delle Entrate (OMI), che in particolare per i fabbricati conserva un buon grado di affidabilità, in quanto semestralmente monitora la compravendita dei fabbricati sull'intero territorio italiano e li suddivide per aree geografiche.
L'agenzia delle Entrate propone per le abitazioni civili con uno stato conservativo normale, nel Comune di Sassari, un range di valori che varia in base alla zona OMI. La zona OMI di riferimento è la C1 (Semicentrale/CAPPUCCINI - LUNA E SOLE - LU FANGAZZU), dove abbiamo un valore compreso tra 1.300 €/mq e 1.750 €/mq.

Per la determinazione del valore normale unitario OMI, , si fa riferimento alla seguente formula:
Valore normale unitario = (Valore OMI max + Valore OMI minimo)/2

Valore minimo OMI (2° semestre 2022) 1.300,00 €
Valore massimo OMI (2° semestre 2022) 1.750,00 €
Valore medio unitario di mercato (€./m2) 1.525,00 €

C1=1,00
C2=0,833
C=C1XC2=0,833

Valore normale [(Max + Min) / 2]:1.435,00 €
Valore corretto [Valore normale x C]:1.195,36 €
Valore stima OMI [Valore corretto x Sup. lorda]: 209.307,54 €
valore unitario finale €/mq = 209.307,54 € / 175,10 mq = 1.195,36 €/mq

3. Valore medio di mercato
Sempre facendo riferimento ai valori OMI, e prendendo questa volta il valore medio pari a (1.300 + 1.750)/2 = 1.525 €/mq e facendo sempre riferimento alla formula
Valore di mercato (V) = Superficie commerciale (SuC) * Quotazione al metro quadro (Q) * Coefficienti di merito (CoM)
Abbiamo che il valore medio di mercato è pari a

V = 175,10 mq mq * 1.525 €/mq * 0,92 = 245.665,30 €
valore unitario finale €/mq = 245.665,30 € / 175,10 mq = 1.403,00 €/mq

Facendo quindi una media tra i tre valori ottenuti abbiamo che il più probabile valore di mercato unitario è attualmente pari a 1.278,59 €/mq

4. MCA
Al metodo del confronto diretto affianchiamo la metodologia del Market Comparison Approach (MCA), metodo che consente di stimare il valore di un immobile mediante il confronto tra lo stesso ed altri immobili simili presi a confronto e contrattati in tempi non troppo lontani e di prezzi e caratteristiche noti e ricadenti nello stesso segmento di mercato dell'immobile da valutare.
valore unitario €/mq = 205.654,59 € / 175,10 mq = 1.174,50 €/mq

Abbiamo due valori abbastanza simili, e per avere un valore ancora più preciso, andiamo a fare una media tra il valore ottenuto dalla comparazione diretta, pari a 1.278,59 €/mq, e il valore stimato con metodologia MCA, pari a 1.174,50 €/mq abbiamo che
Valore unitario = (1.278,59 €/mq + 1.174,50 €/mq)/2 = 1.226,54 €/mq, che arrotondiamo a 1.230 €/mq

Identificativo corpo	Superficie convenzionale	Valore unitario	Valore complessivo	Quota in vendita	Totale
Bene N° 1 - Appartamento Sassari (SS) - Via Monsignor Marongiu Delrio 29	175,10 mq	1.230,00 €/mq	€ 215.373,00	100,00%	€ 215.373,00
				Valore di stima:	€ 215.373,00

Valore di stima: € 215.373,00

Valore finale di stima: **€ 215.373,00**

Assolto il proprio mandato, il sottoscritto Esperto ex art. 568 c.p.c. deposita la relazione di stima presso questo Spettabile Tribunale, tanto in assolvimento dell'incarico conferitogli dalla S.V. e resta a disposizione per eventuali chiarimenti.

Alghero, li 31/05/2023

L'Esperto ex art. 568 c.p.c.
Arch. Cocco Paola

ELENCO ALLEGATI:

- ✓ N° 5 Concessione edilizia - Accesso agli atti
- ✓ N° 1 Planimetrie catastali
- ✓ N° 4 Altri allegati - Ipocatastale
- ✓ N° 1 Altri allegati - Atto vicino
- ✓ N° 1 Altri allegati - Atto di acquisto
- ✓ N° 1 Altri allegati - Rinuncia all'eredità
- ✓ N° 36 Altri allegati - Foto
- ✓ N° 1 Altri allegati - APE

RIEPILOGO BANDO D'ASTA

LOTTO UNICO

- **Bene N° 1** - Appartamento ubicato a Sassari (SS) - Via Monsignor Marongiu Delrio 29
  L'immobile oggetto di pignoramento si trova all'interno di un fabbricato di maggior consistenza distribuito su tre livelli fuori terra e che ha accesso dalla via Marongiu; si affaccia inoltre sulla via Savoia. Il bene pignorato è costituito da: - una porzione di appartamento al piano terra, con accesso indipendente dal piano stradale, composto da una camera un wc e un disimpegno; questa porzione risulta in grezzo ed è utilizzata come deposito. - un appartamento al piano primo composto da cucina, tre camere da letto, un bagno e un disimpegno; completa il bene un terrazzino per il quale l'appartamento censito al sub 3 ha una servitù per stendere (Atto di compravendita rep. 16722 del 22/11/1966). L'appartamento è in discrete condizioni, ovvero presenta evidenti tracce di umidità nelle pareti. Si accede all'immobile mediante una scala esterna condominiale. Identificato al catasto Fabbricati - Fg. 89, Part. 721, Sub. 1, Zc. 2, Categoria A3 L'immobile viene posto in vendita per il diritto di Proprietà (1/1) Destinazione urbanistica: L'appartamento è situato nella zona urbanistica B1.2, ovvero ambiti di sostanziale conferma dell'edificato esistente in zone urbanistiche sature o di parziale completamento. Gli interventi sono orientati in prevalenza al consolidamento dell'impianto urbanistico, al mantenimento e al miglioramento dei caratteri architettonici degli edifici e della conformazione del tessuto urbano. Destinazioni ammesse d0 – d1 – d2.1 come da Allegato E2 Piano del Commercio per le relative sottozone, d2.2 - d2.3- d3 (con esclusione di d3.3, d3.4) – d3.5 (con esclusione di d3.5.12) - d4.1 – d9 – d10 – d11 – d12 – d13 – d14. Categorie d'intervento I1, I2, I3, I4, I4bis I5, I6, I7, I8, I9, I12

Prezzo base d'asta: **€ 215.373,00**

SCHEMA RIASSUNTIVO
ESECUZIONE IMMOBILIARE 26/2022 DEL R.G.E.

LOTTO UNICO - PREZZO BASE D'ASTA: € 215.373,00

Bene N° 1 - Appartamento			
Ubicazione:	Sassari (SS) - Via Monsignor Marongiu Delrio 29		
Diritto reale:	Proprietà	**Quota**	1/1
Tipologia immobile:	Appartamento Identificato al catasto Fabbricati - Fg. 89, Part. 721, Sub. 1, Zc. 2, Categoria A3	**Superficie**	175,10 mq
Stato conservativo:	L'immobile è in discreto stato conservativo, sono presenti tracce di umidità e muffe, e sono necessari interventi di manutenzione ordinaria e straordinaria.		
Descrizione:	L'immobile oggetto di pignoramento si trova all'interno di un fabbricato di maggior consistenza distribuito su tre livelli fuori terra e che ha accesso dalla via Marongiu; si affaccia inoltre sulla via Savoia. Il bene pignorato è costituito da: - una porzione di appartamento al piano terra, con accesso indipendente dal piano stradale, composto da una camera un wc e un disimpegno; questa porzione risulta in grezzo ed è utilizzata come deposito. - un appartamento al piano primo composto da cucina, tre camere da letto, un bagno e un disimpegno; completa il bene un terrazzino per il quale l'appartamento censito al sub 3 ha una servitù per stendere (Atto di compravendita rep. 16722 del 22/11/1966). L'appartamento è in discrete condizioni, ovvero presenta evidenti tracce di umidità nelle pareti. Si accede all'immobile mediante una scala esterna condominiale.		
Vendita soggetta a IVA:	NO		
Continuità trascrizioni ex art. 2650 c.c.:	SI		
Stato di occupazione:	L'immobile è occupato dagli esecutati, ovvero **** Omissis **** con due figli minorenni, di cui uno con handicap grave ex art 3 comma 3 legge 104/1992, e con la figlia maggiorenne **** Omissis ****. Nell'immobile è esercitata inoltre la professione di geometra della sig.ra **** Omissis ****.		

FORMALITÀ DA CANCELLARE CON IL DECRETO DI TRASFERIMENTO

- **VERBALE DI PIGNORAMENTO IMMOBILI**
  Trascritto a Cagliari il 16/03/2022
  Reg. gen. 3784 - Reg. part. 2780
  Quota: 1/1
  A favore di **** Omissis ****
  Contro **** Omissis ****, **** Omissis ****, **** Omissis ****, **** Omissis ****, **** Omissis ****
  Formalità a carico della procedura

ATTESTATO DI PRESTAZIONE ENERGETICA DEGLI EDIFICI

VALIDO FINO AL: 2/2/2026

DATI GENERALI

Destinazione d'uso
[X] Residenziale
[] Non residenziale

Classificazione D.P.R. 412/93:E1.1

Oggetto dell'attestato
[] Intero edificio
[X] Unità immobiliare
[] Gruppo di unità immobiliari

Numero di unità immobiliari di cui è composto l'edificio: 3

[] Nuova costruzione
[X] Passaggio di proprietà
[] Locazione
[] Ristrutturazione importante
[] Riqualificazione energetica
[] Altro:

All B
al Rep. 49435/21733

Dati identificativi

Regione: **SARDEGNA**
Comune: **Sassari**
Indirizzo: **Via Mons. Marongiu Del Rio, 29**
Piano: **T-1°**
Interno: **N.D.**
Coordinate GIS:**40.730879N 8.5676824E**

Zona climatica: **C**
Anno di costruzione:**1948**
Superficie utile riscaldata (m^2):**138.88**
Superficie utile raffrescata (m^2): **0.00**
Volume lordo riscaldato (m^3): **556.22**
Volume lordo raffrescato (m^3): **0.00**

Comune catastale			I452								Sezione	N.D.		Foglio	87				Particella	1175				
Subalterni	da	-	a	-		da	-	a	-		da	-	a	-		da	-	a	-					
Altri subalterni	15	-	-	-	-	-	-	-	-	-	-	-	-	-	-	-	-	-	-	-	-	-	-	-

Servizi energetici presenti

[X] Climatizzazione invernale
[] Climatizzazione estiva
[] Ventilazione meccanica
[X] Prod. acqua calda sanitaria
[] Illuminazione
[] Trasporto di persone o cose

PRESTAZIONE ENERGETICA GLOBALE E DEL FABBRICATO

La sezione riporta l'indice di prestazione energetica globale non rinnovabile in funzione del fabbricato e dei servizi energetici presenti, nonché la prestazione energetica del fabbricato, al netto del rendimento degli impianti presenti.

Prestazione energetica del fabbricato



Prestazione energetica globale

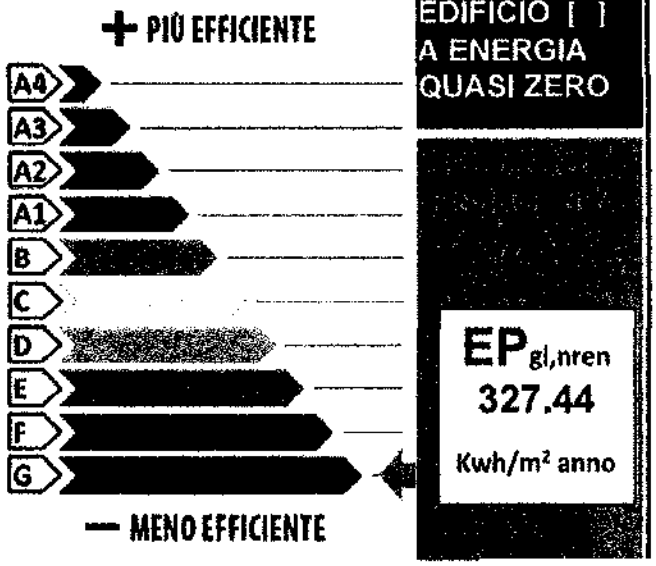

Riferimenti

Gli immobili simili a questo avrebbero in media la seguente classificazione:

Se nuovi:

Se esistenti:



ATTESTATO DI PRESTAZIONE ENERGETICA DEGLI EDIFICI

VALIDO FINO AL: 2/2/2026

PRESTAZIONE ENERGETICA DEGLI IMPIANTI E CONSUMI STIMATI

La sezione riporta l'indice di prestazione energetica rinnovabile e non rinnovabile, nonché una stima dell'energia consumata annualmente dall'immobile secondo un uso standard.

Prestazioni energetiche degli impianti e stima dei consumi di energia

	FONTI ENERGETICHE UTILIZZATE	Quantità annua consumata in uso standard (specificare unità di misura)	Indice di prestazione energetica globali ed emissioni
[X]	Energia elettrica da rete	14406 KWh	Indice della prestazione energetica non rinnovabile EPgl,nren KWh/m² anno 327.44
[]	Gas naturale		
[]	GPL		
[]	Carbone		
[]	Gasolio e Olio combustibile		
[]	Biomasse solide		Indice della prestazione energetica rinnovabile EPgl,ren KWh/m² anno 78.92
[]	Biomasse liquide		
[]	Biomasse gassose		
[]	Solare fotovoltaico		
[]	Solare termico		
[]	Eolico		Emissioni di CO_2 Kg/m² anno 194.71
[]	Teleriscaldamento		
[]	Teleraffrescamento		
[]	Altro (specificare)		

RACCOMANDAZIONI

La sezione riporta gli interventi migliorativi e la stima dei risultati conseguibili, con il singolo intervento o con la realizzazione dell'insieme di essi, esprimendo una valutazione di massima del potenziale di miglioramento dell'edificio o immobile oggetto dell'attestato di prestazione energetica.

RIQUALIFICAZIONE ENERGETICA E RISTRUTTURAZIONE IMPORTANTE

INTERVENTI RACCOMANDATI E RISULTATI CONSEGUIBILI

Codice	TIPO DI INTERVENTO RACCOMANDATO	Comporta una Ristrutturazione importante	Tempo di ritorno dell'investimento anni	Classe energetica raggiungibile con l'intervento (EPgl,nren KWh/m² anno)	CLASSE ENERGETICA raggiungibile se si realizzano tutti gli interventi raccomandati
REN1	Isolamento pareti perimetrali esterne con cappotto+ sostituzione infissi+installazione impianto di risc. e cond. a pompe di calore	Si	9.90	E / 126.88	E 126.88 KWh/m² anno
-	-	-	-	-	
-	-	-	-	-	
-	-	-	-	-	
-	-	-	-	-	
-	-	-	-		

ATTESTATO DI PRESTAZIONE ENERGETICA DEGLI EDIFICI

VALIDO FINO AL: 2/2/2026

ALTRI DATI ENERGETICI GENERALI

Energia esportata	0.00 KWh/anno	Vettore energetico: -

ALTRI DATI DI DETTAGLIO DEL FABBRICATO

V - Volume riscaldato	556.22	m^3
S - Superficie disperdente	456.10	m^2
Rapporto S/V	0.82	
$EP_{H,nd}$	88.56	KWh/m^2anno
$A_{sol,est}/A_{sup\ utile}$	0.07	-
Y_{IE}	0.85	W/m^2K

DATI DI DETTAGLIO DEGLI IMPIANTI

Servizio energetico	Tipo di impianto	Anno di installazione	Codice catasto regionale impianti termici	Vettore energetico utilizzato	Potenza nominale KW	Efficienza media stagionale		EPren	EPnren
Climatizzazione invernale	Generatore Standard simulato in quanto assente	-	-	Elettricità	6.00	0.31	η_H	69.53	288.46
	-	-	-	-	-				
Climatizzazione estiva	-	-	-	-	-	-	η_c	-	-
	-	-	-	-	-				
Prod. acqua calda sanitaria	Boiler elettrico ad accumulo	2010	-	Elettricità	1.20	0.39	η_w	9.39	38.98
Impianti combinati									
Prod. da fonti rinnovabili	-	-	-	-	-			-	
	-	-	-	-	-			-	
Ventilazione meccanica	-	-	-	-	-	-	-	-	-
Illuminazione	-	-	-	-	-	-	-	-	-
Trasporto di persone o cose	-	-	-	-	-	-	-	-	-
	-	-	-	-	-	-	-	-	-

ATTESTATO DI PRESTAZIONE ENERGETICA DEGLI EDIFICI

VALIDO FINO AL: 2/2/2026

INFORMAZIONI SUL MIGLIORAMENTO DELLA PRESTAZIONE ENERGETICA

La sezione riporta informazioni sulle opportunità, anche in termini di strumenti di sostegno nazionali o locali, legate all'esecuzione di diagnosi energetiche e interventi di riqualificazione energetica, comprese le ristrutturazioni importanti.

La Legge di Stabilità 2015 (legge n. 190 del 23 dicembre 2014) ha prorogato al 31 dicembre 2015 la possibilità di usufruire della detrazione Irpef (50%) per ristrutturazioni su edifici residenziali, confermando il limite massimo di spesa di 96.000 euro per unità immobiliare.

SOGGETTO CERTIFICATORE

[] Ente/Organismo pubblico	[X] Tecnico abilitato	[] Organismo/Società

Nome e Cognome / Denominazione	Angelo Michele Fabio Seghenzi
Indirizzo	Via Monte Grappa 19 Ploaghe (SS)
E-mail	angeloseghenzi@libero.it
Telefono	
Titolo	Geometra
Ordine/iscrizione	Collegio Geometri e Geometri laureati della provincia di Sassari
Dichiarazione di indipendenza	Ai sensi degli artt.359 e 481 del C.P.,ed ai sensi dell'art. 3 del D.P.R. 75/2013, il sottoscritto dichiara l'assenza di conflitto di interessi, ovvero di non coinvolgimento diretto o indiretto con i produttori dei materiali e dei componenti dell'edifico da certificare nonche' rispetto ai vantaggi che possano derivarne al richiedente (come richiesto dall'art. III punto 2.3.b) del D.Lgs. n. 115/08), che in ogni caso non s' ne' coniuge ne' parente fino al quarto grado del sottoscritto.
Informazioni aggiuntive	N.D.

SOPRALLUOGHI E DATI DI INGRESSO

E' stato eseguito almeno un sopralluogo/rilievo sull'edificio obbligatorio per la redazione del presente APE?	SI

SOFTWARE UTILIZZATO

Il software utilizzato risponde ai requisiti di rispondenza e garanzia di scostamento massimo dei risultati conseguiti rispetto ai valori ottenuti per mezzo dello strumento di riferimento nazionale?	SI
Ai fini della redazione del presente attestato è stato utilizzato un software che impieghi un metodo di calcolo semplificato?	No

Il presente attestato è reso dal sottoscritto, in forma di dichiarazione sostitutiva di atto notorio ai sensi dell'articolo 47 del D.P.R. 445/2000 e dell'articolo 15, comma 1 del D. Lgs 192/2005 così come modificato dall'articolo 12 del D.L. 63/2013

Data di emissione 02/02/2016 Firma e timbro del tecnico o firma digitale

Iscrizione Albo n. 2834

ATTESTATO DI PRESTAZIONE ENERGETICA DEGLI EDIFICI

VALIDO FINO AL: 2/2/2026

LEGENDA E NOTE PER LA COMPILAZIONE

Il presente documento attesta **la prestazione e la classe energetica** dell'edificio o dell'unità immobiliare, ovvero la quantità di energia necessaria ad assicurare il comfort attraverso i diversi servizi erogati dai sistemi tecnici presenti, in condizioni convenzionali d'uso. Al fine di individuare le potenzialità di miglioramento della prestazione energetica, l'attestato riporta informazioni specifiche sulle prestazioni energetiche del fabbricato e degli impianti. Viene altresì indicata la classe energetica più elevata raggiungibile in caso di realizzazione delle misure migliorative consigliate, così come descritte nella sezione **"raccomandazioni"** (pag. 2).

PRIMA PAGINA

Informazioni generali : tra le informazioni generali è riportata la motivazione alla base della redazione dell'APE. Nell'ambito del periodo di validità, ciò non preclude l'uso dell'APE stesso per i fini di legge, anche se differenti da quelli ivi indicati.
Prestazione energetica globale (EPgl,nren) : fabbisogno annuale di energia primaria non rinnovabile relativa a tutti i servizi erogati dai sistemi tecnici presenti, in base al quale è identificata la classe di prestazione dell'edificio in una scala da A4 (edificio più efficiente) a G (edificio meno efficiente).
Prestazione energetica del fabbricato: indice qualitativo del fabbisogno di energia necessario per il soddisfacimento del confort interno, indipendente dalla tipologia e dal rendimento degli impianti presenti. Tale indice dà un'indicazione di come l'edificio, d'estate e d'inverno, isola termicamente gli ambienti interni rispetto all'ambiente esterno. La scala di valutazione qualitativa utilizzata osserva il seguente criterio:

QUALITA' ALTA	QUALITA' MEDIA	QUALITA' BASSA

I valori di soglia per la definizione del livello di qualità, suddivisi per tipo di indicatore, sono riportati nelle Linee guida per l'attestazione energetica degli edifici di cui al decreto previsto dall'articolo 6, comma 12 del d.lgs. 192/2005.
Edificio a energia quasi zero: edificio ad altissima prestazione energetica, calcolata conformemente alle disposizioni del decreto legislativo 19 agosto 2005, n. 192 e del decreto ministeriale sui requisiti minimi previsto dall'articolo 4, comma 1 del d.lgs. 192/2005. Il fabbisogno energetico molto basso o quasi nullo è coperto in misura significativa da energia da fonti rinnovabili, prodotta all'interno del confine del sistema (in situ). Una spunta sull'apposito spazio adiacente alla scala di classificazione indica l'appartenenza dell'edificio oggetto dell'APE a questa ca tegoria.
Riferimenti: raffronto con l'indice di prestazione globale non rinnovabile di un edificio simile ma dotato dei requisiti minimi degli edifici nuovi, nonché con la media degli indici di prestazione degli edifici esistenti simili, ovvero contraddistinti da stessa tipologia d'uso, tipologia costruttiva, zona climatica, dimensioni ed esposizione di quello oggetto dell'attestato.

SECONDA PAGINA

Prestazioni energetiche degli impianti e consumi stimati: la sezione riporta l'indice di prestazione energetica rinnovabile e non rinnovabile dell'immobile oggetto di attestazione. Tali indici informano sulla percentuale di energia rinnovabile utilizzata dall'immobile rispetto al totale. La sezione riporta infine una stima del quantitativo di energia consumata annualmente dall'immobile secondo un uso standard, suddivisi per tipologia di fonte energetica utilizzata.
Raccomandazioni: di seguito si riporta la tabella che classifica le tipologie di intervento raccomandate per la riqualificazione energetica e la ristrutturazione importante.

RIQUALIFICAZIONE ENERGETICA E RISTRUTTURAZIONE IMPORTANTE EDIFICIO/UNITA' IMMOBILIARE - Tabella dei Codici

Codici	TIPO DI INTERVENTO
REN1	FABBRICATO - INVOLUCRO OPACO
REN2	FABBRICATO - INVOLUCRO TRASPARENTE
REN3	IMPIANTO CLIMATIZZAZIONE - INVERNO
REN4	IMPIANTO CLIMATIZZAZIONE - ESTATE
REN5	ALTRI IMPIANTI
REN6	FONTI RINNOVABILI

TERZA PAGINA

La terza pagina riporta la quantità di energia prodotta in situ ed esportata annualmente, nonché la sua tipologia.
Riporta infine, suddivise in due sezioni relative rispettivamente al fabbricato e agli impianti, i dati di maggior dettaglio alla base del calcolo.