TRIBUNALE DI SASSARI

SEZIONE EE.II.

Perizia dell'Esperto ex art. 568 c.p.c. Geom. Mulas Mario, nell'Esecuzione Immobiliare 52/2024 del R.G.E.

promossa da

******* Omissis *******

******* Omissis *******

contro

******* Omissis *******

Firmato Da: MULAS MARIO Emesso Da: NAMIRIAL CA FIRMA QUALIFICATA Serial#: 18563ece0fed15e9

SOMMARIO

Incarico 3
Premessa 3
Descrizione 3
Lotto Unico 3
Completezza documentazione ex art. 567 3
Titolarità 3
Confini 4
Consistenza 4
Cronistoria Dati Catastali 4
Dati Catastali 4
Precisazioni 5
Patti 5
Stato conservativo 5
Parti Comuni 5
Servitù, censo, livello, usi civici 5
Caratteristiche costruttive prevalenti 5
Stato di occupazione 6
Provenienze Ventennali 6
Formalità pregiudizievoli 6
Normativa urbanistica 7
Regolarità edilizia 7
Vincoli od oneri condominiali 8
Stima / Formazione lotti 8
Riepilogo bando d'asta 10
Lotto Unico 10
Schema riassuntivo Esecuzione Immobiliare 52/2024 del R.G.E. 11
Lotto Unico 11
Formalità da cancellare con il decreto di trasferimento 12

Firmato Da: MULAS MARIO Emesso Da: NAMIRIAL CA FIRMA QUALIFICATA Serial#: 18563ece0fed15e9

INCARICO

In data 25/10/2024, il sottoscritto Geom. Mulas Mario, con studio in Via Giacomo Chessa, 10 - 07100 - Sassari (SS), email mulasmario@virgilio.it, PEC g.mulas.mario@pec.it, Tel. 339 5927961, veniva nominato Esperto ex art. 568 c.p.c., accettava l'incarico e prestava giuramento di rito.

PREMESSA

I beni oggetto di pignoramento sono costituiti dai seguenti immobili:

- **Bene N° 1** - Appartamento ubicato a Ozieri (SS) - Via Giorgio Asproni n.5

DESCRIZIONE

Appartamento sito al secondo piano di Via Asproni n.5 nel centro urbano di Ozieri, composto da:
- ingresso;
- cucina-soggiorno;
- camera;
- bagno;
- terrazzo.

L'immobile non risulta realizzato in regime di edilizia residenziale pubblica convenzionata e agevolata e finanziata in tutto o in parte con risorse pubbliche, con vincoli ancora vigenti a carico del proprietario debitore.

LOTTO UNICO

Il lotto è formato dai seguenti beni:

- **Bene N° 1** - Appartamento ubicato a Ozieri (SS) - Via Giorgio Asproni n.5

COMPLETEZZA DOCUMENTAZIONE EX ART. 567

Si attesta che la documentazione di cui all'art. 567 c.p.c., comma 2 risulta completa.

TITOLARITÀ

L'immobile oggetto dell'esecuzione, appartiene ai seguenti esecutati:

- **** Omissis **** (Proprietà 1/1)

L'immobile viene posto in vendita per i seguenti diritti:

- **** Omissis **** (Proprietà 1/1)

Firmato Da: MULAS MARIO Emesso Da: NAMIRIAL CA FIRMA QUALIFICATA Serial#: 18563ece0fed15e9

CONFINI

L'immobile confina con:
- Nord mapp. 1340-1341;
- Sud mapp. 1345;
- Ovest mapp. 1339-1344;
- Est Via Giorgio Asproni.

CONSISTENZA

Destinazione	Superficie Netta	Superficie Lorda	Coefficiente	Superficie Convenzionale	Altezza	Piano
Abitazione	44,00 mq	44,00 mq	1	44,00 mq	3,00 m	2
Balcone scoperto	3,50 mq	3,50 mq	0,25	0,88 mq	0,00 m	2
			Totale superficie convenzionale:	**44,88 mq**		
			Incidenza condominiale:	**0,00**	**%**	
			Superficie convenzionale complessiva:	**44,88 mq**		

I beni non sono comodamente divisibili in natura.

CRONISTORIA DATI CATASTALI

Periodo	Proprietà	Dati catastali
Dal **17/02/1999** al **08/12/2024**	**** Omissis ****	Catasto **Fabbricati** Fg. 68, Part. 1345, Sub. 7 Categoria A3 Cl.2, Cons. 2,5 Superficie catastale 44 mq Rendita € 180,76 Piano 2

DATI CATASTALI

Catasto fabbricati (CF)											
Dati identificativi				Dati di classamento							
Sezione	Foglio	Part.	Sub.	Zona Cens.	Categoria	Classe	Consistenza	Superficie catastale	Rendita	Piano	Graffato

Firmato Da: MULAS MARIO Emesso Da: NAMIRIAL CA FIRMA QUALIFICATA Serial#: 18563ece0fed15e9

	68	1342	7		A3	2	2,5	44 mq	180,76 €	2	

Corrispondenza catastale

Sussiste corrispondenza tra lo stato dei luoghi e la planimetria catastale esistente nonché con quanto presente nell'atto di pignoramento.

PRECISAZIONI

Si precisa che è presente un sottotetto al quale non è stato possibile accedere in fase di sopralluogo.

PATTI

Non sussistono patti.

STATO CONSERVATIVO

Allo stato attuale l'unità immobiliare si trova in discrete condizioni con alcune opere da eseguirsi sui cornicioni esterni per evitare situazioni di pericolo.

PARTI COMUNI

Le parti in comune riguardano l'ingresso distinto al NCEU al foglio 68 part.1342 sub.9

SERVITÙ, CENSO, LIVELLO, USI CIVICI

Non sussistono servitù

CARATTERISTICHE COSTRUTTIVE PREVALENTI

- Esposizione Sud;
- altezza interna utile 3,00m;
- strutture verticali in muratura di pietrame a sacco;
- solai in latero-cemento;
- copertura a falde in legno;
- manto di copertura in tegole tipo cotto;
- pareti esterne ed interne rivestite con intonaco di tipo civile;
- pavimentazione interna di tipo monocottura;
- infissi esterni in legno;
- porte interne tamburate.

Firmato Da: MULAS MARIO Emesso Da: NAMIRIAL CA FIRMA QUALIFICATA Serial#: 18563ece0fed15e9

STATO DI OCCUPAZIONE

L'immobile risulta occupato dall'esecutato **** Omissis ****

PROVENIENZE VENTENNALI

Periodo	Proprietà	Atti			
Dal **29/07/1999** al **08/12/2024**	**** Omissis ****	.			
		Rogante	**Data**	**Repertorio N°**	**Raccolta N°**
		Notaio Castelli	29/07/1999	100546	
		Trascrizione			
		Presso	**Data**	**Reg. gen.**	**Reg. part.**
		Registrazione			
		Presso	**Data**	**Reg. N°**	**Vol. N°**

Per quanto riguarda l'immobile oggetto di pignoramento:

- Sussiste continuità nelle trascrizioni per il ventennio precedente alla data di trascrizione del pignoramento;
- La situazione della proprietà antecedente il ventennio della trascrizione del pignoramento risulta invariata;
- La situazione della proprietà risulta attualmente invariata.

FORMALITÀ PREGIUDIZIEVOLI

Dalle visure ipotecarie effettuate presso l'Agenzia delle entrate di Sassari aggiornate al 07/05/2024, sono risultate le seguenti formalità pregiudizievoli:

Annotazioni a iscrizioni

- **Ipoteca Giudiziale**
  Iscritto a Sassari il 01/08/2019
  Reg. gen. 11137 - Reg. part. 1487

Firmato Da: MULAS MARIO Emesso Da: NAMIRIAL CA FIRMA QUALIFICATA Serial#: 18563ece0fed15e9

Quota: 1/1
A favore di **** Omissis ****
Contro **** Omissis ****
Formalità a carico della procedura

Annotazioni a trascrizioni

- **costituzione in vincolo**
  Trascritto a Sassari il 06/08/1999
  Reg. gen. 11977 - Reg. part. 7816
  Quota: 1/1
  A favore di **** Omissis ****
  Contro **** Omissis ****
  Formalità a carico della procedura
- **Atto Giudiziario**
  Trascritto a Sassari il 11/04/2024
  Reg. gen. 7410 - Reg. part. 6009
  Quota: 1/1
  A favore di **** Omissis ****
  Contro **** Omissis ****
  Formalità a carico della procedura

NORMATIVA URBANISTICA

L'unità immobiliare è situata nel Centro Matrice del Comune di Ozieri, meglio definito come Zona A

REGOLARITÀ EDILIZIA

L'immobile risulta regolare per la legge n° 47/1985. La costruzione è antecedente al 01/09/1967. Non sono presenti vincoli artistici, storici o alberghieri. Non sono presenti diritti demaniali o usi civici. L'immobile non risulta agibile.

Concessione edilizia N. 151 del 10/10/94.

Certificazioni energetiche e dichiarazioni di conformità

- Non esiste il certificato energetico dell'immobile / APE.
- Non esiste la dichiarazione di conformità dell'impianto elettrico.
- Non esiste la dichiarazione di conformità dell'impianto termico.
- Non esiste la dichiarazione di conformità dell'impianto idrico.

Firmato Da: MULAS MARIO Emesso Da: NAMIRIAL CA FIRMA QUALIFICATA Serial#: 18563ece0fed15e9

VINCOLI OD ONERI CONDOMINIALI

Non sono presenti vincoli od oneri condominiali.

Non sussistono oneri condominiale in quanto, nello stabile, non esiste un condominio.

STIMA / FORMAZIONE LOTTI

Lo scrivente ha ritenuto opportuno procedere alla formazione di un lotto unico cosi costituito:

- **Bene N° 1** - Appartamento ubicato a Ozieri (SS) - Via Giorgio Asproni n.5
  Appartamento sito al secondo piano di Via Asproni n.5 nel centro urbano di Ozieri, composto da: - ingresso; - cucina-soggiorno; - camera; - bagno; - terrazzo.
  Identificato al catasto Fabbricati - Fg. 68, Part. 1342, Sub. 7, Categoria A3
  L'immobile viene posto in vendita per il diritto di Proprietà (1/1)
  Valore di stima del bene: € 35.904,00

Identificativo corpo	Superficie convenzionale	Valore unitario	Valore complessivo	Quota in vendita	Totale
Bene N° 1 - Appartamento Ozieri (SS) - Via Giorgio Asproni n.5	44,88 mq	800,00 €/mq	€ 35.904,00	100,00%	€ 35.904,00
				Valore di stima:	€ 35.904,00

Assolto il proprio mandato, il sottoscritto Esperto ex art. 568 c.p.c. deposita la relazione di stima presso questo Spettabile Tribunale, tanto in assolvimento dell'incarico conferitogli dalla S.V. e resta a disposizione per eventuali chiarimenti.

Sassari, li 08/12/2024

Firmato Da: MULAS MARIO Emesso Da: NAMIRIAL CA FIRMA QUALIFICATA Serial#: 18563ece0fed15e9

L'Esperto ex art. 568 c.p.c.
Geom. Mulas Mario

ELENCO ALLEGATI:

- ✓ N° 8 Concessione edilizia - Concessioni Edilizie (Aggiornamento al 08/12/2024)
- ✓ N° 1 Estratti di mappa - Estratto di mappa (Aggiornamento al 02/11/2024)
- ✓ N° 1 Planimetrie catastali - Planimetria (Aggiornamento al 05/11/2024)
- ✓ N° 1 Visure e schede catastali - Visura immobile (Aggiornamento al 05/11/2024)
- ✓ N° 1 Visure e schede catastali - Visura storica (Aggiornamento al 05/11/2024)
- ✓ N° 8 Foto - Elaborati fotografici (Aggiornamento al 08/12/2024)

Firmato Da: MULAS MARIO Emesso Da: NAMIRIAL CA FIRMA QUALIFICATA Serial#: 18563ece0fed15e9

RIEPILOGO BANDO D'ASTA

LOTTO UNICO

- **Bene N° 1** - Appartamento ubicato a Ozieri (SS) - Via Giorgio Asproni n.5
  Appartamento sito al secondo piano di Via Asproni n.5 nel centro urbano di Ozieri, composto da: - ingresso; - cucina-soggiorno; - camera; - bagno; - terrazzo.
  Identificato al catasto Fabbricati - Fg. 68, Part. 1342, Sub. 7, Categoria A3
  L'immobile viene posto in vendita per il diritto di Proprietà (1/1)
  Destinazione urbanistica: L'unità immobiliare è situata nel Centro Matrice del Comune di Ozieri, meglio definito come Zona A

Firmato Da: MULAS MARIO Emesso Da: NAMIRIAL CA FIRMA QUALIFICATA Serial#: 18563ece0fed15e9

SCHEMA RIASSUNTIVO
ESECUZIONE IMMOBILIARE 52/2024 DEL R.G.E.

LOTTO UNICO

Bene N° 1 - Appartamento			
Ubicazione:	Ozieri (SS) - Via Giorgio Asproni n.5		
Diritto reale:	Proprietà	**Quota**	1/1
Tipologia immobile:	Appartamento Identificato al catasto Fabbricati - Fg. 68, Part. 1342, Sub. 7, Categoria A3	**Superficie**	44,88 mq
Stato conservativo:	Allo stato attuale l'unità immobiliare si trova in discrete condizioni con alcune opere da eseguirsi sui cornicioni esterni per evitare situazioni di pericolo.		
Descrizione:	Appartamento sito al secondo piano di Via Asproni n.5 nel centro urbano di Ozieri, composto da: - ingresso; - cucina-soggiorno; - camera; - bagno; - terrazzo.		
Vendita soggetta a IVA:	N.D.		
Continuità trascrizioni ex art. 2650 c.c.:	SI		
Stato di occupazione:	L'immobile risulta occupato dall'esecutato **** Omissis ****		

Firmato Da: MULAS MARIO Emesso Da: NAMIRIAL CA FIRMA QUALIFICATA Serial#: 18563ece0fed15e9

FORMALITÀ DA CANCELLARE CON IL DECRETO DI TRASFERIMENTO

Annotazioni a iscrizioni

- **Ipoteca Giudiziale**
  Iscritto a Sassari il 01/08/2019
  Reg. gen. 11137 - Reg. part. 1487
  Quota: 1/1
  A favore di **** Omissis ****
  Contro **** Omissis ****
  Formalità a carico della procedura

Firmato Da: MULAS MARIO Emesso Da: NAMIRIAL CA FIRMA QUALIFICATA Serial#: 18563ece0fed15e9

COPIA

C I T T A' DI O Z I E R I

PROVINCIA DI SASSARI

CONCESSIONE EDILIZIA N. 151/94

1994/0113

IL SINDACO

Vista la domanda presentata in data 07/07/1994 con la quale il sig.

C.Fisc.

Nato/a il a
Residente a

ha chiesto la concessione edilizia per i lavori di :
RISTRUTTURAZIONE E MODIFICHE INTERNE E DI PROSPET-
CASA CIVILE ABITAZIONE PLURIFAMILIARE
in Vicolo Asproni
in Catasto al Foglio 00068/1342 /

Visto il parere dell'Ufficio Tecnico comunale in data 15/09/1994

Visto il parere del Servizio Igiene pubblica in data 27/09/1994

Visto il parere espresso dalla Commissione Edilizia comunale nella seduta del 27/09/1994 verbale n. 270

Visto il Regolamento Edilizio Comunale;

Visto il Regolamento di Igiene e Polizia urbana;
Viste le Leggi urbanistiche n.ri 1150/42 e 765/67 e successive modifiche ed integrazioni;
Vista la Legge 28.1.1977, n. 10;
Vista la Legge 28.2.1985, n. 47 e succ. modif. e integrazioni;
Vista la L.R. 11.10.1985, n.23 e succ. modif. e integrazioni;
Visto il Nulla-Osta da parte del Comando prov. dei Vigili del Fuoco di Sassari in data
Visto il Piano Urbanistico comunale vigente e le sue Norme di Attuazione;
Visti i disegni di progetto allegati alla presente concessione

Fatte salve le disposizioni di cui alla L. 2.2.1974, n. 64 e D.M. 20.11.1987 "Norme tecniche per la progettazione, esecuzione e collaudo degli edifici in muratura e loro consolidamento";

R I L A S C I A
fatti salvi i diritti dei terzi

al Sig.

C.Fisc.

Nato/a il
Residente a

CONCESSIONE EDILIZIA GRATUITA

per l'esecuzione dei lavori di:
RISTRUTTURAZIONE E MODIFICHE INTERNE E DI PROSPET-
CASA CIVILE ABITAZIONE PLURIFAMILIARE
in Vicolo Asproni
in Catasto al Foglio 00068/1342 /

sotto l'osservanza delle vigenti disposizioni in materia di edilizia, di igiene e di polizia urbana nonche' alle seguenti

CONDIZIONI GENERALI

1)Che con la presente concessione, la quale si rilascia senza alcun pregiudizio dei terzi, non s'intenda acquisito per parte del richiedente alcun diritto per opporsi in qualunque caso o in qualsivoglia tempo contro quelle disposizioni che il Comune volesse adottare per migliorare le condizioni della strada suddetta, o per prendere indennita' rinunziando ora per allora, a qualsivoglia legge e consuetudine in contrario, rispetto a tal genere di indennita' nei limiti previsti dall'art. 24 della legge 17.8.1942, n. 1150 e succ. modificazioni.

2)Che ove si tratti di case per uso abitazione di nuova costruzione, o ricostruite o sopraelevate, modificate ecc., i proprietari son in obbligo di chiedere al Sindaco che siano dichiarate abitabili, ai sensi del T.U. delle leggi Sanitarie, approvato con R.D. 27 luglio 1934, n. 1265 e succ. modifiche.

3)Che il luogo destinato alla costruzione sia chiuso con apposita cinte lungo i lati prospicienti le pubbliche aree e che i ponti di servizio, tanto a collo che con abetelle infisse nel suolo o con capre, debbano avere la voluta stabilita' ed essere muniti dei necessari ripari onde evitare danni ed infortuni di cui sarebbero responsabili solo il concessionario, il direttore dei lavori ed il costruttore ai termini di legge.

4)Che ai detti ponti, durante la notte, venga collocata una lanterna accesa con luce rossa per indicare l'ingombro ai passeggeri, nonche' dei segnali fosforescenti approvati dall'Ufficio Tecnico Comunale.

5)Che prima di por mano al lavoro, il concessionario debba aver ritirato il permesso dall'Ufficio Municipale, e pagata la tassa per l'occupazione di suolo pubblico, quando dovuta, nell'intesa che le aree occupate devono essere rstituite in pristino stato a lavoro ultimato od anche prima, su richiesta del Comune, ove la costruzione venisse abbandonata o sospesa oltre un certo tempo.

6)Che le costruzioni siano conformi al progetto approvato e vengano eseguite a perfetta regola d'arte, non ritenendosi responsabile l'Amministrazione dei sinistri che possono avvenire.

7)Che per le costruzioni in cemento armato siano osservate le norme di cui al D.L. 16 novembre 1939, n. 2229 ed in particolare dell'art. 4 del decreto medesimo e successive modificazioni legge 1086/71.

8)Che vengano scrupolosamente osservate le norme in materia edilizia del Codice Civile del Regolamento Edilizio Comunale e le disposizioni che verranno impartite dagli organi competenti:
Legge n. 319 del 10.5.1976 e successive modificazioni;
Legge n. 10 del 09.1.1991 e successivo regolamento approvato con D.P.R. 26.8.1993 n. 412.

9)I lavori, pena la decadenza della presente Concessione, dovranno avere inizio entro un anno dal suo rilascio, e portati a termine (tali da rendere la costruzione abitabile o agibile), entro tre anni dalla data di inizio dei lavori.

10)L'avvenuto inizio, eventuali interruzioni e riprese degli stessi, nonche' l'ultimazione dei lavori dovranno essere comunicati entro cinque giorni del loro verificarsi con nota sottoscritta dal direttore dei lavori e dal committente.

ed alle seguenti

CONDIZIONI SPECIALI

Il proprietario committente, l'assuntore dei lavori, e il direttori dei lavori sono responsabili di ogni eventuale inosser-

vanza delle norme generali di leggi e regolamenti come delle modalita' esecutive fissate nella presente Concessione.

Allegati: n. 2 copie del progetto approvato.

Ozieri 10/10/1994

L'ASSESSORE DELEGATO
(Geom. Arturo Masia)

Il sottoscritto si obbliga all'esecuzione delle prestazioni ed all'osservanza di tutte le prescrizioni contenute nella presente.

IL CONCESSIONARIO

COPIA

COMUNE DI OZIERI
UFFICIO TECNICO
LA COMMISSIONE EDILIZIA

CITTÀ DI OZIERI
UFF. TECNICO

VISTO: si approva
N. 270 del 27 SET. 1994
ALL. ALLA CONC. EDILIZIA N. 151 DEL 10/10/94

L'ASSESSORE
(Geom. Arturo Maria)

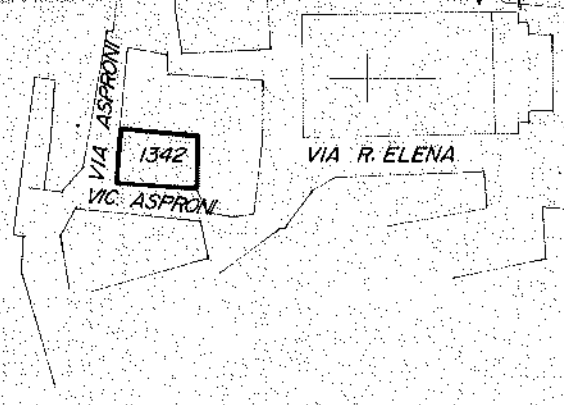

PLANIMETRIA N.C.E.U. Sc. 1:1000

COMUNE DI OZIERI Fº 68 m. 1342

TAV.	OGGETTO: LAVORI DI RISTRUTTURAZIONE, MODIFICHE INTERNE E DI PROSPETTO NEL FABBRICATO IN VICOLO ASPRONI AD OZIERI.
DATA: GIUGNO 1994	COMMITTENTE:
RAPP.: 1:100	PROGETTISTA: Geom.
	ELABORATO: DISEGNI STATO ATTUALE E MODIFICATO

IL COMMITTENTE

IL PROGETTISTA

COLLEGIO PROVINCIALE DEI GEOMETRI
N° 2003

STATO ATTUALE

Piano terra

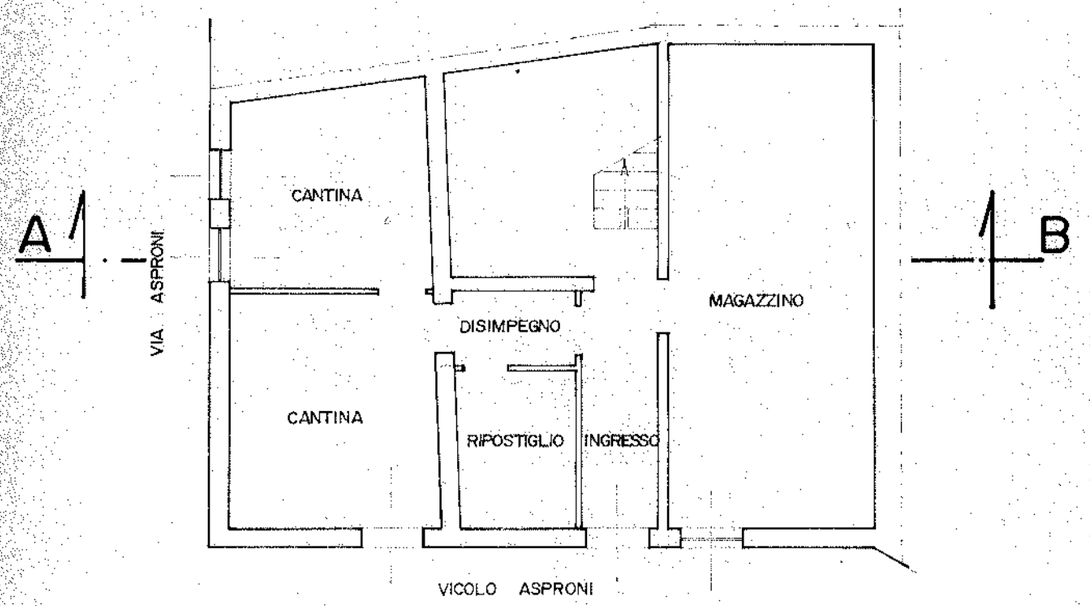

Piano secondo

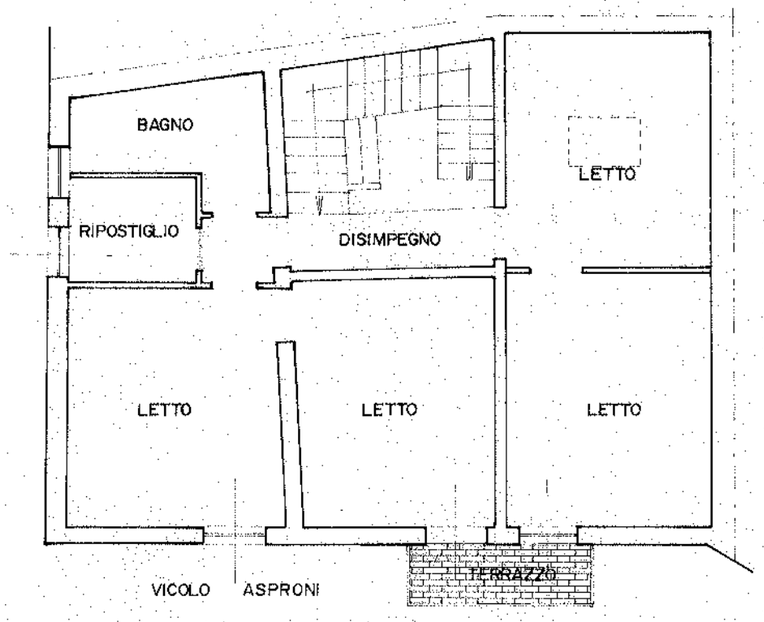

Piano primo

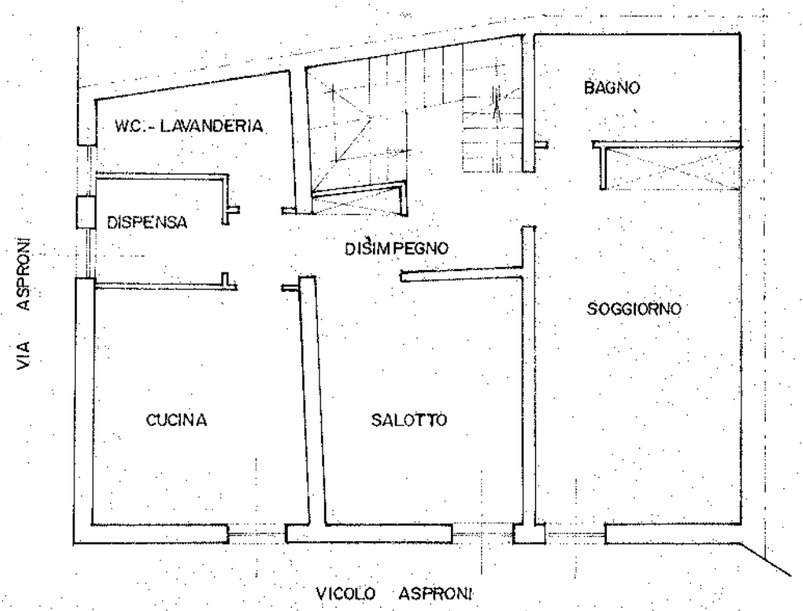

Sezione A-B

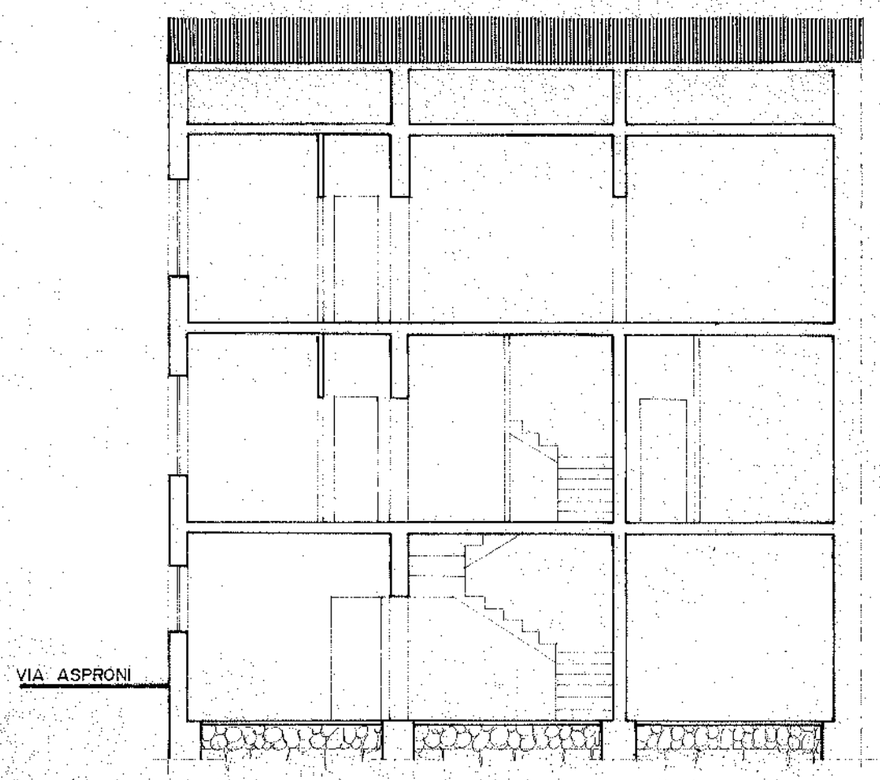

STATO MODIFICATO

Prospetto su via Asproni

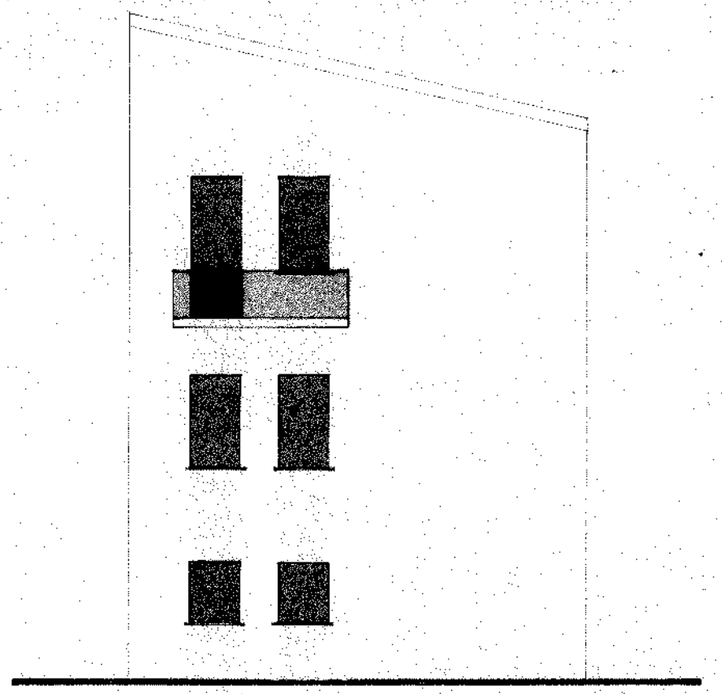

Prospetto su vicolo Asproni

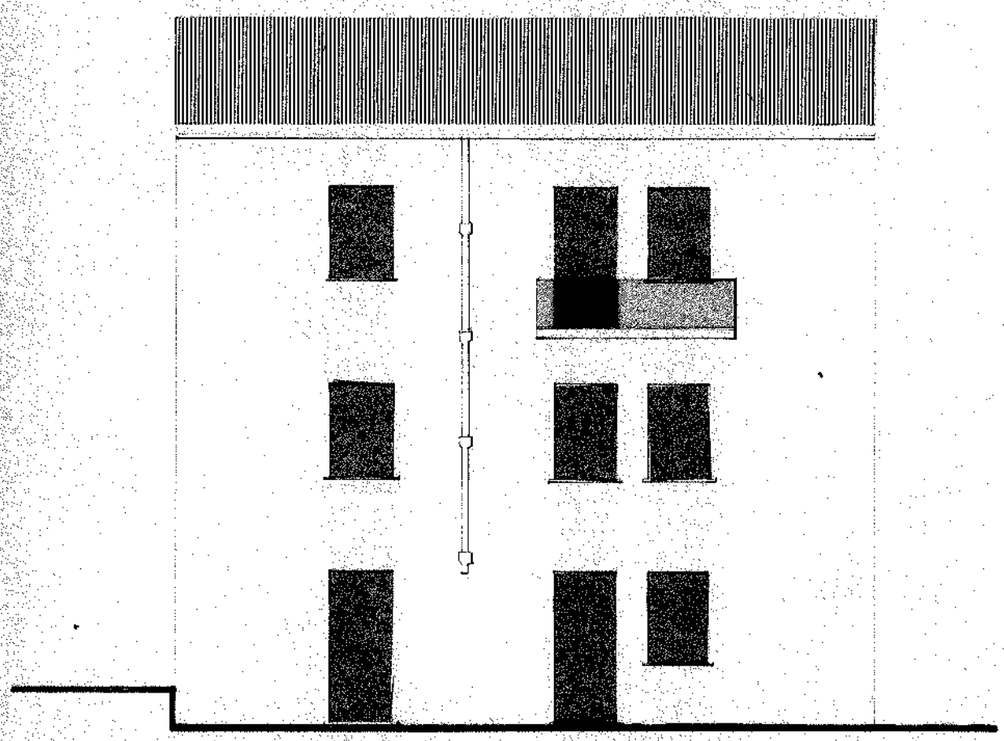

Piano terra

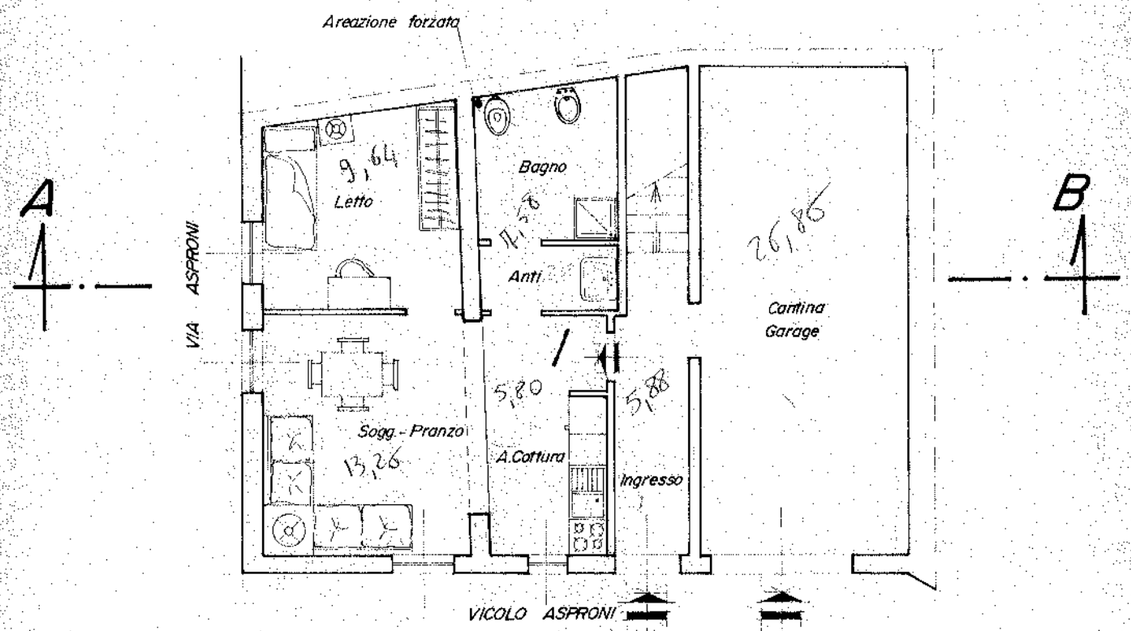

Piano primo

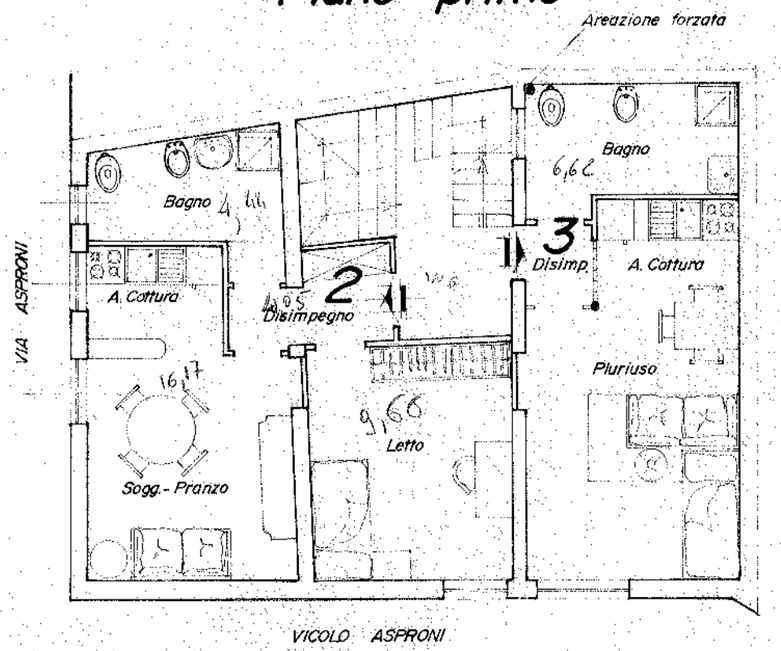

Piano secondo

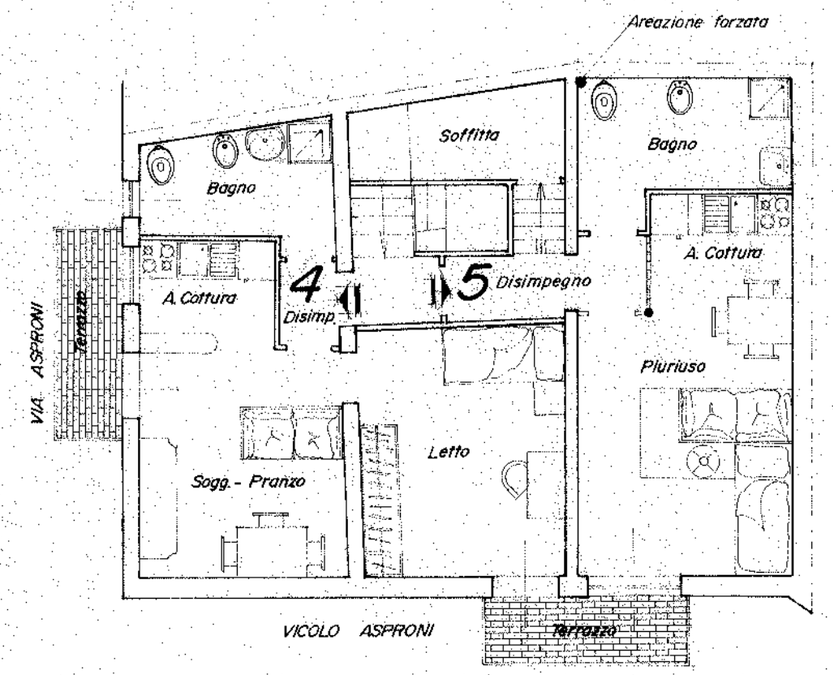

Prospetto su via Asproni

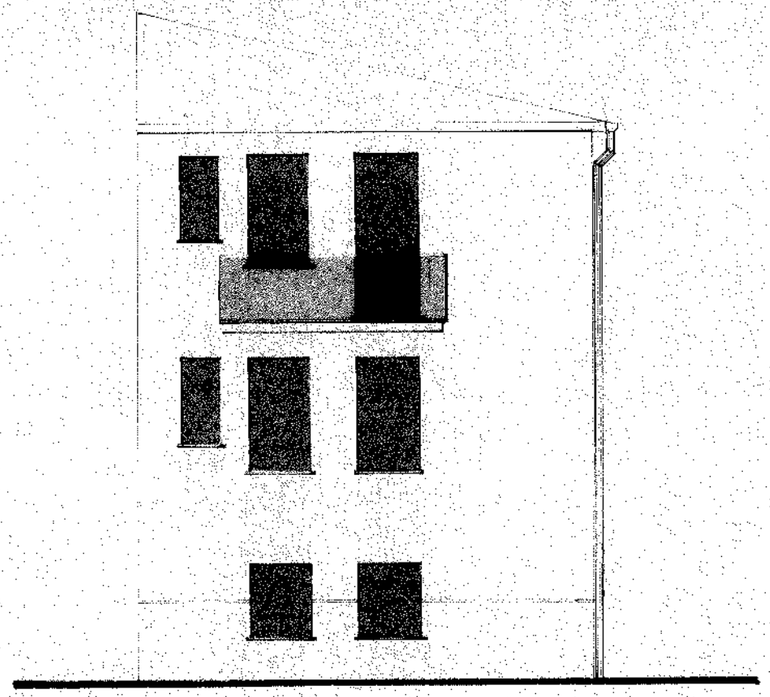

Prospetto su vicolo Asproni

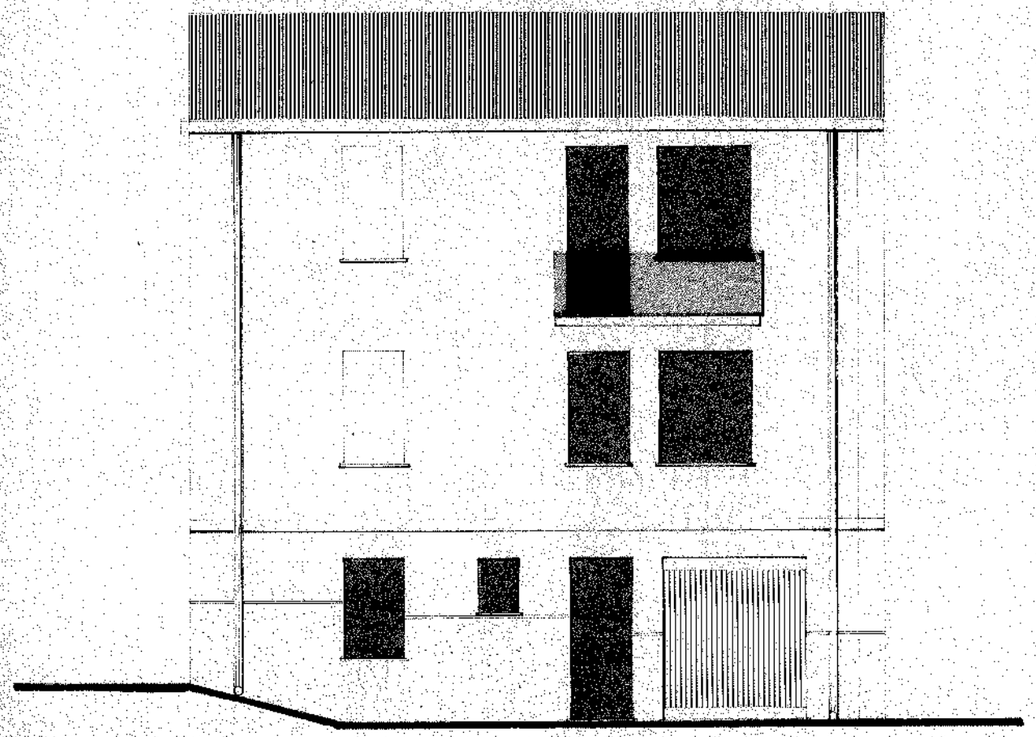

Sezione A-B

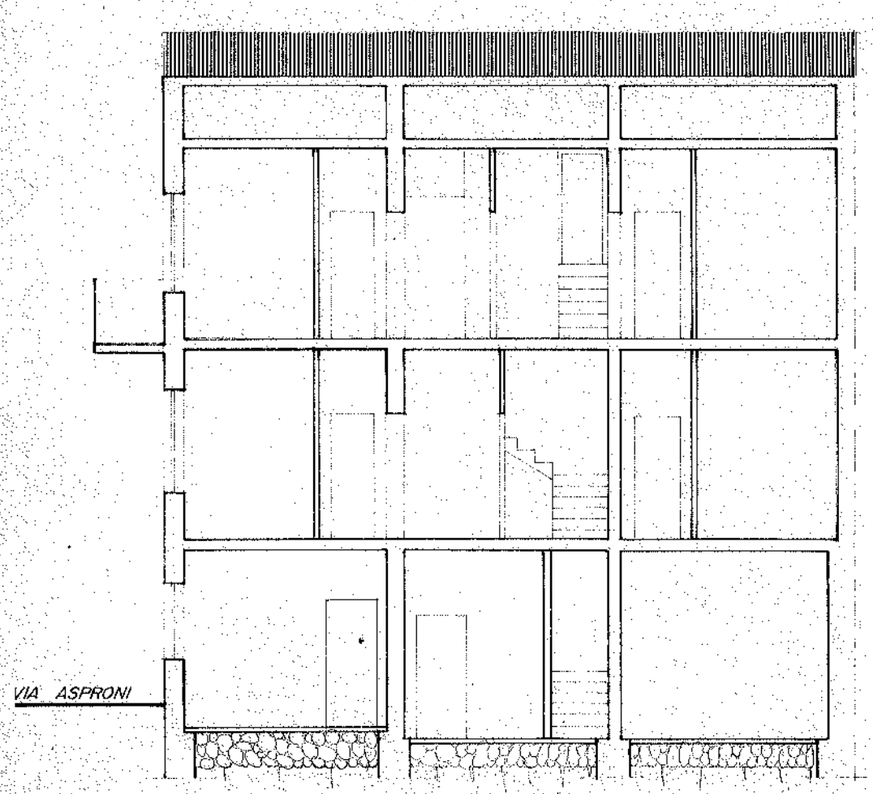

geometra

COPIA

RELAZIONE TECNICA

sull'osservanza norme legge 13/89 (superamento ed eliminazione delle barriere architettoniche) nel fabbricato in vicolo Asproni, 5 ad Ozieri.

Committente:

OZIERI GIUGNO 1994

COMUNE DI OZIERI
UFFICIO TECNICO
LA COMMISSIONE EDILIZIA
VISTO: si approva
N. 270 del 27 SET. 1994
ALL. ALLA CONC. EDILIZIA N. 151 DEL 10/10/94

CITTA' DI OZIERI
UFF. TECNICO

L'ASSESSORE
(Geom. Arturo Masia)

IL TECNICO
(Geom.)

COLLEGIO GEOMETRI SASSARI

Il fabbricato in oggetto risponderà al requisito di ADATTABILITA'disposto dall'art. 3.4. punto g della legge 13/89.

Il fabbricato si compone di tre piani: piano terra, primo e secondo. L'accesso al fabbricato avviene dal vicolo Asproni su un ampio disimpegno al piano terra. In questo piano, a sinistra dell'ingresso principale sarà ubicato un miniappartamento con angolo cottura, soggiorno-pranzo, antibagno, bagno e letto.

A destra dell'ingresso si troverà un ampio locale cantina-garage.

Sia nel primo che nel secondo piano si realizzeranno un miniappartamento, con soggiorno-pranzo-cottura, disimpegno, bagno e letto ed un monolocale con disimpegno, angolo cottura-pluriuso e bagno.

Il dislivello fra i tre piani del fabbricato potrà essere superato, qualora se ne presentasse la necessità, con l'installazione di un servoscala.

Le porte interne avranno una larghezza superiore ai cm 75 mentre il portone esterno sarà di cm 100.

Gli infissi esterni (finestre e porte-finestre) saranno dotati di meccanismi di apertura e chiusura che li rendano facilmente manovrabili e utilizzabili. Per essi saranno garantiti anche i requisiti di sicurezza e protezione dalle cadute verso l'esterno.

I disimpegni avranno un'ampiezza tale da consentire una facile manovrabilità anche a persone su sedia a ruote.
I pavimenti saranno orizzontali e complanari o verranno adattati all'occorrenza.

Nei bagni gli apparecchi sanitari saranno disposti in modo da consentire, con opportuni accorgimenti spaziali, le manovre di una sedia a ruote.

Nelle cucina gli apparecchi verranno disposti nel rispetto delle norme.

In considerazione di quanto esposto, la sottoscritta progettista dei lavori di ristrutturazione, modifiche interne e di prospetto nel fabbricato in vicolo Asproni ad Ozieri:

CERTIFICA

CHE LE PREVISIONI PROGETTUALI SONO CONFORMI AI REQUISITI DELLA

LEGGE 9 GENNAIO 1989 N° 13.

OZIERI GIUGNO 1994

IL TECNICO

(Geom.)

COLLEGIO PROVINCIALE

geomeira

COPIA

RELAZIONE DESCRITTIVA

dei lavori di ristrutturazione, modifiche interne e di prospetto nel fabbricato in vicolo Asproni ad Ozieri.

Committente:

Ozieri Giugno 1994

COMUNE DI OZIERI
UFFICIO TECNICO
LA COMMISSIONE EDILIZIA
VISTO: si approva
N. 270 del 27 SET. 1994
ALL. ALLA CONC. EDILIZIA N. 151 DEL 10/10/94

CITTA' DI OZIERI - UFF. TECNICO -

L'ASSESSORE
(Geom. Arturo Masia)

Il tecnico
(Geom.

COLLEGIO PROVINCIALE DEI GEOMETRI
N°2003
SASSARI

Con l'intervento in oggetto si intende modificare la disposizione interna del fabbricato, ora adibito ad unica abitazione, creando cinque nuove unita'abitative ed un'ampia cantina-garage.

La variazione della distribuzione degli ambienti interni comportera' la demolizione di alcuni tramezzi e l'apertura di nuovi vani porta. Anche i prospetti verranno modificati realizzando nuove finestre e porte ed ampliandone altre già esistenti affinchè tutti i vani siano sufficientemente arieggiati ed illuminati.

Nel piano terra , alla sinistra dell'ingresso, si realizzera' un mini appartamento (appartamento 1). Con la demolizione di una parte del muro portante si ricavera' un ampio arco che mettera' in comunicazione il soggiorno-pranzo con l'angolo cottura.

Sempre dallo stesso ambiente si potra' accedere alla camera da letto ed all'antibagno con attiguo bagno. In questo appartamento dovra' essere ricavata una nuova apertura esterna in corrispondenza dell'angolo cottura per una sua migliore aerazione. Nel soggiorno invece dovra' crearsi, al posto dell'esistente porta esterna, una finestra di regolari dimensioni. Verranno inoltre ampliate le altre due aperture esistenti.

Nell'attuale magazzino, a destra dell'ingresso principale, con l'apertura di un'ampia porta verso il vicolo, potra' ricavarsi un ampio locale cantina-garage.

Sia nel primo che nel secondo piano si realizzeranno 1 mini appartamento (appartamenti 2 e 4), con soggiorno-pranzo-cottura, disimpegno, bagno e letto ed 1 monolocale (appartamenti 3 e 5) con disimpegno, angolo cottura-pluriuso e bagno.

Anche in queste nuove unità abitative sarà necessaria la realizzazione di nuove aperture esterne, l'ampliamento di alcune delle altre esistenti e la chiusura di due finestre che si affacciano sul vicolo Asproni.Anche i terrazzi esistenti verranno leggermente ingranditi.

Nel piano secondo, nell'appartamento 5 verrà realizzata una piccola rampa di scala che servirà per accedere alla soffitta centrale.

Là dove la nuova sistemazione lo renderà necessario, verranno eseguiti interventi di nuova pavimentazione.

La nuova disposizione interna degli ambienti renderà necessario l'adeguamento dell'impianto idrico e di scarico esistenti secondo le norme igieniche vigenti e le disposizioni del P.U.C. ed il rifacimento dell'impianto elettrico nel rispetto delle norme in materia di sicurezza degli impianti previste dalla legge n° 46/90 del 5.3.1990.

CALCOLO SUPERFICI NETTE APPARTAMENTI

PIANO TERRA

Appartamento 1

Sogg.-Pranzo-A.Cottura	1/2 x (2.00+1.90) x 3.90	= mq	7.61
	1/2 x (3.40+3,25) x 3.90	= "	12.97
	0.30x3.20	= "	0.93
		mq	21.51
Antibagno	2.20x1.10	= mq	2.42
Bagno	1/2 x (2.70+2.30) x 2.20	= mq	5.50
Letto	1/2 x (3.40+3.00) x 3.20	= mq	10.24
	SOMMANO	mq	39.67
Cantina- garage	3.40x8.00	= mq	27.20

Piano terra

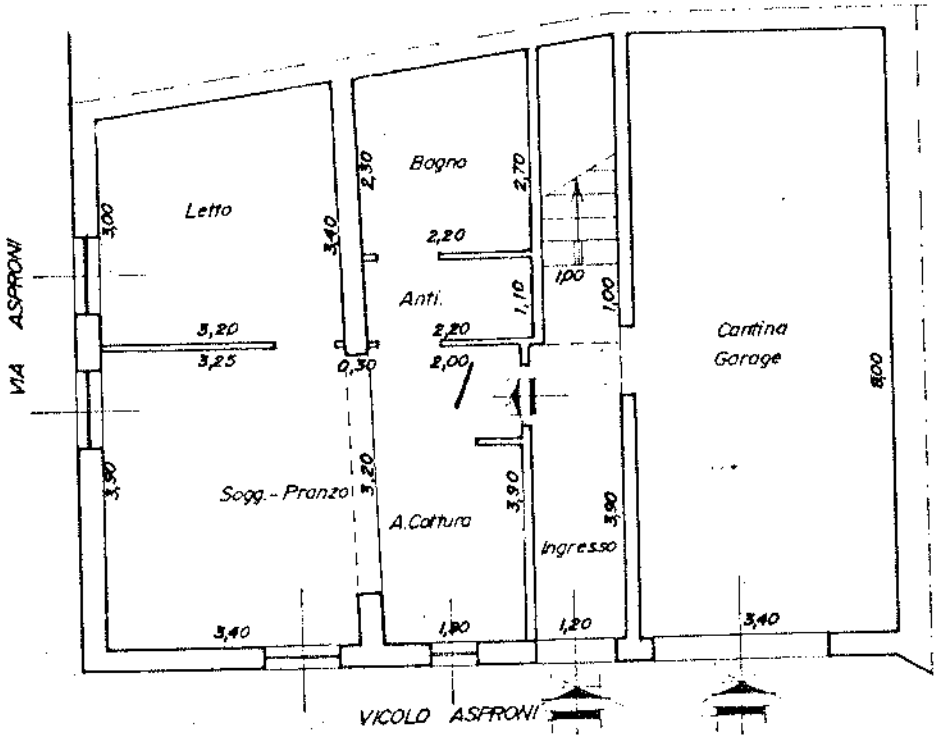
Letto
Bagno
Anti.
Sogg.-Pranzo
A.Cottura
Ingresso
Cantina
Garage
VIA ASPRONI
VICOLO ASPRONI
3,00
3,40
2,30
2,70
2,20
1,10
1,00
3,20
3,25
0,30
2,00
3,90
3,20
3,90
3,90
8,00
3,40
1,20
1,20
3,40

PIANO PRIMO

Appartamento 2

Disimpegno	1/2 x (1.60+1.50) x 1.50	= mq	2.33
	1.30x1.00	= "	1.30
		mq	3.63
Sogg.-Pranzo-A.Cottura	2.20x1.80	= mq	3.96
	1/2 x (3.50+3.30) x 3.70	= mq	12.24
		mq	16.20
Bagno	0.90x0.70	= mq	0.63
	1/2 x (1.40+1.90) x 3.20	= mq	5.28
		mq	5.91
Letto	3.30x3.80	= mq	12.54
	SOMMANO	mq	38.28

Appartamento 3

Disimpegno	1.10x1.30	= mq	1.43
A.Cottura-Pluriuso	2.35x1.80	= mq	4.23
	3.55x4.40	= mq	15.62
		mq	19.85
Bagno	1.10x0.40	= mq	0.44
	3.55x1.80	= mq	6.39
		mq	6.83
	SOMMANO	mq	28.11

Piano primo

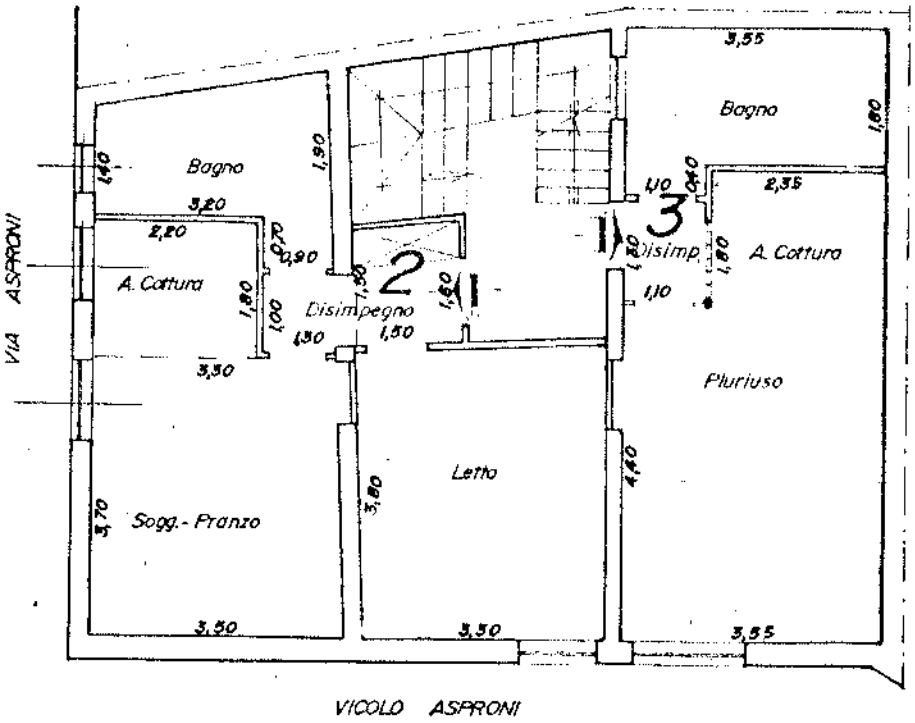
Bagno
Bagno
A. Cottura
Disimpegno
Disimp.
A. Cottura
Pluriuso
Letto
Sogg.- Pranzo
VIA ASPRONI
VICOLO ASPRONI
1
2
3
3,55
1,60
1,40
3,20
2,20
1,50
0,90
0,70
1,80
1,00
1,30
1,50
3,50
1,10
0,40
2,35
4,40
3,80
3,70
3,50

PIANO SECONDO

Appartamento 4

Disimpegno	1.00x1.40	= mq	1.44
A.cottura-Sogg.-Pranzo	2.20x1.80	= mq	3.96
	1/2 x (3.50+3.30) x 3.70	= mq	12.58
		mq	16.54
Bagno	0.90x0.30	= mq	0.27
	1/2 x (1.50+2.00) x 3.20	= mq	5.60
		mq	5.87
Letto	1/2 x (3.30+3.40) x 4.10	= mq	13.74
Terrazzo	3.40x1.10	= mq	3.74
	SOMMANO	mq	41.33

Appartamento 5

Disimpegno	2.10x1.00	= mq	2.10
	1.10x1.20	= mq	1.32
		mq	3.42
A.Cottura-pluriuso	2.35x2.00	= mq	4.70
	3.55x4.20	= mq	14.91
		mq	19.61
Bagno	1.10x0.70	= mq	0.77
	3.55x1.80	= mq	6.39
		mq	7.16
Terrazzo	3.40x1.10	= mq	3.74
	SOMMANO	mq	33.93
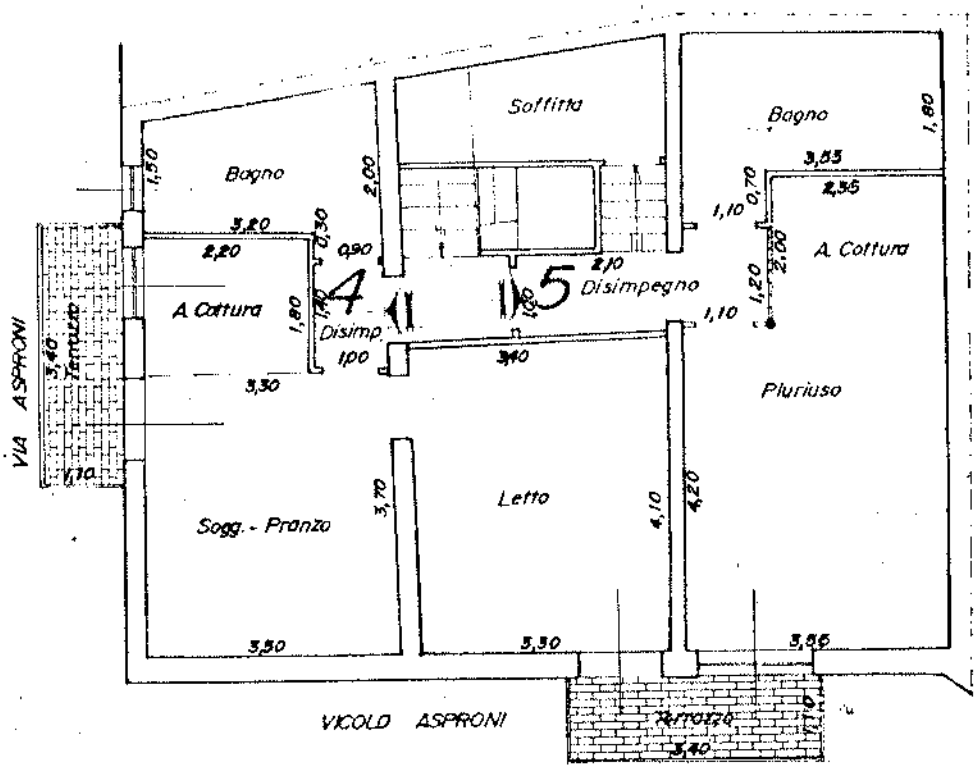
Piano secondo