TRIBUNALE DI SASSARI

SEZIONE EE.II.

Perizia dell'Esperto ex art. 568 c.p.c. Ing. Conchedda Antonio, nell'Esecuzione Immobiliare 63/2024 del R.G.E.

contro

******* Omissis *******

Firmato Da: CONCHEDDA ANTONIO Emesso Da: INFOCAMERE QUALIFIED ELECTRONIC SIGNATURE CA Serial#: 103d3e

SOMMARIO

Incarico....3
Premessa....3
Descrizione....3
Lotto Unico....3
Completezza documentazione ex art. 567....3
Titolarità....3
Confini....4
Consistenza....4
Cronistoria Dati Catastali....4
Dati Catastali....5
Precisazioni....5
Stato conservativo....5
Parti Comuni....5
Servitù, censo, livello, usi civici....5
Caratteristiche costruttive prevalenti....6
Stato di occupazione....6
Provenienze Ventennali....6
Formalità pregiudizievoli....7
Normativa urbanistica....8
Regolarità edilizia....11
Vincoli od oneri condominiali....11
Stima / Formazione lotti....12
Riepilogo bando d'asta....15
Lotto Unico....15
Schema riassuntivo Esecuzione Immobiliare 63/2024 del R.G.E.....18
Lotto Unico....18

Firmato Da: CONCHEDDA ANTONIO Emesso Da: INFOCAMERE QUALIFIED ELECTRONIC SIGNATURE CA Serial#: 103d3e

INCARICO

All'udienza del 08/07/2024, il sottoscritto Ing. Conchedda Antonio, con studio in Via Degli Astronauti 3/D - 07100 - Sassari (SS), email a.c.ingegneria@gmail.com, PEC antonio.conchedda@ingpec.eu, Tel. 347 9674930, veniva nominato Esperto ex art. 568 c.p.c. e in data 10/07/2024 accettava l'incarico e prestava giuramento di rito.

PREMESSA

I beni oggetto di pignoramento sono costituiti dai seguenti immobili:

- **Bene N° 1** - Appartamento ubicato a Ittiri (SS) - Via Amsicora 53

DESCRIZIONE

Oggetto della presente perizia è un fabbricato adibito ad uso residenziale posto ai piani terra/primo, ubicato all'interno del perimetro urbano dell'abitato del Comune di Ittiri, in posizione semicentrale, più precisamente in via Amsicora n° 53. La zona in cui insiste il cespite si presenta completamente edificata con tipologia costruttiva del tutto simile al bene in oggetto e risulta intensamente percorsa da traffico veicolare e pedonale con discreta viabilità e discreta possibilità di parcheggio. Buoni i collegamenti con le principali arterie stradali della regione Sardegna da e per la città di Ittiri, quali la SP28, SP15, SS131 bis e SS 131 Carlo Felice. Il cespite ha accesso diretto dalla porta d'ingresso posta in affaccio sulla pubblica viabilità.

L'immobile da progetto autorizzato risulta composto da:
-Piano terra: ampio vano adibito a locale sgombero, bagno, ripostiglio, vano scala, corte esclusiva;
-Piano primo: soggiorno-cucina, disimpegno, ripostiglio, 2 camere, bagno, vano scala, terrazzo.

LOTTO UNICO

Il lotto è formato dai seguenti beni:

- **Bene N° 1** - Appartamento ubicato a Ittiri (SS) - Via Amsicora 53

COMPLETEZZA DOCUMENTAZIONE EX ART. 567

Si attesta che la documentazione di cui all'art. 567 c.p.c., comma 2 risulta completa.

TITOLARITÀ

L'immobile oggetto dell'esecuzione, appartiene ai seguenti esecutati:

- **** Omissis **** (Proprietà 1/1)

Firmato Da: CONCHEDDA ANTONIO Emesso Da: INFOCAMERE QUALIFIED ELECTRONIC SIGNATURE CA Serial#: 103d3e

L'immobile viene posto in vendita per i seguenti diritti:

- **** Omissis **** (Proprietà 1/1)

Regime patrimoniale di separazione legale dei beni.

CONFINI

CONFINI
Nord: via Amsicora;
Ovest: via Amsicora angolo via Montesile;
Sud: via Montesile;
Est: mappale 2613, 2390, 2598, 2610 e 2597 al C.T.

CONSISTENZA

Destinazione	Superficie Netta	Superficie Lorda	Coefficiente	Superficie Convenzionale	Altezza	Piano
Abitazione	58,39 mq	84,00 mq	1,00	84,00 mq	2,75 m	1
Terrazza	12,08 mq	14,00 mq	0,30	4,20 mq	0,00 m	1
Locale di sgombero	65,05 mq	91,00 mq	0,50	45,50 mq	2,90 m	T
Cortile	9,49 mq	12,00 mq	0,10	1,20 mq	0,00 m	T
			Totale superficie convenzionale:	**134,90 mq**		
			Incidenza condominiale:	**0,00**	**%**	
			Superficie convenzionale complessiva:	**134,90 mq**		

CRONISTORIA DATI CATASTALI

Periodo	Proprietà	Dati catastali
Dal **07/03/2023** al **05/12/2024**	**** Omissis ****	Catasto **Fabbricati** Fg. 73, Part. 775, Sub. 26 Categoria A2 Cl.2, Cons. 6,5 Superficie catastale 174 mq Rendita € 654,61 Piano T-1

Firmato Da: CONCHEDDA ANTONIO Emesso Da: INFOCAMERE QUALIFIED ELECTRONIC SIGNATURE CA Serial#: 103d3e

Per i precedenti sono da visionare le visure storiche dei seguenti immobili soppressi, originari del precedente Foglio 73 Particella 775 Subalterno 18; Foglio 73 Particella 775 Subalterno 19;

DATI CATASTALI

Catasto fabbricati (CF)											
Dati identificativi				Dati di classamento							
Sezione	Foglio	Part.	Sub.	Zona Cens.	Categoria	Classe	Consistenza	Superficie catastale	Rendita	Piano	Graffato
	73	775	26		A2	2	6,5	174 mq	654,61 €	T-1	

Corrispondenza catastale

Sussiste corrispondenza tra lo stato dei luoghi e la planimetria catastale esistente nonché con quanto presente nell'atto di pignoramento.

PRECISAZIONI

Sono stati esaminati gli atti del procedimento e verificata la completezza di documenti di cui all'art. 567 secondo comma del c.p.c. Sono state effettuate le visure catastali, e la richiesta di accesso agli atti amministrativi presso il Comune di Ittiri al fine di verificare la conformità urbanistica. Si è rilevata la non esistenza dell'Attestato di Prestazione Energetica (APE), il sottoscritto pertanto procede alla redazione dell'APE per l'immobile.

STATO CONSERVATIVO

L'immobile al momento del sopralluogo si presentava in discreto stato manutenzione e conservazione complessivo.

PARTI COMUNI

Non sono presenti spazi condominiali.

SERVITÙ, CENSO, LIVELLO, USI CIVICI

Non si è rilevata l'esistenza di servitù gravanti sul bene oggetto di pignoramento.

Firmato Da: CONCHEDDA ANTONIO Emesso Da: INFOCAMERE QUALIFIED ELECTRONIC SIGNATURE CA Serial#: 103d3e

CARATTERISTICHE COSTRUTTIVE PREVALENTI

- Struttura in elevazione realizzata con muratura portante in blocchi di pietra naturale;
- Solaio di copertura realizzato con tetto a falde in cls con sovrapposto strato impermeabilizzante e manto di tegole in laterizio;
- Intonaci interni ed esterni realizzati con intonaco di tipo civile liscio;
- Tinteggiature interne ed esterne realizzate con idropittura lavabile e traspirante;
- Pavimentazione realizzata in mattonelle di ceramica;
- Infissi esterni realizzati in legno con vetro camera completi di persiane esterne in pvc;
- Infissi interni realizzati in legno tamburato;
- Porta d'ingresso realizzata in legno completa di serratura di sicurezza;
- Impianto idrico ed elettrico realizzati entro traccia;
- Impianto di condizionamento autonomo funzionante con pompa di calore ad energia elettrica e sistema radiante del tipo split a parete;
- Predisposizione impianto di riscaldamento autonomo da alimentare con caldaia a gasolio e sistema radiante del tipo radiatori in ghisa a parete;
- Stufa a pellet;
- ACS da caldaia a gas.

L'immobile presenta finiture di media qualità.

STATO DI OCCUPAZIONE

L'immobile al momento del sopralluogo risultava occupato dall'esecutato.

PROVENIENZE VENTENNALI

Periodo	Proprietà	Atti			
Dal **25/06/2001** al **05/12/2024**	**** Omissis ****	**Compravendita**			
		Rogante	**Data**	**Repertorio N°**	**Raccolta N°**
		Luigi Maniga	25/06/2001	174430	
		Trascrizione			
		Presso	**Data**	**Reg. gen.**	**Reg. part.**
		Sassari	04/07/2001	10523	7656
		Registrazione			
		Presso	**Data**	**Reg. N°**	**Vol. N°**

Firmato Da: CONCHEDDA ANTONIO Emesso Da: INFOCAMERE QUALIFIED ELECTRONIC SIGNATURE CA Serial#: 103d3e

FORMALITÀ PREGIUDIZIEVOLI

Dalle visure ipotecarie effettuate presso l'Agenzia delle entrate di Sassari aggiornate al 06/12/2024, sono risultate le seguenti formalità pregiudizievoli:

Trascrizioni

- **Atto esecutivo o cautelare**
  Trascritto a Verbale di Pignoramento Immobili il 20/05/2024
  Reg. gen. 8455 - Reg. part. 6824

La formalità sopradescritta riguarda l'immobile censito al Comune di ITTIRI (SS) Catasto Fabbricati

Sezione urbana - Foglio 73 Particella 775 Subalterno 26
Elenco sintetico delle formalità

Considerato che il Subalterno 26 deriva dii seguenti immobili soppressi, originari del precedente
Foglio 73 Particella 775 Subalterno 18; Foglio 73 Particella 775 Subalterno 19;

Per maggiore chiarezza si riporta di seguito l'elenco completo delle formalità:

Comune di ITTIRI (SS) Catasto Fabbricati

Sezione urbana - Foglio 0073 Particella 00775 Subalterno 0018
Elenco sintetico delle formalità

1. TRASCRIZIONE del 27/05/2010 - Registro Particolare 5395 Registro Generale 8716
Pubblico ufficiale FAEDDA LAURA Repertorio 11656/4239 del 20/05/2010
ATTO TRA VIVI - COSTITUZIONE DI FONDO PATRIMONIALE
Nota disponibile in formato elettronico
Documenti successivi correlati:
1. Annotazione n. 1374 del 16/12/2014 (REVOCAZIONE)
2. Annotazione n. 1025 del 20/10/2015 (AVVENUTA TRASCRIZIONE DI DOMANDA GIUDIZIALE)
3. Annotazione n. 350 del 07/03/2018 (INEFFICACIA RELATIVA EX ART. 2901 C.C.)

2. TRASCRIZIONE del 07/03/2012 - Registro Particolare 2619 Registro Generale 3427
Pubblico ufficiale TRIBUNALE SASSARI SEZ DIST ALGHERO Repertorio 19 del 18/01/2012
DOMANDA GIUDIZIALE - REVOCA ATTI SOGGETTI A TRASCRIZIONE
Nota disponibile in formato elettronico

3. TRASCRIZIONE del 18/04/2013 - Registro Particolare 3942 Registro Generale 5698
Pubblico ufficiale UFFICIALE GIUDIZIARIO Repertorio 60 del 26/01/2013
ATTO ESECUTIVO O CAUTELARE - VERBALE DI PIGNORAMENTO IMMOBILI
Nota disponibile in formato elettronico

4. TRASCRIZIONE del 03/08/2015 - Registro Particolare 6780 Registro Generale 8656

Firmato Da: CONCHEDDA ANTONIO Emesso Da: INFOCAMERE QUALIFIED ELECTRONIC SIGNATURE CA Serial#: 103d3e

Pubblico ufficiale TRIBUNALE CIVILE DI SASSARI Repertorio 1938 del 18/05/2015
DOMANDA GIUDIZIALE - REVOCA ATTI SOGGETTI A TRASCRIZIONE
Nota disponibile in formato elettronico

5. ANNOTAZIONE del 20/10/2015 - Registro Particolare 1025 Registro Generale 11770
Pubblico ufficiale TRIB. CIV. SS Repertorio 6780 del 03/08/2015
ANNOTAZIONE A TRASCRIZIONE - AVVENUTA TRASCRIZIONE DI DOMANDA GIUDIZIALE
Nota disponibile in formato elettronico
Formalità di riferimento: Trascrizione n. 5395 del 2010

Comune di ITTIRI (SS) Catasto Fabbricati

Sezione urbana - Foglio 0073 Particella 00775 Subalterno 0019
Elenco sintetico delle formalità

1. TRASCRIZIONE del 27/05/2010 - Registro Particolare 5395 Registro Generale 8716
Pubblico ufficiale FAEDDA LAURA Repertorio 11656/4239 del 20/05/2010
ATTO TRA VIVI - COSTITUZIONE DI FONDO PATRIMONIALE
Nota disponibile in formato elettronico
Documenti successivi correlati:
1. Annotazione n. 1374 del 16/12/2014 (REVOCAZIONE)
2. Annotazione n. 1025 del 20/10/2015 (AVVENUTA TRASCRIZIONE DI DOMANDA GIUDIZIALE)
3. Annotazione n. 350 del 07/03/2018 (INEFFICACIA RELATIVA EX ART. 2901 C.C.)

2. TRASCRIZIONE del 07/03/2012 - Registro Particolare 2619 Registro Generale 3427
Pubblico ufficiale TRIBUNALE SASSARI SEZ DIST ALGHERO Repertorio 19 del 18/01/2012
DOMANDA GIUDIZIALE - REVOCA ATTI SOGGETTI A TRASCRIZIONE
Nota disponibile in formato elettronico

3. TRASCRIZIONE del 18/04/2013 - Registro Particolare 3942 Registro Generale 5698
Pubblico ufficiale UFFICIALE GIUDIZIARIO Repertorio 60 del 26/01/2013
ATTO ESECUTIVO O CAUTELARE - VERBALE DI PIGNORAMENTO IMMOBILI
Nota disponibile in formato elettronico

4. TRASCRIZIONE del 03/08/2015 - Registro Particolare 6780 Registro Generale 8656
Pubblico ufficiale TRIBUNALE CIVILE DI SASSARI Repertorio 1938 del 18/05/2015
DOMANDA GIUDIZIALE - REVOCA ATTI SOGGETTI A TRASCRIZIONE
Nota disponibile in formato elettronico

5. ANNOTAZIONE del 20/10/2015 - Registro Particolare 1025 Registro Generale 11770
Pubblico ufficiale TRIB. CIV. SS Repertorio 6780 del 03/08/2015
ANNOTAZIONE A TRASCRIZIONE - AVVENUTA TRASCRIZIONE DI DOMANDA GIUDIZIALE
Nota disponibile in formato elettronico
Formalità di riferimento: Trascrizione n. 5395 del 2010

NORMATIVA URBANISTICA

Firmato Da: CONCHEDDA ANTONIO Emesso Da: INFOCAMERE QUALIFIED ELECTRONIC SIGNATURE CA Serial#: 103d3e

Art. 20 - Zone B

Le Zone classificate 'B' di completamento sono prevalentemente destinate alla residenza. Gli usi ammessi, con riferimento alle disposizioni delle presenti norme, sono quelli dei Gruppi 1 e 2. Sono suddivise in:

Zone 'B1 di completamento non assoggettate a Piano Particolareggiato: sono sempre consentiti gli interventi di manutenzione ordinaria e straordinaria, di restauro e risanamento conservativo, la ristrutturazione edilizia e la nuova edificazione anche a seguito di demolizione. Per tali zone valgono i seguenti parametri:

L'indice fondiario massimo (IF) : 3 mc/mq

H: ml.9.00

IC : 0.70 mq/mq.

Gli edifici possono sorgere in aderenza o debbono distare dai confini non meno di m. 4.00. (Nei tratti di strada con tessuto urbano già definito, è possibile, sentito il parere della C.E. derogare a questa norma per conservare l'allineamento dei fabbricati esistenti).

La distanza minima da osservare tra due edifici non in aderenza è pari a ml. 8.00 se le pareti non sono finestrate; ml. 10.00 se le pareti sono finestrate .

Non sono consentiti sbalzi sugli spazi pubblici superiori a cm. 20. I muri di recinzione delle proprietà fronteggianti vie o piazze aperte al pubblico transito, non dovranno avere un'altezza superiore a mt. 1.0 perle parti murarie e le loro superfici dovranno essere adeguatamente rifinite. Recinzioni di altezza superiore dovranno essere realizzate con strutture a giorno. I muri divisori dei giardini o dei cortili non visibili da are pubbliche devono avere un'altezza non superiore a ml. 3.00, e dovranno essere realizzati nel rispetto delle norme del Codice Civile.

Per le zone contigue o in diretto rapporto visuale con la zona A, le altezze massime dei nuovi edifici non possono superare altezze compatibili con quelle degli altri edifici della zona A predetta. E' prescritta tra pareti finestrate la distanza minima pari all'altezza del fabbricato più alto.

Zone 'B2' di completamento non assoggettate a Piano Particolareggiato: sono sempre consentiti gli interventi di manutenzione ordinaria e straordinaria, di restauro e risanamento conservativo, la ristrutturazione edilizia e la nuova edificazione anche a seguito di demolizione. Per tali zone valgono i seguenti parametri:

L'indice fondiario massimo (IF) : 3 mc/mq

IC : 0,60 mq/mq.

Gli edifici possono sorgere in aderenza o debbono distare dai confini non meno di m. 4.00. (Nei tratti di strada con tessuto urbano già definito, è possibile, sentito il parere della C.E. derogare a questa norma per conservare l'allineamento dei fabbricati esistenti).

La distanza minima da osservare tra due edifici non in aderenza è pari a ml. 8.00 se le pareti non sono finestrate; ml. 10.00 se le pareti sono finestrate .

Non sono consentiti sbalzi sugli spazi pubblici superiori a cm. 20. I muri di recinzione delle proprietà fronteggianti vie o piazze aperte al pubblico transito, non dovranno avere un'altezza superiore a mt. 1.0 perle parti murarie e le loro superfici dovranno essere adeguatamente rifinite. Recinzioni di altezza superiore dovranno essere realizzate con strutture a giorno. I muri divisori dei giardini o dei cortili non visibili da are pubbliche devono avere un'altezza non superiore a ml. 3.00, e dovranno essere realizzati nel rispetto delle norme del Codice Civile.

Per le zone contigue o in diretto rapporto visuale con la zona A, le altezze massime dei nuovi edifici non possono superare altezze compatibili con quelle degli altri edifici della zona 'A' predetta. E' prescritta tra pareti finestrate la distanza minima pari all'altezza del fabbricato più alto.

Zone 'B3' di completamento non assoggettate a Piano Particolareggiato: sono sempre consentiti gli interventi di manutenzione ordinaria e straordinaria, di restauro e risanamento conservativo, la ristrutturazione edilizia e la nuova edificazione anche a seguito di demolizione.

Per tali zone valgono i seguenti parametri:

L'indice fondiario massimo (IF) : 1.70 mc/mq

H : ml.9.00

IC : 0,50 mq/mq.

Il fabbricato previsto può presentare, lungo i fronti stradali, non più di 3 piani fuori terra.

Firmato Da: CONCHEDDA ANTONIO Emesso Da: INFOCAMERE QUALIFIED ELECTRONIC SIGNATURE CA Serial#: 103d3e

È ammessa la costruzione di un solo piano seminterrato qualora per le particolari condizioni del terreno risultino dislivelli che ne consentano la realizzazione
Gli edifici possono sorgere in aderenza o debbono distare dai confini non meno di m. 4.00. (Nei tratti di strada con tessuto urbano già definito, è possibile, sentito il parere della C.E. derogare a questa norma per conservare l'allineamento dei fabbricati esistenti).
La distanza minima da osservare tra due edifici non in aderenza è pari a ml. 8.00 se le pareti non sono finestrate; ml. 10.00 se le pareti sono finestrate .
Non sono consentiti sbalzi sugli spazi pubblici superiori a cm. 20. I muri di recinzione delle proprietà non dovranno avere un'altezza superiore a mt. 1.00 e le loro superfici dovranno essere adeguatamente rifinite. Recinzioni di altezza superiore dovranno essere realizzate con strutture a giorno.
Per le zone contigue o in diretto rapporto visuale con la zona A, le altezze massime dei nuovi edifici non possono superare altezze compatibili con quelle degli altri edifici della zona 'A' predetta. E' prescritta tra pareti finestrate la distanza minima pari all'altezza del fabbricato più alto.
Il rilascio della concessione edilizia è subordinato alla cessione a titolo gratuito al Comune da parte dei proprietari del comparto di un area di mq 300 per la realizzazione di parcheggi e verde attrezzato.

Zone 'B4' di completamento non assoggettate a Piano Particolareggiato: sono sempre consentiti gli interventi di manutenzione ordinaria e straordinaria, di restauro e risanamento conservativo, la ristrutturazione edilizia e la nuova edificazione anche a seguito di demolizione.
Per tali zone valgono i seguenti parametri:

L'indice fondiario massimo (IF) : 1.70 mc/mq
IC : 0,50 mq/mq.
Il fabbricato previsto può presentare, lungo i fronti stradali, non più di 3 piani fuori terra.
È ammessa la costruzione di un solo piano seminterrato qualora per le particolari condizioni del terreno risultino dislivelli che ne consentano la realizzazione
Gli edifici possono sorgere in aderenza o debbono distare dai confini non meno di m. 4.00. (Nei tratti di strada con tessuto urbano già definito, è possibile, sentito il parere della C.E. derogare a questa norma per conservare l'allineamento dei fabbricati esistenti).
La distanza minima da osservare tra due edifici non in aderenza è pari a ml. 8.00 se le pareti non sono finestrate; ml. 10.00 se le pareti sono finestrate .
Non sono consentiti sbalzi sugli spazi pubblici superiori a cm. 20. I muri di recinzione delle proprietà non dovranno avere un'altezza superiore a mt. 1.00 e le loro superfici dovranno essere adeguatamente rifinite. Recinzioni di altezza superiore dovranno essere realizzate con strutture a giorno.
Per le zone contigue o in diretto rapporto visuale con la zona A, le altezze massime dei nuovi edifici non possono superare altezze compatibili con quelle degli altri edifici della zona 'A' predetta. E' prescritta tra pareti finestrate la distanza minima pari all'altezza del fabbricato più alto.
Il rilascio della concessione edilizia è subordinato alla cessione a titolo gratuito al Comune delle aree necessarie per allargare la strada di S.Giovanni nel tratto prospiciente il comparto, fino a ml. 7.00.

Art. 21 - Deroghe alle distanze minime per le zone A e B

Nelle zone inedificate e risultanti libere a seguito di demolizioni che si estendano sul fronte stradale o in profondità per una lunghezza inferiore a ml. 24

Art. 22 - Lotti interclusi nelle zone B

Nelle zone 'B' i lotti interclusi, cioè non direttamente prospicienti strade pubbliche, potranno essere edificati a condizione che:
il progetto edilizio interessi l'intero lotto;
il progetto preveda la realizzazione di strada pubblica, di accesso ed interna, di ml. 10 che consenta l'agevole circolazione di autovetture;

Firmato Da: CONCHEDDA ANTONIO Emesso Da: INFOCAMERE QUALIFIED ELECTRONIC SIGNATURE CA Serial#: 103d3e

nei casi ove ciò non sia possibile, sentita la Commissione Edilizia, in deroga al PUC, saranno consentite strade aventi in ogni caso larghezza non inferiore a m. 5;
il tipo di intervento suddetto non dovrà in ogni caso essere ubicato in punti che pregiudichino la costruzione di abitazioni in lotti già esistenti;
il progetto preveda le reti idriche, fognarie, di illuminazione esterna, collegamento delle predette infrastrutture alle reti urbane principali, pagamento della quota parte delle spese relative alle opere di urbanizzazione secondarie;
il rilascio della Concessione Edilizia dovrà essere subordinato a stipula di convenzione, per la realizzazione delle opere di cui al punto e), le spese relative all'atto notarile, alla registrazione dello stesso, alla sottoscrizione di fideiussione assicurativa, saranno a totale carico del richiedente;
le opere di cui ai punti b) c) ed e) dovranno essere gravate di servitù di uso pubblico registrata e trascritta.
Le norme precedenti non valgono nel caso in cui il proprietario del lotto intercluso intenda edificare l'area creando un condominio privato, ma a condizione che il proprietario assuma gli oneri della urbanizzazione e degli allacciamenti .

Art. 23 - Piani Particolareggiati nelle Zone B1 e B2

Con ricorso a Piano attuativo è consentito utilizzare un indice fondiario fino a 5 mc/mq

REGOLARITÀ EDILIZIA

Sulla base della documentazione fornità dall'ufficio protocollo del Comune di Ittiri, l'immobile risulta essere stato edificato in data antecedente al 01/09/1967 e successivamente oggetto di presentazione/rilascio dei seguenti titoli autorizzativi:
- Licenza di costruzione n° 649, prat. edil. n° 47/1965 rilasciata del Comune di Ittiri in data 27/04/1965, relativa alla modifica del fabbricato;
- C.E. n° 38, prat. edil. n° 67/2000, rilasciata del Comune di Ittiri in data 21/05/2001, relativa a ristrutturazione e cambio di destinazione d'uso;
- Suap n° prot. n° 608, presentata al Comune di Ittiri in data 25/01/2023, relativa a interventi di ristrutturazione edilizia;
- Suap n° prot. n° 2136, presentata al Comune di Ittiri in data 22/03/2024, relativa a variante in corso d'opera.

Negli archivi dell'ufficio tecnico del Comune di Ittiri non risulta presente documentazione attestante presentazione/richiesta/rilascio del certificato di agibilità/abitabilità.

L'immobile risulta conforme al progetto allegato all'ultimo titolo autorizzativo presentato.

VINCOLI OD ONERI CONDOMINIALI

Non si é a conoscenza di presenza di vincoli od oneri condominiali.

Firmato Da: CONCHEDDA ANTONIO Emesso Da: INFOCAMERE QUALIFIED ELECTRONIC SIGNATURE CA Serial#: 103d3e

Non risulta costituito un condominio e non sono presenti oneri condominiali.

STIMA / FORMAZIONE LOTTI

Lo scrivente ha ritenuto opportuno procedere alla formazione di un lotto unico cosi costituito:

- **Bene N° 1** - Appartamento ubicato a Ittiri (SS) - Via Amsicora 53
  Oggetto della presente perizia è un fabbricato adibito ad uso residenziale posto ai piani terra/primo, ubicato all'interno del perimetro urbano dell'abitato del Comune di Ittiri, in posizione semicentrale, più precisamente in via Amsicora n° 53. La zona in cui insiste il cespite si presenta completamente edificata con tipologia costruttiva del tutto simile al bene in oggetto e risulta intensamente percorsa da traffico veicolare e pedonale con discreta viabilità e discreta possibilità di parcheggio. Buoni i collegamenti con le principali arterie stradali della regione Sardegna da e per la città di Ittiri, quali la SP28, SP15, SS131 bis e SS 131 Carlo Felice. Il cespite ha accesso diretto dalla porta d'ingresso posta in affaccio sulla pubblica viabilità. L'immobile da progetto autorizzato risulta composto da: -Piano terra: ampio vano adibito a locale sgombero, bagno, ripostiglio, vano scala, corte esclusiva; -Piano primo: soggiorno-cucina, disimpegno, ripostiglio, 2 camere, bagno, vano scala, terrazzo.
  Identificato al catasto Fabbricati - Fg. 73, Part. 775, Sub. 26, Categoria A2
  L'immobile viene posto in vendita per il diritto di Proprietà (1/1)
  Valore di stima del bene: € 155.135,00
  La stima dell'immobile è stata calcolata utilizzando il metodo MCA, effettuando un indagine di mercato su immobili adibiti ad uso abitazione aventi medesime caratteristiche intrinseche ed estrinseche ed ubicati nella medesima località.
  Da tale ricerca si è evinto un valore di vendita compreso tra gli 1.050,00 e i 1.250,00 €/mq. Considerando che tali importi saranno poi oggetto di trattativa in sede di compravendita, il sottoscritto ritiene congruo attribuire all'immobile in oggetto, un parametro Euro/mq pari a 1.150,00.

Identificativo corpo	Superficie convenzionale	Valore unitario	Valore complessivo	Quota in vendita	Totale
Bene N° 1 - Appartamento Ittiri (SS) - Via Amsicora 53	134,90 mq	1.150,00 €/mq	€ 155.135,00	100,00%	€ 155.135,00
				Valore di stima:	€ 155.135,00

Assolto il proprio mandato, il sottoscritto Esperto ex art. 568 c.p.c. deposita la relazione di stima presso questo Spettabile Tribunale, tanto in assolvimento dell'incarico conferitogli dalla S.V. e resta a disposizione per

Firmato Da: CONCHEDDA ANTONIO Emesso Da: INFOCAMERE QUALIFIED ELECTRONIC SIGNATURE CA Serial#: 103d3e

eventuali chiarimenti.

Sassari, li 09/12/2024

L'Esperto ex art. 568 c.p.c.
Ing. Conchedda Antonio

ELENCO ALLEGATI:

- ✓ Estratti di mappa - Allegato 1 - Planimetria catastale CT Foglio 73 mapp. 775
- ✓ Visure e schede catastali - Allegato 2 - Visura catastale storica CF UI F73 mapp775 S26
- ✓ Planimetrie catastali - Allegato 3 - Planimetria catastale CF UI F73 mapp775 S26
- ✓ Planimetrie catastali - Allegato 4 - Elaborato planimetrico parziale CF F73 mapp775
- ✓ Altri allegati - Allegato 5 - Verbale inizio operazioni peritali del 25.11.2024
- ✓ Altri allegati - Allegato 6 - Pratica Edilizia 46_1965
- ✓ Altri allegati - Allegato 7 - Pratica Edilizia 67_2000
- ✓ Altri allegati - Allegato 8 - Ricevuta definitiva Suape del 25.01.2023
- ✓ Altri allegati - Allegato 9 - Ricevuta definitiva Suape del 22.03.2024
- ✓ Tavola del progetto - Allegato 10 - Grafici SUAPE del 25.03.2023 - Tav. 1
- ✓ Altri allegati - Allegato 11 - Grafici SUAPE del 25.03.2023 - Tav. 2
- ✓ Altri allegati - Allegato 12 - Stralcio PUC Comune di Ittiri
- ✓ Certificato destinazione urbanistica - Allegato 13 - CDU
- ✓ Altri allegati - Allegato 14 - Elenco formalità sub. 26
- ✓ Altri allegati - Allegato 15 - Trascrizione del 20.05.2024
- ✓ Altri allegati - Allegato 16 - Elenco formalità sub. 18
- ✓ Altri allegati - Allegato 17 - Elenco formalità sub. 19
- ✓ Altri allegati - Allegato 18 - Trascrizione del 27.05.2010
- ✓ Altri allegati - Allegato 19 - Trascrizione del 07.03.2012
- ✓ Altri allegati - Allegato 20 - Trascrizione del 18.04.2013
- ✓ Altri allegati - Allegato 21 - Trascrizione del 03.08.2015
- ✓ Altri allegati - Allegato 22 - Annotazione del 20.10.2015
- ✓ Altri allegati - Allegato 23 - APE _6_DICEMBRE_2024_ITTIRI_F73_M775_S26.pdf
- ✓ Altri allegati - Allegato 24 - RICEVUTA PEC TRASMISSIONE APE alla RAS

Firmato Da: CONCHEDDA ANTONIO Emesso Da: INFOCAMERE QUALIFIED ELECTRONIC SIGNATURE CA Serial#: 103d3e

- ✓ Foto - Allegato 25 - Documentazione fotografica Ittiri - EI 63-2024

Firmato Da: CONCHEDDA ANTONIO Emesso Da: INFOCAMERE QUALIFIED ELECTRONIC SIGNATURE CA Serial#: 103d3e

RIEPILOGO BANDO D'ASTA

LOTTO UNICO

- **Bene N° 1** - Appartamento ubicato a Ittiri (SS) - Via Amsicora 53
  Oggetto della presente perizia è un fabbricato adibito ad uso residenziale posto ai piani terra/primo, ubicato all'interno del perimetro urbano dell'abitato del Comune di Ittiri, in posizione semicentrale, più precisamente in via Amsicora n° 53. La zona in cui insiste il cespite si presenta completamente edificata con tipologia costruttiva del tutto simile al bene in oggetto e risulta intensamente percorsa da traffico veicolare e pedonale con discreta viabilità e discreta possibilità di parcheggio. Buoni i collegamenti con le principali arterie stradali della regione Sardegna da e per la città di Ittiri, quali la SP28, SP15, SS131 bis e SS 131 Carlo Felice. Il cespite ha accesso diretto dalla porta d'ingresso posta in affaccio sulla pubblica viabilità. L'immobile da progetto autorizzato risulta composto da: -Piano terra: ampio vano adibito a locale sgombero, bagno, ripostiglio, vano scala, corte esclusiva; -Piano primo: soggiorno-cucina, disimpegno, ripostiglio, 2 camere, bagno, vano scala, terrazzo. Identificato al catasto Fabbricati - Fg. 73, Part. 775, Sub. 26, Categoria A2 L'immobile viene posto in vendita per il diritto di Proprietà (1/1) Destinazione urbanistica: Art. 20 - Zone B Le Zone classificate 'B' di completamento sono prevalentemente destinate alla residenza. Gli usi ammessi, con riferimento alle disposizioni delle presenti norme, sono quelli dei Gruppi 1 e 2. Sono suddivise in: Zone 'B1 di completamento non assoggettate a Piano Particolareggiato: sono sempre consentiti gli interventi di manutenzione ordinaria e straordinaria, di restauro e risanamento conservativo, la ristrutturazione edilizia e la nuova edificazione anche a seguito di demolizione. Per tali zone valgono i seguenti parametri: L'indice fondiario massimo (IF) : 3 mc/mq H: ml.9.00 IC : 0.70 mq/mq. Gli edifici possono sorgere in aderenza o debbono distare dai confini non meno di m. 4.00. (Nei tratti di strada con tessuto urbano già definito, è possibile, sentito il parere della C.E. derogare a questa norma per conservare l'allineamento dei fabbricati esistenti). La distanza minima da osservare tra due edifici non in aderenza è pari a ml. 8.00 se le pareti non sono finestrate; ml. 10.00 se le pareti sono finestrate . Non sono consentiti sbalzi sugli spazi pubblici superiori a cm. 20. I muri di recinzione delle proprietà fronteggianti vie o piazze aperte al pubblico transito, non dovranno avere un'altezza superiore a mt. 1.0 perle parti murarie e le loro superfici dovranno essere adeguatamente rifinite. Recinzioni di altezza superiore dovranno essere realizzate con strutture a giorno. I muri divisori dei giardini o dei cortili non visibili da are pubbliche devono avere un'altezza non superiore a ml. 3.00, e dovranno essere realizzati nel rispetto delle norme del Codice Civile. Per le zone contigue o in diretto rapporto visuale con la zona A, le altezze massime dei nuovi edifici non possono superare altezze compatibili con quelle degli altri edifici della zona A predetta. E' prescritta tra pareti finestrate la distanza minima pari all'altezza del fabbricato più alto. Zone 'B2' di completamento non assoggettate a Piano Particolareggiato: sono sempre consentiti gli interventi di manutenzione ordinaria e straordinaria, di restauro e risanamento conservativo, la ristrutturazione edilizia e la nuova edificazione anche a seguito di demolizione. Per tali zone valgono i seguenti parametri: L'indice fondiario massimo (IF) : 3 mc/mq IC : 0,60 mq/mq. Gli edifici possono sorgere in aderenza o debbono distare dai confini non meno di m. 4.00. (Nei tratti di strada con tessuto urbano già definito, è possibile, sentito il parere della C.E. derogare a questa norma per conservare l'allineamento dei fabbricati esistenti). La distanza minima da osservare tra due edifici non in aderenza è pari a ml. 8.00 se le pareti non sono finestrate; ml. 10.00 se le pareti sono finestrate . Non sono consentiti sbalzi sugli spazi pubblici superiori a cm. 20. I muri di recinzione delle proprietà fronteggianti vie o piazze aperte al pubblico transito, non dovranno avere un'altezza superiore a mt. 1.0 perle parti murarie e le loro superfici dovranno essere adeguatamente rifinite. Recinzioni di altezza superiore dovranno essere realizzate con strutture a giorno. I muri divisori dei giardini o dei cortili non visibili da are pubbliche devono avere un'altezza non superiore a ml. 3.00, e dovranno essere realizzati nel rispetto delle norme del Codice Civile. Per le zone contigue o in diretto rapporto visuale con la zona

Firmato Da: CONCHEDDA ANTONIO Emesso Da: INFOCAMERE QUALIFIED ELECTRONIC SIGNATURE CA Serial#: 103d3e

A, le altezze massime dei nuovi edifici non possono superare altezze compatibili con quelle degli altri edifici della zona 'A' predetta. E' prescritta tra pareti finestrate la distanza minima pari all'altezza del fabbricato più alto. Zone 'B3' di completamento non assoggettate a Piano Particolareggiato: sono sempre consentiti gli interventi di manutenzione ordinaria e straordinaria, di restauro e risanamento conservativo, la ristrutturazione edilizia e la nuova edificazione anche a seguito di demolizione. Per tali zone valgono i seguenti parametri: L'indice fondiario massimo (IF) : 1.70 mc/mq H : ml.9.00 IC : 0,50 mq/mq. Il fabbricato previsto può presentare, lungo i fronti stradali, non più di 3 piani fuori terra. È ammessa la costruzione di un solo piano seminterrato qualora per le particolari condizioni del terreno risultino dislivelli che ne consentano la realizzazione Gli edifici possono sorgere in aderenza o debbono distare dai confini non meno di m. 4.00. (Nei tratti di strada con tessuto urbano già definito, è possibile, sentito il parere della C.E. derogare a questa norma per conservare l'allineamento dei fabbricati esistenti). La distanza minima da osservare tra due edifici non in aderenza è pari a ml. 8.00 se le pareti non sono finestrate; ml. 10.00 se le pareti sono finestrate . Non sono consentiti sbalzi sugli spazi pubblici superiori a cm. 20. I muri di recinzione delle proprietà non dovranno avere un'altezza superiore a mt. 1.00 e le loro superfici dovranno essere adeguatamente rifinite. Recinzioni di altezza superiore dovranno essere realizzate con strutture a giorno. Per le zone contigue o in diretto rapporto visuale con la zona A, le altezze massime dei nuovi edifici non possono superare altezze compatibili con quelle degli altri edifici della zona 'A' predetta. E' prescritta tra pareti finestrate la distanza minima pari all'altezza del fabbricato più alto. Il rilascio della concessione edilizia è subordinato alla cessione a titolo gratuito al Comune da parte dei proprietari del comparto di un area di mq 300 per la realizzazione di parcheggi e verde attrezzato. Zone 'B4' di completamento non assoggettate a Piano Particolareggiato: sono sempre consentiti gli interventi di manutenzione ordinaria e straordinaria, di restauro e risanamento conservativo, la ristrutturazione edilizia e la nuova edificazione anche a seguito di demolizione. Per tali zone valgono i seguenti parametri: L'indice fondiario massimo (IF) : 1.70 mc/mq IC : 0,50 mq/mq. Il fabbricato previsto può presentare, lungo i fronti stradali, non più di 3 piani fuori terra. È ammessa la costruzione di un solo piano seminterrato qualora per le particolari condizioni del terreno risultino dislivelli che ne consentano la realizzazione Gli edifici possono sorgere in aderenza o debbono distare dai confini non meno di m. 4.00. (Nei tratti di strada con tessuto urbano già definito, è possibile, sentito il parere della C.E. derogare a questa norma per conservare l'allineamento dei fabbricati esistenti). La distanza minima da osservare tra due edifici non in aderenza è pari a ml. 8.00 se le pareti non sono finestrate; ml. 10.00 se le pareti sono finestrate . Non sono consentiti sbalzi sugli spazi pubblici superiori a cm. 20. I muri di recinzione delle proprietà non dovranno avere un'altezza superiore a mt. 1.00 e le loro superfici dovranno essere adeguatamente rifinite. Recinzioni di altezza superiore dovranno essere realizzate con strutture a giorno. Per le zone contigue o in diretto rapporto visuale con la zona A, le altezze massime dei nuovi edifici non possono superare altezze compatibili con quelle degli altri edifici della zona 'A' predetta. E' prescritta tra pareti finestrate la distanza minima pari all'altezza del fabbricato più alto. Il rilascio della concessione edilizia è subordinato alla cessione a titolo gratuito al Comune delle aree necessarie per allargare la strada di S.Giovanni nel tratto prospiciente il comparto, fino a ml. 7.00. Art. 21 - Deroghe alle distanze minime per le zone A e B Nelle zone inedificate e risultanti libere a seguito di demolizioni che si estendano sul fronte stradale o in profondità per una lunghezza inferiore a ml. 24 Art. 22 - Lotti interclusi nelle zone B Nelle zone 'B' i lotti interclusi, cioè non direttamente prospicienti strade pubbliche, potranno essere edificati a condizione che: il progetto edilizio interessi l'intero lotto; il progetto preveda la realizzazione di strada pubblica, di accesso ed interna, di ml. 10 che consenta l'agevole circolazione di autovetture; nei casi ove ciò non sia possibile, sentita la Commissione Edilizia, in deroga al PUC, saranno consentite strade aventi in ogni caso larghezza non inferiore a m. 5; il tipo di intervento suddetto non dovrà in ogni caso essere ubicato in punti che pregiudichino la costruzione di abitazioni in lotti già esistenti; il progetto preveda le reti idriche, fognarie, di illuminazione esterna, collegamento delle predette infrastrutture alle reti urbane principali, pagamento della quota parte delle spese relative alle opere di urbanizzazione secondarie; il rilascio della Concessione Edilizia dovrà essere subordinato a stipula di convenzione, per la realizzazione delle opere di cui al punto e), le spese relative all'atto notarile, alla registrazione dello stesso, alla sottoscrizione di fideiussione assicurativa, saranno a totale carico del richiedente; le opere

Firmato Da: CONCHEDDA ANTONIO Emesso Da: INFOCAMERE QUALIFIED ELECTRONIC SIGNATURE CA Serial#: 103d3e

di cui ai punti b) c) ed e) dovranno essere gravate di servitù di uso pubblico registrata e trascritta. Le norme precedenti non valgono nel caso in cui il proprietario del lotto intercluso intenda edificare l'area creando un condominio privato, ma a condizione che il proprietario assuma gli oneri della urbanizzazione e degli allacciamenti . Art. 23 - Piani Particolareggiati nelle Zone B1 e B2 Con ricorso a Piano attuativo è consentito utilizzare un indice fondiario fino a 5 mc/mq

Firmato Da: CONCHEDDA ANTONIO Emesso Da: INFOCAMERE QUALIFIED ELECTRONIC SIGNATURE CA Serial#: 103d3e

SCHEMA RIASSUNTIVO
ESECUZIONE IMMOBILIARE 63/2024 DEL R.G.E.

LOTTO UNICO

Bene N° 1 - Appartamento			
Ubicazione:	Ittiri (SS) - Via Amsicora 53		
Diritto reale:	Proprietà	**Quota**	1/1
Tipologia immobile:	Appartamento Identificato al catasto Fabbricati - Fg. 73, Part. 775, Sub. 26, Categoria A2	**Superficie**	134,90 mq
Stato conservativo:	L'immobile al momento del sopralluogo si presentava in discreto stato manutenzione e conservazione complessivo.		
Descrizione:	Oggetto della presente perizia è un fabbricato adibito ad uso residenziale posto ai piani terra/primo, ubicato all'interno del perimetro urbano dell'abitato del Comune di Ittiri, in posizione semicentrale, più precisamente in via Amsicora n° 53. La zona in cui insiste il cespite si presenta completamente edificata con tipologia costruttiva del tutto simile al bene in oggetto e risulta intensamente percorsa da traffico veicolare e pedonale con discreta viabilità e discreta possibilità di parcheggio. Buoni i collegamenti con le principali arterie stradali della regione Sardegna da e per la città di Ittiri, quali la SP28, SP15, SS131 bis e SS 131 Carlo Felice. Il cespite ha accesso diretto dalla porta d'ingresso posta in affaccio sulla pubblica viabilità. L'immobile da progetto autorizzato risulta composto da: -Piano terra: ampio vano adibito a locale sgombero, bagno, ripostiglio, vano scala, corte esclusiva; -Piano primo: soggiorno-cucina, disimpegno, ripostiglio, 2 camere, bagno, vano scala, terrazzo.		
Vendita soggetta a IVA:	N.D.		
Stato di occupazione:	L'immobile al momento del sopralluogo risultava occupato dall'esecutato.		

Firmato Da: CONCHEDDA ANTONIO Emesso Da: INFOCAMERE QUALIFIED ELECTRONIC SIGNATURE CA Serial#: 103d3e

Fotografia n° 1

Vista esterno fabbricato

Fotografia n° 2

Vista esterno fabbricato

Fotografia n° 3

Vista esterno fabbricato

Fotografia n° 20

Vista interno U.I.

ATTESTATO DI PRESTAZIONE ENERGETICA DEGLI EDIFICI

CODICE IDENTIFICATIVO: 013/2024 VALIDO FINO AL: 05/12/2034

APE 2015

DATI GENERALI

Destinazione d'uso

- [X] Residenziale
- [ ] Non residenziale

Classificazione D.P.R. 412/93:
E.1 (1) - Edificio adibito a residenza con carattere continuativo

Oggetto dell'attestato

- [ ] Intero edificio
- [X] Unità immobiliare
- [ ] Gruppo di unità immobiliari

Numero di unità immobiliari di cui è composto l'edificio: 15

- [ ] Nuova costruzione
- [X] Passaggio di proprietà
- [ ] Locazione
- [ ] Ristrutturazione importante
- [ ] Riqualificazione energetica
- [ ] Altro: _____

Dati identificativi

Regione : Sardegna
Comune : Ittiri (SS)
Indirizzo : Via Amsicora 53
Piano : T-1
Interno :
Coordinate GIS : 40,59594 N; 8,56864 E

Zona climatica : D
Anno di costruzione: 1966
Superficie utile riscaldata: 133,03 m²
Superficie utile raffrescata: 133,03 m²
Volume lordo riscaldato: 549,51 m³
Volume lordo raffrescato: 549,51 m³

Comune catastale			Ittiri (SS)						Sezione				Foglio		73		Particella		775	
Subalterni	da	26	a	26		da		a			da		a			da		a		
Altri subalterni																				

Servizi energetici presenti

- [X] Climatizzazione invernale
- [X] Climatizzazione estiva
- [ ] Ventilazione meccanica
- [X] Prod. acqua calda sanitaria
- [ ] Illuminazione
- [ ] Trasporto di persone o cose

PRESTAZIONE ENERGETICA GLOBALE E DEL FABBRICATO

La sezione riporta l'indice di prestazione energetica globale non rinnovabile in funzione del fabbricato e dei servizi energetici presenti, nonché la prestazione energetica del fabbricato, al netto del rendimento degli impianti presenti.

Prestazione energetica del fabbricato

INVERNO	ESTATE

Prestazione energetica globale

+ Più efficiente

A4 A3 A2 A1 B C D E F G

— Meno efficiente

EDIFICIO A ENERGIA QUASI ZERO [ ]

CLASSE ENERGETICA D

EPgl,nren
128,14
kWh/m² anno

Riferimenti

Gli immobili simili a questo avrebbero in media la seguente classificazione:

Se nuovi: A2 (66,31)

Se esistenti:

Firmato Da: CONCHEDDA ANTONIO Emesso Da: INFOCAMERE QUALIFIED ELECTRONIC SIGNATURE CA Serial#: 103d3e

PRESTAZIONE ENERGETICA DEGLI IMPIANTI E CONSUMI STIMATI

La sezione riporta l'indice di prestazione energetica rinnovabile e non rinnovabile, nonché una stima dell'energia consumata annualmente dall'immobile secondo un uso standard.

Prestazioni energetiche degli impianti e stima dei consumi annui di energia

	FONTI ENERGETICHE UTILIZZATE	Quantità annua consumata in uso standard (specificare unità di misura)	Indici di prestazione energetica globali ed emissioni
X	Energia elettrica da rete	4.380 kWh	Indice della prestazione energetica non rinnovabile $EP_{gl,nren}$ kWh/m² anno 128,14
	Gas naturale		
X	GPL	190 Sm³	
	Carbone		
	Gasolio e Olio combustibile		
X	Biomasse solide	3.230 kg	Indice della prestazione energetica rinnovabile $EP_{gl,ren}$ kWh/m² anno 197,29
	Biomasse liquide		
	Biomasse gassose		
	Solare fotovoltaico		
	Solare termico		
	Eolico		Emissioni di CO_2 kg/m² anno 29,41
	Teleriscaldamento		
	Teleraffrescamento		
	Altro (specificare)		

RACCOMANDAZIONI

La sezione riporta gli interventi raccomandati e la stima dei risultati conseguibili, con il singolo intervento o con la realizzazione dell'insieme di essi, esprimendo una valutazione di massima del potenziale di miglioramento dell'edificio o immobile oggetto dell'attestato di prestazione energetica.

RIQUALIFICAZIONE ENERGETICA E RISTRUTTURAZIONE IMPORTANTE
INTERVENTI RACCOMANDATI E RISULTATI CONSEGUIBILI

Codice	TIPO DI INTERVENTO RACCOMANDATO	Comporta una Ristrutturazione importante	Tempo di ritorno dell'investimento anni	Classe Energetica Raggiungibile con l'intervento ($EP_{gl,nren}$ kWh/m² anno)	CLASSE ENERGETICA raggiungibile se si realizzano tutti gli interventi raccomandati
REN2	Involucro trasparente del fabbricato	No		C (125,53 kWh/m² anno)	C 125,53 kWh/m² anno

Firmato Da: CONCHEDDA ANTONIO Emesso Da: INFOCAMERE QUALIFIED ELECTRONIC SIGNATURE CA Serial#: 103d3e

ALTRI DATI ENERGETICI GENERALI

Energia esportata	**0 kWh/anno**	**Vettore energetico:**

ALTRI DATI DI DETTAGLIO DEL FABBRICATO

V – Volume riscaldato	549,51	**m³**
S – Superficie disperdente	471,42	**m²**
Rapporto S/V	0,858	
$EP_{H,nd}$	143,56	**kWh/m² anno**
$A_{sol,est}/A_{sup\ utile}$	0,0772	**-**
Y_{IE}	0,1740	**W/m²K**

DATI DI DETTAGLIO DEGLI IMPIANTI

Servizio energetico	Tipo di impianto	Anno di installazione	Codice catasto regionale impianti termici	Vettore energetico utilizzato	Potenza Nominale kW	Efficienza media stagionale		EP_{ren}	EP_{nren}
Climatizzazione invernale	**Stufa o caminetto**	2023		Biomasse solide, Energia elettrica da rete	5,00	0,51	η_H	196,17	83,27
	PDC elettrica aria-aria	2023		Energia elettrica da rete	3,80				
Climatizzazione estiva	**PDC elettrica aria-aria**	2023		Energia elettrica da rete	3,50	1,10	η_C	0,59	2,44
Prod. acqua calda sanitaria	**Caldaia standard**	2023		GPL, Energia elettrica da rete	23,00	0,34	η_W	0,53	42,43
Impianti combinati									
Prod. da fonti rinnovabili	**Stufa o caminetto**	2023		Biomasse solide	5,00				
	PDC elettrica aria-aria	2023		Energia elettrica da rete	3,80				
Ventilazione meccanica									
Illuminazione									
Trasporto di persone o cose									

Firmato Da: CONCHEDDA ANTONIO Emesso Da: INFOCAMERE QUALIFIED ELECTRONIC SIGNATURE CA Serial#: 103d3e

INFORMAZIONI SUL MIGLIORAMENTO DELLA PRESTAZIONE ENERGETICA

La sezione riporta informazioni sulle opportunità, anche in termini di strumenti di sostegno nazionali o locali, legate all'esecuzione di diagnosi energetiche e interventi di riqualificazione energetica, comprese le ristrutturazioni importanti.

Data sopralluogo: 25/11/2024

SOGGETTO CERTIFICATORE

☐ Ente/Organismo pubblico	☒ Tecnico abilitato	☐ Organismo/Società

Nome e Cognome / Denominazione	Antonio Conchedda
Indirizzo	Via degli Astronauti 3/D, Sassari
E-mail	a.c.ingegneria@gmail.com
Telefono	
Titolo	Ingegnere
Ordine/iscrizione	Ordine degli Ingegneri della Provincia di Sassari al n° 65B
Dichiarazione di indipendenza	Il sottoscritto certificatore, consapevole delle responsabilità assunte ai sensi degli artt.359 e 481 del Codice Penale, DICHIARA di aver svolto con indipendenza ed imparzialità di giudizio l'attività di Soggetto Certificatore del sistema edificio impianto oggetto del presente attestato e l'assenza di conflitto di interessi ai sensi dell'art.3 del D.P.R. 16 aprile 2013, n. 75.
Informazioni aggiuntive	

SOPRALLUOGHI E DATI DI INGRESSO

È stato eseguito almeno un sopralluogo/rilievo sull'edificio obbligatorio per la redazione del presente APE	**Sì**

SOFTWARE UTILIZZATO

Il software utilizzato risponde ai requisiti di rispondenza e garanzia di scostamento massimo dei risultati conseguiti rispetto ai valori ottenuti per mezzo dello strumento di riferimento nazionale?	**Sì**
Ai fini della redazione del presente attestato è stato utilizzato un software che impieghi un metodo di calcolo semplificato?	**No**

Il presente attestato è reso, dal sottoscritto, in forma di dichiarazione sostitutiva di atto notorio ai sensi dell'articolo 47 del D.P.R. 445/2000 e dell'articolo 15, comma 1 del D.Lgs 192/2005 così come modificato dall'articolo 12 del D.L 63/2013.

Data di emissione: 06/12/2024 **Firma e timbro del tecnico o firma digitale**_____

Firmato Da: CONCHEDDA ANTONIO Emesso Da: INFOCAMERE QUALIFIED ELECTRONIC SIGNATURE CA Serial#: 103d3e

LEGENDA E NOTE PER LA COMPILAZIONE

Il presente documento attesta la **prestazione** e la **classe energetica** dell'edificio o dell'unità immobiliare, ovvero la quantità di energia necessaria ad assicurare il comfort attraverso i diversi servizi erogati dai sistemi tecnici presenti, in condizioni convenzionali d'uso. Al fine di individuare le potenzialità di miglioramento della prestazione energetica, l'attestato riporta informazioni specifiche sulle prestazioni energetiche del fabbricato e degli impianti. Viene altresì indicata la classe energetica più elevata raggiungibile in caso di realizzazione delle misure migliorative consigliate, così come descritte nella sezione **"raccomandazioni"** (pag.2).

PRIMA PAGINA

Informazioni generali: tra le informazioni generali è riportata la motivazione alla base della redazione dell'APE. Nell'ambito del periodo di validità, ciò non preclude l'uso dell'APE stesso per i fini di legge, anche se differenti da quelli ivi indicati.
Prestazione energetica globale (EPgl,nren): fabbisogno annuale di energia primaria non rinnovabile relativa a tutti i servizi erogati dai sistemi tecnici presenti, in base al quale è identificata la classe di prestazione dell'edificio in una scala da A4 (edificio più efficiente) a G (edificio meno efficiente).
Prestazione energetica del fabbricato: indice qualitativo del fabbisogno di energia necessario per il soddisfacimento del confort interno, indipendente dalla tipologia e dal rendimento degli impianti presenti. Tale indice da un'indicazione di come l'edificio, d'estate e d'inverno, isola termicamente gli ambienti interni rispetto all'ambiente esterno. La scala di valutazione qualitativa utilizzata osserva il seguente criterio:

QUALITA' ALTA	QUALITA' MEDIA	QUALITA' BASSA

I valori di soglia per la definizione del livello di qualità, suddivisi per tipo di indicatore, sono riportati nelle Linee guida per l'attestazione energetica degli edifici di cui al decreto previsto dall'articolo 6, comma 12 del d.lgs. 192/2005.
Edificio a energia quasi zero: edificio ad altissima prestazione energetica, calcolata conformemente alle disposizioni del decreto legislativo 19 agosto 2005, n. 192 e del decreto ministeriale sui requisiti minimi previsto dall'articolo 4, comma 1 del d.lgs. 192/2005. Il fabbisogno energetico molto basso o quasi nullo è coperto in misura significativa da energia da fonti rinnovabili, prodotta all'interno del confine del sistema (in situ). Una spunta sull'apposito spazio adiacente alla scala di classificazione indica l'appartenenza dell'edificio oggetto dell'APE a questa categoria.
Riferimenti: raffronto con l'indice di prestazione globale non rinnovabile di un edificio simile ma dotato dei requisiti minimi degli edifici nuovi, nonché con la media degli indici di prestazione degli edifici esistenti simili, ovvero contraddistinti da stessa tipologia d'uso, tipologia costruttiva, zona climatica, dimensioni ed esposizione di quello oggetto dell'attestato.

SECONDA PAGINA

Prestazioni energetiche degli impianti e consumi stimati: la sezione riporta l'indice di prestazione energetica rinnovabile e non rinnovabile dell'immobile oggetto di attestazione. Tali indici informano sulla percentuale di energia rinnovabile utilizzata dall'immobile rispetto al totale. La sezione riporta infine una stima del quantitativo di energia consumata annualmente dall'immobile secondo un uso standard, suddivisi per tipologia di fonte energetica utilizzata.
Raccomandazioni: di seguito si riporta la tabella che classifica le tipologie di intervento raccomandate per la riqualificazione energetica e la ristrutturazione importante.

RIQUALIFICAZIONE ENERGETICA E RISTRUTTURAZIONE IMPORTANTE EDIFICIO/UNITA' IMMOBILIARE - Tabella dei Codici

Codice	TIPO DI INTERVENTO
REN 1	FABBRICATO - INVOLUCRO OPACO
REN 2	FABBRICATO - INVOLUCRO TRASPARENTE
REN 3	IMPIANTO CLIMATIZZAZIONE - INVERNO
REN 4	IMPIANTO CLIMATIZZAZIONE - ESTATE
REN 5	ALTRI IMPIANTI
REN 6	FONTI RINNOVABILI

TERZA PAGINA

La terza pagina riporta la quantità di energia prodotta in situ ed esportata annualmente, nonché la sua tipologia.
Riporta infine, suddivise in due sezioni relative rispettivamente al fabbricato e agli impianti, i dati di maggior dettaglio alla base del calcolo.

Firmato Da: CONCHEDDA ANTONIO Emesso Da: INFOCAMERE QUALIFIED ELECTRONIC SIGNATURE CA Serial#: 103d3e

STUDIO TECNICO

Geom. [redacted]

PROGETTO

per una modifica da apportare alla casa urbana sita in Ittiri, Via Ansicora 53, di proprietà dei coniugi

[redacted]

e [redacted]

Disegni 1:100

Ittiri, li 12 FEB. 1965

Il tecnico

COLLEGIO GEOMETRI PROVINCIA SASSARI N. 465 Geom. [redacted]

COMUNE DI ITTIRI

UFFICIO TECNICO

Progetto allegato alla richiesta N. 46 del 12.2.65

Esaminato dalla Commissione Edilizia nella seduta del 26.4.65

Verb. n. 3 dal Sindaco con provvedimento N. 46 del 26.4.65

NULLA-OSTA

IL SINDACO

Ittiri, 27.4.65

IL GEOMETRA CAPO

47

COMUNE DI ITTIRI

(Prov. di Sassari)

n. 649

LICENZA DI COSTRUZIONE

di fabbricato urbano.

IL SINDACO

Vista la domanda in data 12.2.65 per Modifica di fabbricato;

Visti i disegni allegati alla domanda suddetta;

Visto l'art.220 del T.U.delle leggi sanitarie D.L.27/7/1934,n.1265;

Sentito il parere dell'Ufficiale Sanitario;

Sentito il parere della Commissione edilizia comunale;

Visto l'art.31 della legge 17/8/1942,n.1150;

DA' LICENZA

Al signor [redacted]

residente a [redacted] via [redacted] n. [redacted]

PER

Modifica di un fabbricato in via Ansicora n. 53 per un complesso di n. — vani nuovi come indicato nella copia del disegno che si restituisce debitamente munita del prescritto "NULLA OSTA" di questo Ufficio.

Ittiri, li 27.4.65

IL SINDACO

Stato Attuale

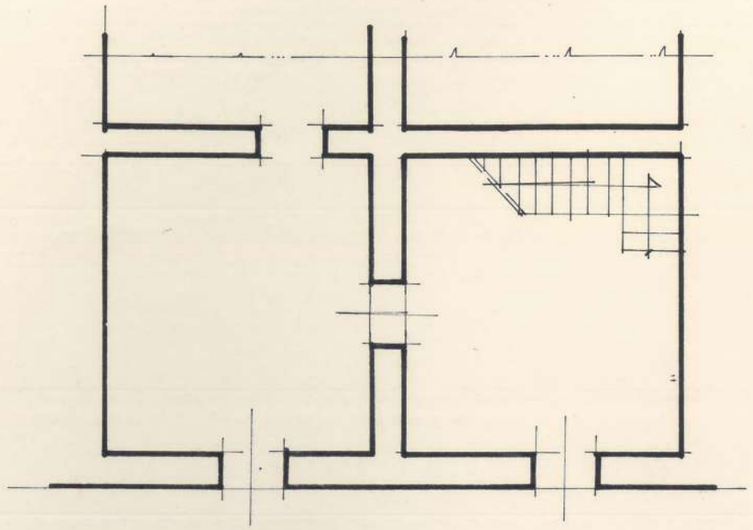

Pianta p.t.



Prospetto

In Progetto

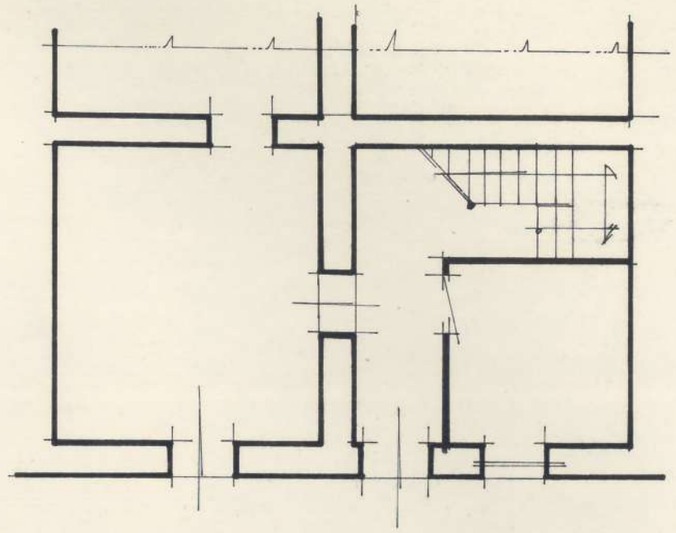

Pianta p.t.



Prospetto

PRESCRIZIONI PARTICOLARI DA OSSERVARE:

A) Contributi per il rilascio della concessione (Art. 3 legge 28- 1-1977 n. 10 "Bucalossi").

1) CONTRIBUTO COMMISURATO ALL'INCIDENZA DELLE OPERE DI URBANIZZAZIONE:
Pagato acconto 50% lire 657.150 con bolletta postale n°27 del 16.05.2001;

2) CONTRIBUTO A PERCENTUALE SUL COSTO DI COSTRUZIONE:
Pagato acconto 25% lire 1.355.825 con bolletta postale n°27 del 16.05.2001;

3) GARANZIA:
Stipulato polizza fidejussoria con la compagnia Vittoria Assicurazioni in data 18.05.2001 n°510/71/900531 per il pagamento rateizzato degli oneri concessori.

B) Diritti di segreteria (ai sensi dispos. di cui art. 16, comma 10, D.L. 17.3.1992 n. 223.:
£. 30.000 versate a mezzo bollettino c.c. postale N° 12512075 intestato al Comune di Ittiri (Uff. Post. di ITTIRI)

C) Condizioni particolari da osservare:
Se gli uffici al primo piano sono aperti al pubblico è necessario l'adeaguamento alla normativa sulla barriere architettoniche.

Dalla Residenza Municipale, li 21 MAG. 2001

IL RESPONSABILE DELL'UFFICIO
TECNICO COMUNALE

Il sottoscritto concessionario si obbliga all'osservanza di tutte le prescrizioni contenute nella presente concessione edilizia.

Addì,

IL CONCESSIONARIO

N.B. Qualora nel corso della realizzazione delle opere o comunque di lavori coevi successivi vengano alla luce documenti e beni culturali soggetti alla tutela della legge 1-6-1939, n. 1089 e successive modifiche,

COMUNE DI ITTIRI
PROVINCIA DI SASSARI

Pratica Edilizia n° **67/2000**

CONCESSIONE EDILIZIA N° 38

IL RESPONSABILE DELL'UFFICIO TECNICO COMUNALE

- **Vista** la domanda di concessione in data **23.02.2001**, prot. n° **2565**, presentata dal Sig. nato a ed ivi residente in via , in qualità di titolare dell'impresa edile , relativa alla esecuzione di lavori consistenti in: **Ristrutturazione e cambio di destinazione d'uso del fabbricato sito nella via Amsicora n°30,** su Immobile distinto al **NCEU** del comune censuario di **Ittiri** al **Foglio 73 mappale n°772/1;**

- **Visti** i disegni di progetto allegati alla domanda a firma dell'Arch. ;

- **Vista** la relazione-parere dell'Ufficio Tecnico Comunale;

- **Visto** il parere della Commissione Edilizia espresso nella seduta del 19.03.2001 verb.n° 4;

- **Visto** il parere dell'Ufficiale Sanitario in data 16.05.2001;

- **Visti** i regolamenti comunali di edilizia, igiene e polizia urbana in vigore;

- **Viste** le leggi 17-08-1942 n. 1150; 06-08-1967 n. 765 e le successive modificazioni ed integrazioni;

- **Vista** la legge 28-01-1977 n. 10;

- **Vista** la legge 28-02-1985 n. 47 e successive modificazioni e integrazioni;

- **Vista** la Legge Regionale 11-10-1985 n. 23 e successive modificazioni e integrazioni;

- **Vista** la Legge n°127/97 sul rilascio delle concessioni edilizie e la disposizione del 30.05.1997 prot. 6892;

- **Accertata**, sulla base della documentazione in atti, la sussistenza di titolo ad ottenere il rilascio della concessione da parte del richiedente;

- **Preso atto** della conformità degli atti progettuali allo strumento urbanistico vigente;

CONCEDE

al richiedente succitato di eseguire i lavori e le opere di cui in narrativa, *salvi e riservati diritti di terzi*, sotto l'osservanza delle vigenti disposizioni in materia di edilizia e di polizia locale, in conformità del progetto approvato che si allega alla presente e ne forma parte integrante e sostanziale, secondo le migliori norme d'arte, affinché l'opera riesca solida, igienica, decorosa e atta alla sua destinazione, tanto per i materiali usati quando per il sistema costruttivo adottato. E' fatto obbligo al concessionario del rispetto e adempimento delle prescrizioni generali e particolari, e delle clausole di seguito riportate:

PRESCRIZIONI GENERALI DA OSSERVARE

1) In caso di nuova costruzione o di ampliamento planimetrico, i lavori non potranno avere materiale inizio prima di aver ottenuto, previa richiesta scritta sui modelli forniti dal comune, la determinazione dei punti fissi di linea e di livello a cura dell'Ufficio Tecnico Comunale, che rilascerà apposito verbale.
Saranno ammessi i soli lavori preparatori di cantiere, il picchettamento, gli scavi di sbancamento e di fondazione in conformità agli elaborati progettuali.

2) In caso di sopraelevazione o di altri interventi a carico di immobili, escluso il solo ampliamento planimetrico, i lavori potranno avere inizio previa denuncia scritta al Comune, almeno tre giorni prima della data di inizio.

3) Qualora non siano stati indicati nella domanda di Concessione il nominativo e l'indirizzo dell'Esecutore, del direttore dei lavori, come di regola deve avvenire, il concessionario è tenuto ugualmente a segnalarli per iscritto all'Ufficio Tecnico Comunale, prima dell'inizio dei lavori.
Nel caso di sostituzione dell'Impresa esecutrice o del direttore dei lavori, titolare della concessione dovrà darne immediata notizia segnalando i nuovi nominativi, entro otto giorni dalla effettiva sostituzione.

4) Di massima non devono mai ingombrarsi le vie e gli spazi pubblici adiacenti al luogo dei lavori e devono essere osservate tutte le cautele atte a rimuovere ogni pericolo di danno a persone e a cose.

5) Occorrendo l'occupazione di tali vie e spazi, deve essere richiesta l'apposita autorizzazione del Sindaco, per iscritto.
Le aree così occupate devono essere restituite nel pristino stato, a lavoro ultimato o anche prima, nel caso i lavori venissero abbandonati o sospesi oltre un certo tempo.

6) Il luogo destinato all'opera deve essere chiuso con assito lungo i lati prospicienti le vie e gli spazi pubblici, salvo esenzione scritta del Sindaco in caso di opere di limitata importanza.

7) Se nel manomettere il suolo pubblico il costruttore incontrasse impianti di servizi pubblici, deve essere usata ogni cautela per non danneggiarli e essere dato subito avviso per i provvedimenti del caso.

8) Gli assiti di cui al paragrafo 6) od altri ripari devono essere imbiancati agli angoli salienti a tutta altezza e devono essere muniti pure, gli angoli, di una lanterna a vetri rossi da mantenersi accesa dal tramonto al levare del sole, secondo l'intero orario della illuminazione stradale. Questa lanterna deve avere dimensioni tale da rendere facilmente visibile il recinto o il riparo su cui è collocata.

9) Ai sensi e per gli effetti della legge 1086 del 5 novembre 1971, relativa alle norme per la costruzione delle opere in conglomerato cementizio armato, normale o precompresso, o a struttura metallica, è fatto obbligo al concessionario:
a) di presentare denuncia al Genio Civile prima di iniziare le opere in c.a. o a struttura metallica;
b) di presentare al Sindaco, al termine dei lavori, il certificato di collaudo delle opere vistato dal Genio Civile, onde ottenere l'abitabilità.

10) In tutti i cantieri deve essere affissa, in vista del pubblico, una tabella in cui siano indicati:
a) Nome e cognome del concessionario, oggetto ed estremi della concessione e termini di scadenza;
b) Nome, cognome e titolo professionale del progettista e direttore dei lavori; denominazione dell'assuntore o indicazione che i lavori sono eseguiti in economia; orario di lavoro.

11) I Lavori devono essere eseguiti nelle forme e quantità riportate nel progetto approvato.

12) Devono essere rispettate le destinazioni d'uso e le unità immobiliari individuate nel progetto stesso.

13) Il committente titolare della concessione, il direttore dei lavori e l'assuntore dei lavori sono tenuti all'integrale osservanza del Regolamento Edilizio Vigente, delle leggi e regolamenti in materia di Edilizia, Urbanistica, di occupazione di suolo pubblico, di sicurezza pubblica, polizia urbana, circolazione Etc.;
sono quindi responsabili di ogni inosservanza così delle norme generali di legge e di Regolamento come delle modalità esecutive fissate nella presente concessione. In caso di inosservanza si applicheranno le sanzioni previste dalla legge 28-02-1985 n. 47 e successive modificazioni e integrazioni, nonché le sanzioni della L.R. 11-10-1985 n.23;

14) **L'inizio dei lavori deve avvenire entro il termine di un anno dalla data della presente concessione** e il concessionario deve darne preventiva comunicazione, su apposito modulo, al Comune, e deve constare da verbale sopralluogo redatto da un funzionario dell'Ufficio Tecnico Comunale;

15) **Il termine di ultimazione, entro il quale l'opera deve essere abitabile o agibile, è stabilito in tre anni dall'effettivo inizio dei lavori;** tale termine può essere prorogato, con provvedimento motivato del Responsabile dell'Ufficio Tecnico Comunale, solo per fatti estranei alla volontà del concessionario, che siano sopravvenuti a ritardare i lavori durante la loro esecuzione; l'ultimazione deve essere denunciata dal concessionario contestualmente con la richiesta di abitabilità o usabilità;

16) Qualora i lavori non siano ultimati nel termine così stabilito, il concessionario deve presentare istanza diretta ad ottenere una nuova concessione; in tal caso la nuova concessione concerne la parte non ultimata;

17) La presente concessione è trasferibile ai successori o aventi causa. Essa non incide sulla titolarità della proprietà, o di altri diritti reali relativi agli immobili realizzati per effetto del suo rilascio, ed è irrevocabile, fatti i casi di decadenza ai sensi della legge 28-2-1985 n. 47 e successive modificazione e integrazioni e della L.R. 11-10-1985 n. 23;

18) Al Comune è riservato il diritto di far eseguire, in qualsiasi momento durante il corso dei lavori, ispezioni e visite di controllo da parte dei funzionari di polizia urbana o dell'Ufficio Tecnico Comunale al fine di accertare la rispondenza dei lavori alle previsioni progettuali originarie, ovvero a quelle di eventuali varianti assentite dal Comune mediante nuova concessione o appendice alla presente;

19) I Materiali terrosi e tutti gli altri materiali provenienti da scavi o demolizioni, quando non siano utilizzabili, devono essere trasferiti in giornata, nell'apposito luogo di scarico pubblico;

20) Per tutte le eventualità non previste nel presente elenco di prescrizioni generali, necessariamente limitato, ci si richiama alle disposizioni del regolamento edilizio comunale e di tutta la normativa in materia edilizia, igiene e polizia locale vigente al momento del rilascio della presente concessione.

COMUNE DI ITTIRI

UFFICIO TECNICO

Progetto allegato alla richiesta N. 07/2000 del 23/02/2001

Esaminato dalla Commissione Edilizia nella seduta del 19/3/2001

verb. 4

NULLA OSTA

Per le condizioni riportate nella concessione edilizia.

Ittiri, 21 MAG. 2001

COMUNE DI ITTIRI - UFFICIO TECNICO

IL TECNICO INCARICATO
(Geom. Pisanu G. Giacomo)

ARCH. ORDINE ARCHITETTI SASSARI N. MATR. 288 ITTIRI (SS)

STUDIO ARCHITETTURA

COMMITTENTE

f.to

PROGETTO

Di ristrutturazione e cambio di destinazione d'uso di un fabbricato da civile abitazione a deposito di macchinari ed attrezzature edili sito ad Ittiri in via Amsicora

STATO ATTUALE

ELABORATI

piante, Prospetti
sezione

NR. TAVOLA	SCALA DISEGNI
1	1:100
TOT. GRAFICI	DATA

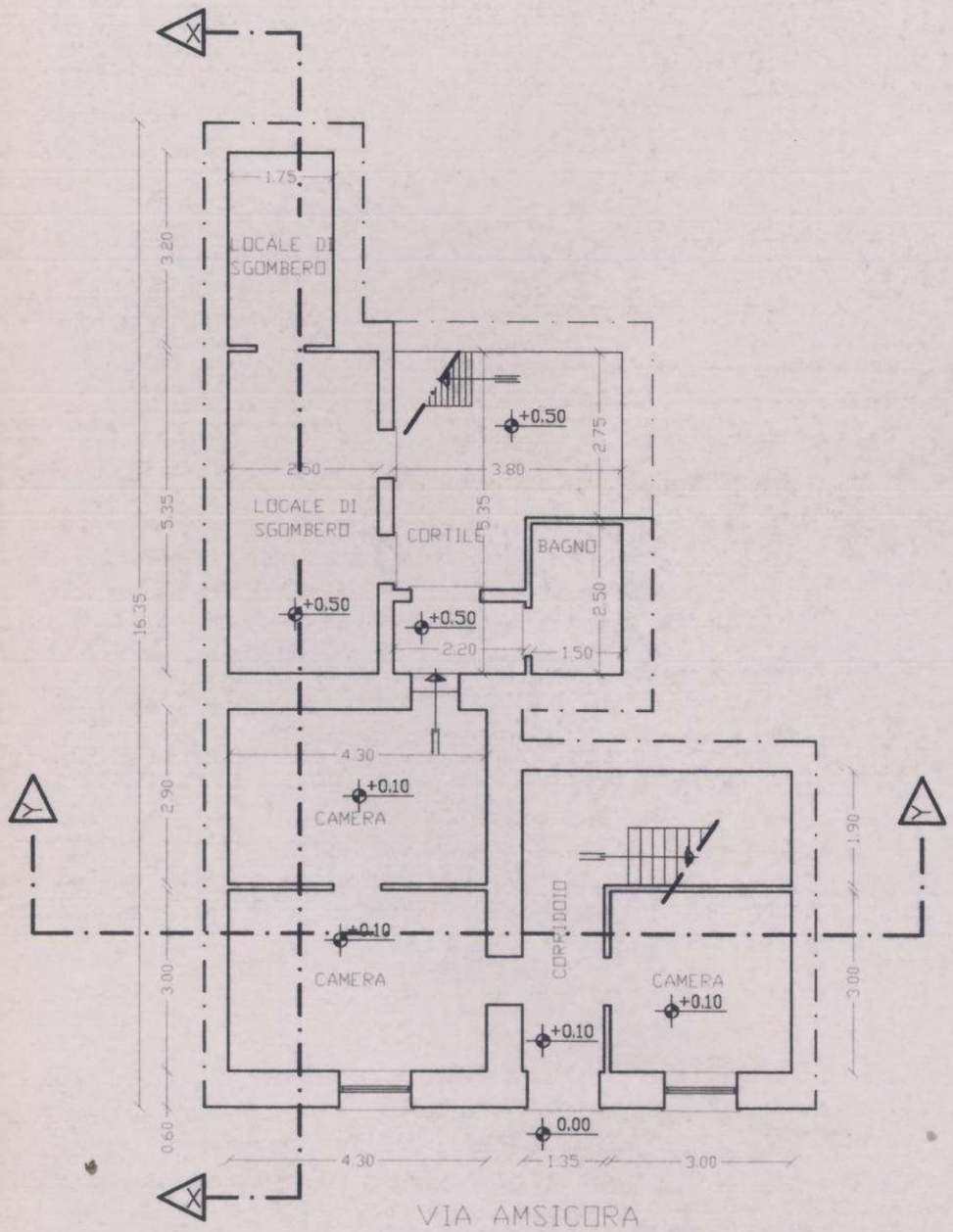

PIANTA PIANO TERRA

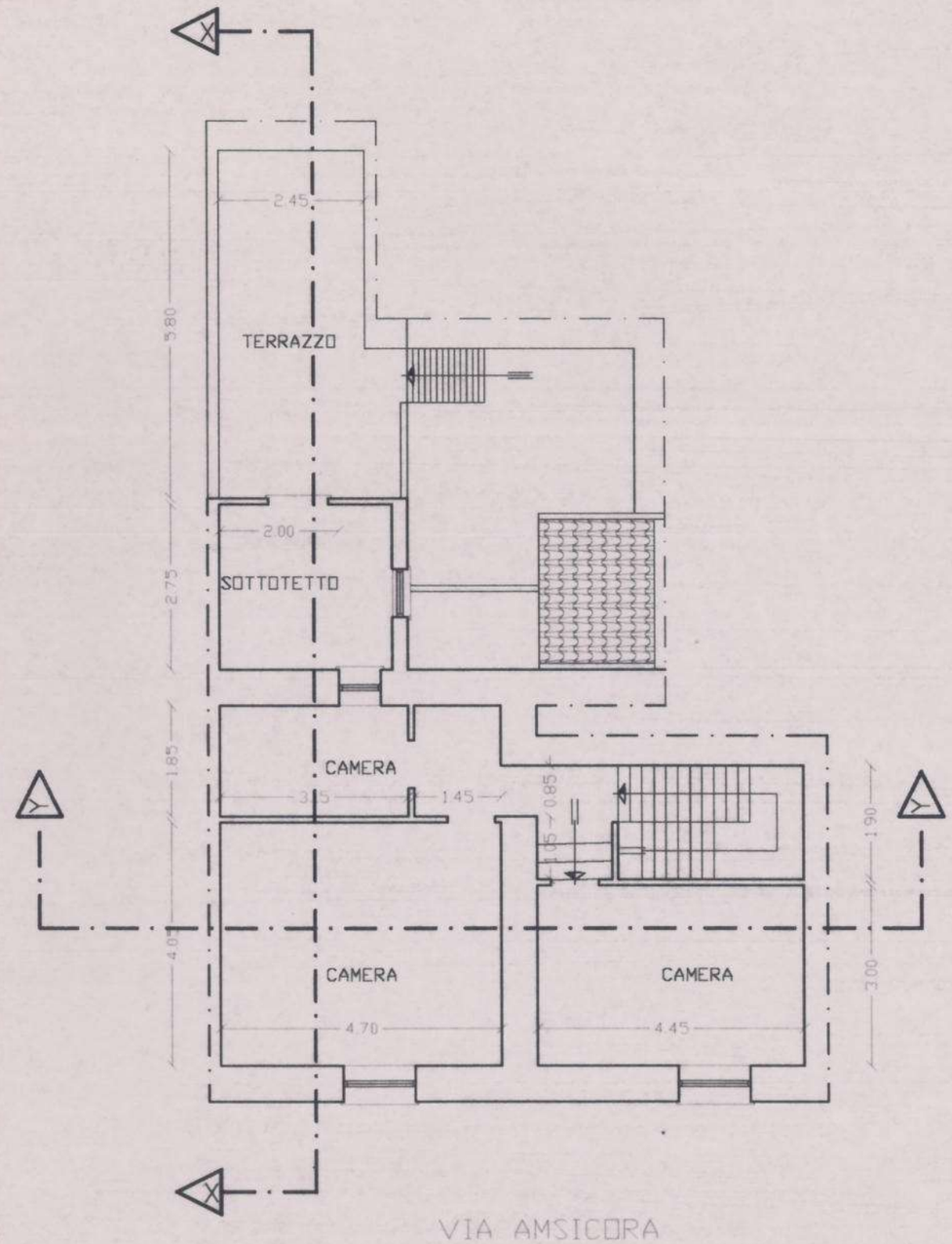

PIANTA PIANO PRIMO

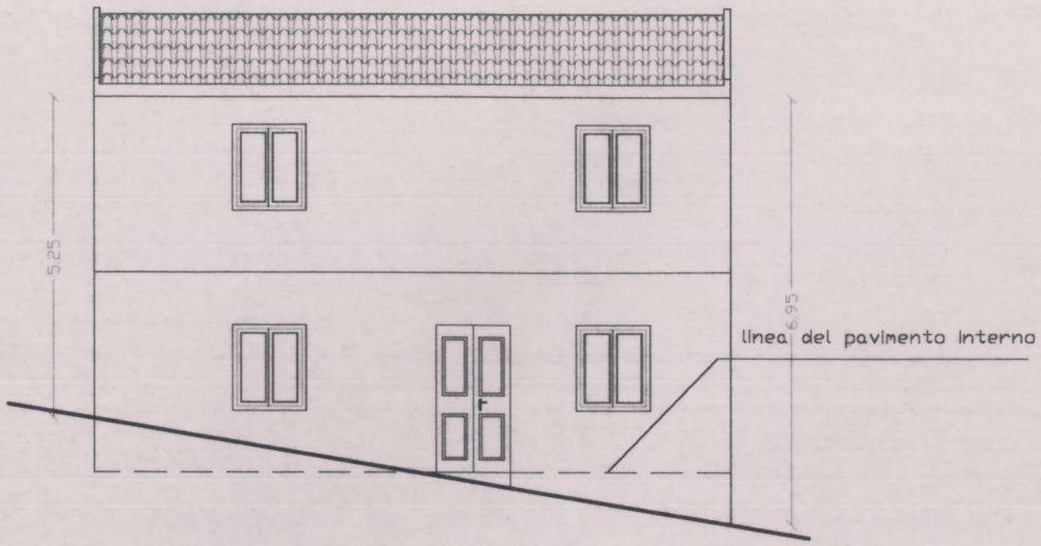

PROSPETTO SU VIA AMSICORA

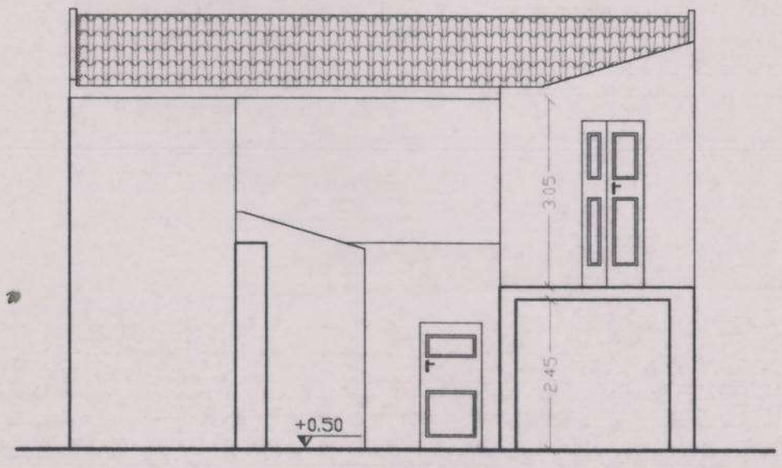

PROSPETTO POSTERIORE

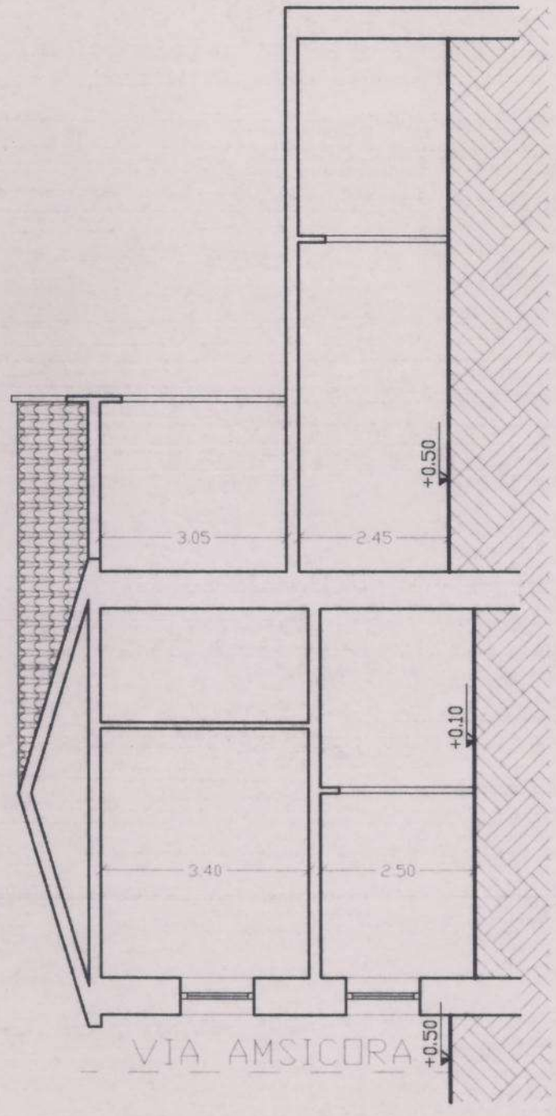

SEZIONE X-X

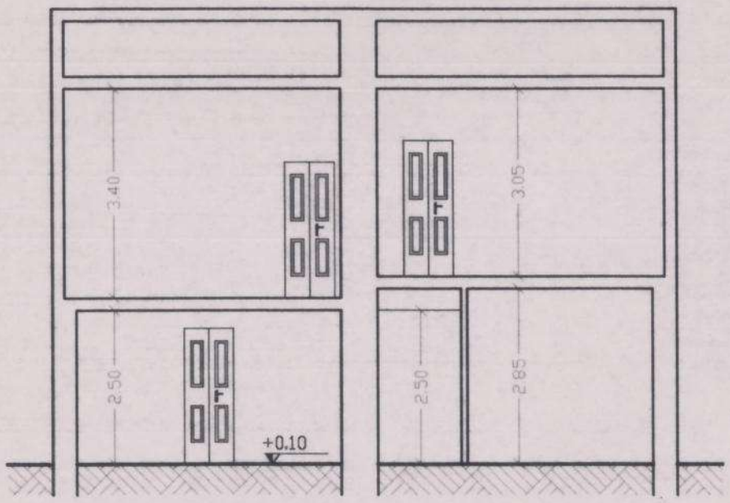

SEZIONE Y-Y

COMUNE DI ITTIRI

UFFICIO TECNICO

Progetto allegato alla richiesta N. 67/2000 del 23/2/2001

Esaminato dalla Commissione Edilizia nella seduta del 19/3/2001

verb. 4

NULLA OSTA

Con le condizioni imposte nella concessione edilizia

Ittiri, 21 MAG. 2001

COMUNE DI ITTIRI - UFFICIO TECNICO

IL TECNICO INCARICATO

(Geom. Pisanu G. Giacomo)

ARCHITETTI ORDINE ARCH. ITTIRI (SS) N. MATR. 296

STUDIO ARCHITETTURA

COMMITTENTE

f.to

PROGETTO

Di ristrutturazione e cambio di destinazione d'uso di un fabbricato di civile abitazione sito ad Ittiri in via Amsicora n°30

IN PROGETTO

ELABORATI

Piante, Prospetti
Sezione

NR. TAVOLA	SCALA DISEGNI
2	1:100
TOT. GRAFICI	DATA

STRALCIO P.R.G.

Comune di Ittiri

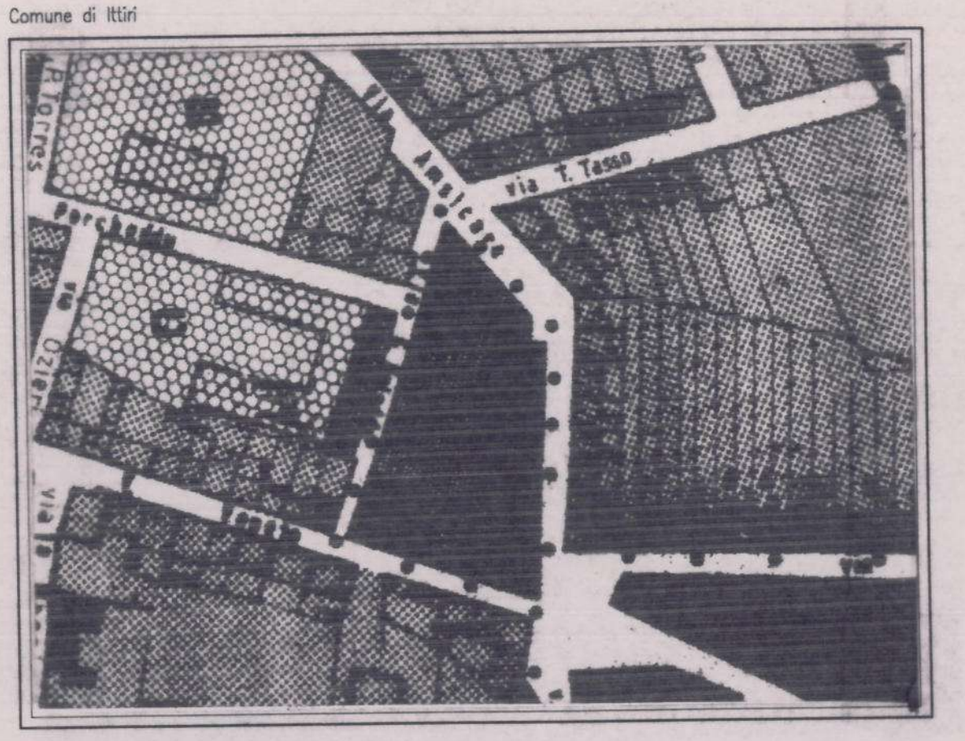

STRALCIO CATASTALE

Comune di Ittiri

Foglio 73 all. B mappale 772/1

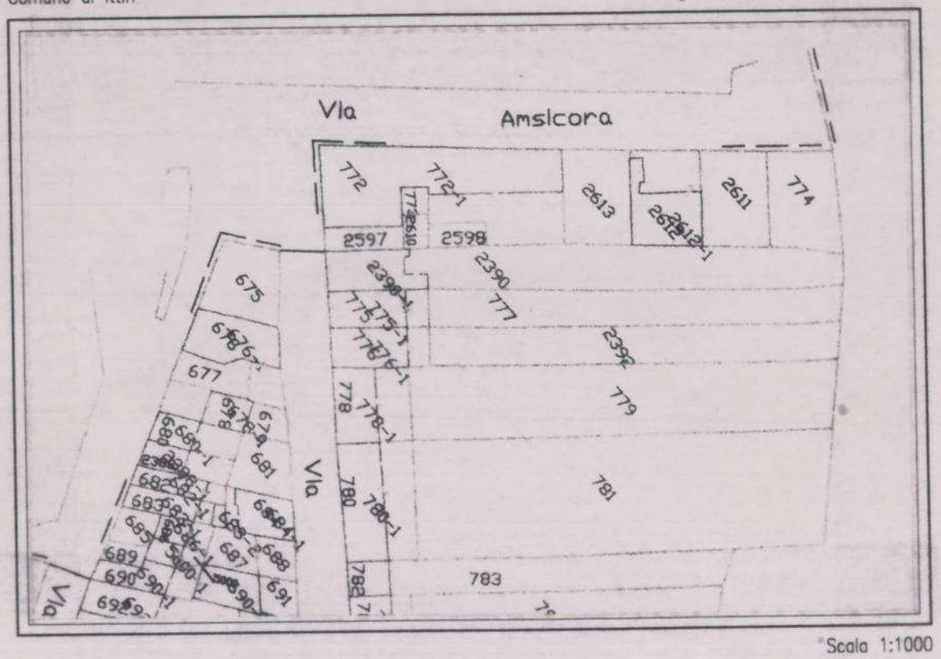

Scala 1:1000

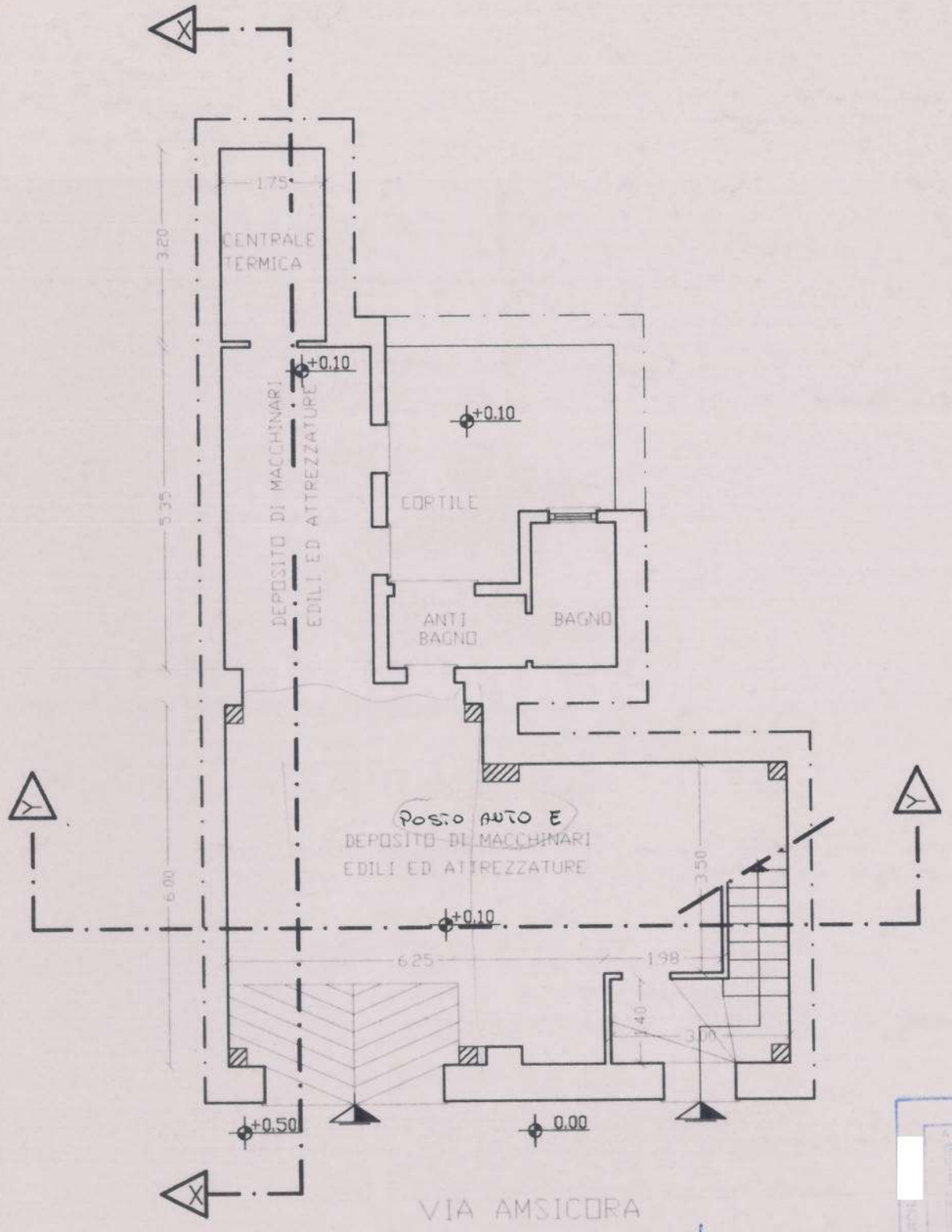

visto per correzione

ARCHITETTI ITTIRI (SS) SASSARI N. MATR. 268

PIANTA PIANO TERRA

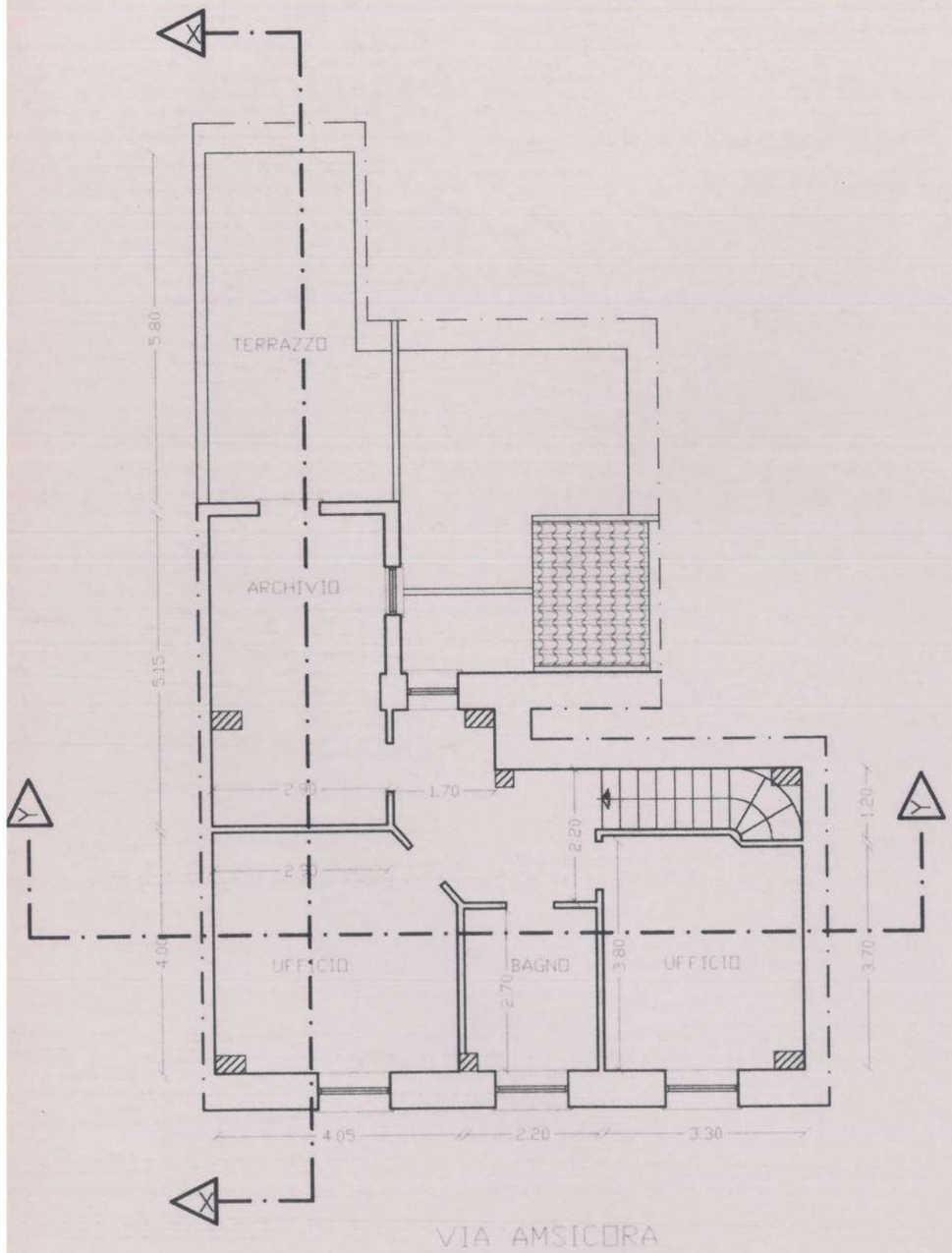

PIANTA PIANO PRIMO

PROSPETTO SU VIA AMSICORA

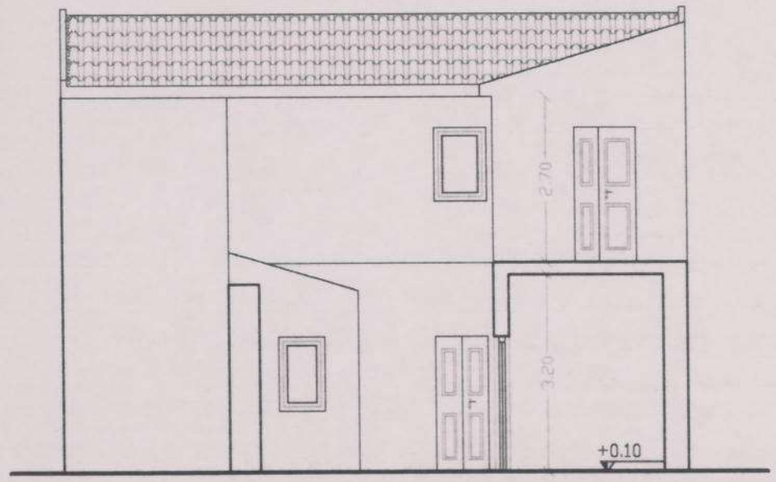

PROSPETTO POSTERIORE

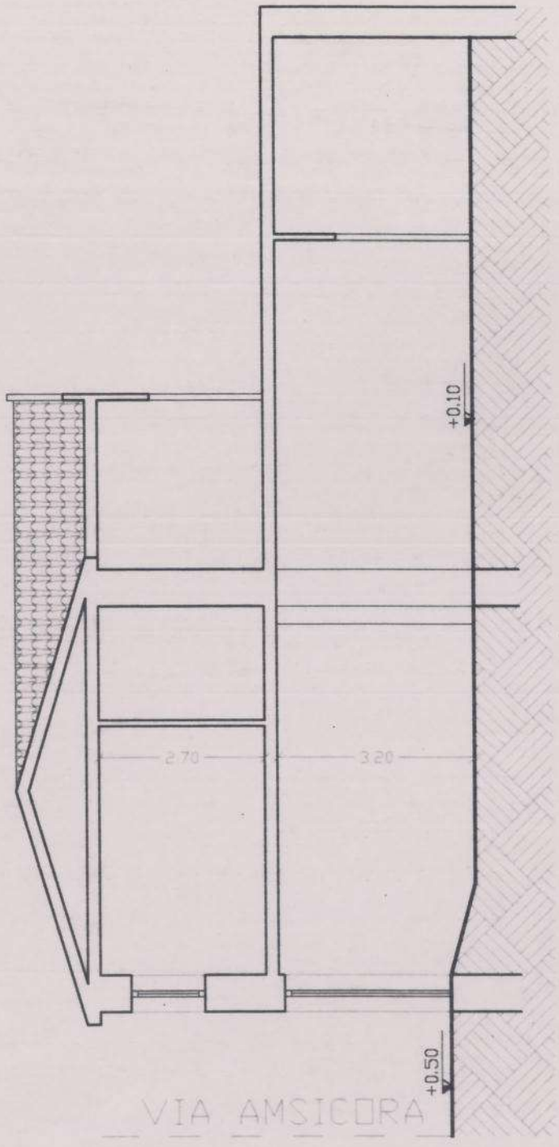

SEZIONE X-X

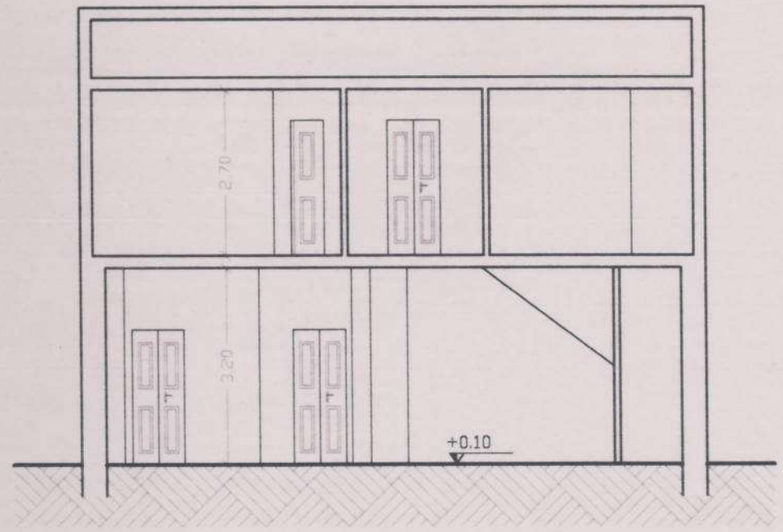

SEZIONE Y-Y

Comune di Ittiri
Provincia di Sassari

CERTIFICATO DI DESTINAZIONE URBANISTICA

Sulla base del tipo di interrogazione selezionata, nel presente documento sono indicate le informazioni riferite all'area richiesta.

Si evidenzia che il presente documento non ha valore legale, ma esclusivamente informativo.

La particella al foglio 0073 e mappale 00775

-- PUC --

Ricade parzialmente nella zona B1: Zone di completamento residenziale, disciplinate dagli artt. 20, 21, 22 e 23 delle N.T.A. Del P.U.C. (98%)

Ricade parzialmente nella zona VIABILITA: ViabilitÃ comunale (2%)

-- PAI Hg --

Ricade interamente nella zona Hg0: Area studiata non soggetta a potenziali fenomeni franosi

-- PAI Rg --

Ricade interamente nella zona Rg0: Area a rischio geologico nullo, disciplinata dalle N.T.A. del P.A.I.

Ittiri, lì 29/11/2024

COMUNE DI ITTIRI

PROVINCIA DI SASSARI

Visto d'approvazione

VARIANTE IN CORSO D'OPERA NON SOSTANZIALE ALLA PRATICA CON RICEVUTA SUAP -23112022-1706.555865 PRESENTATA IN DATA 25/01/2023 PROT. 608 DEL 25/01/2023 RIGUARDANTE UN FABBRICATO UBICATO IN VIA AMSICORA N. 53

COMMITTENTI	PROGETTISTA
-	

TAVOLA N°	ELABORATI	SCALA
	(Planimetrie generali)	

DATA	ARCHIVIO

CATASTALE - FG 73/B - MAPPALE : 772

STRALCIO P.U.C. - NORD - COMPARTO N. 129

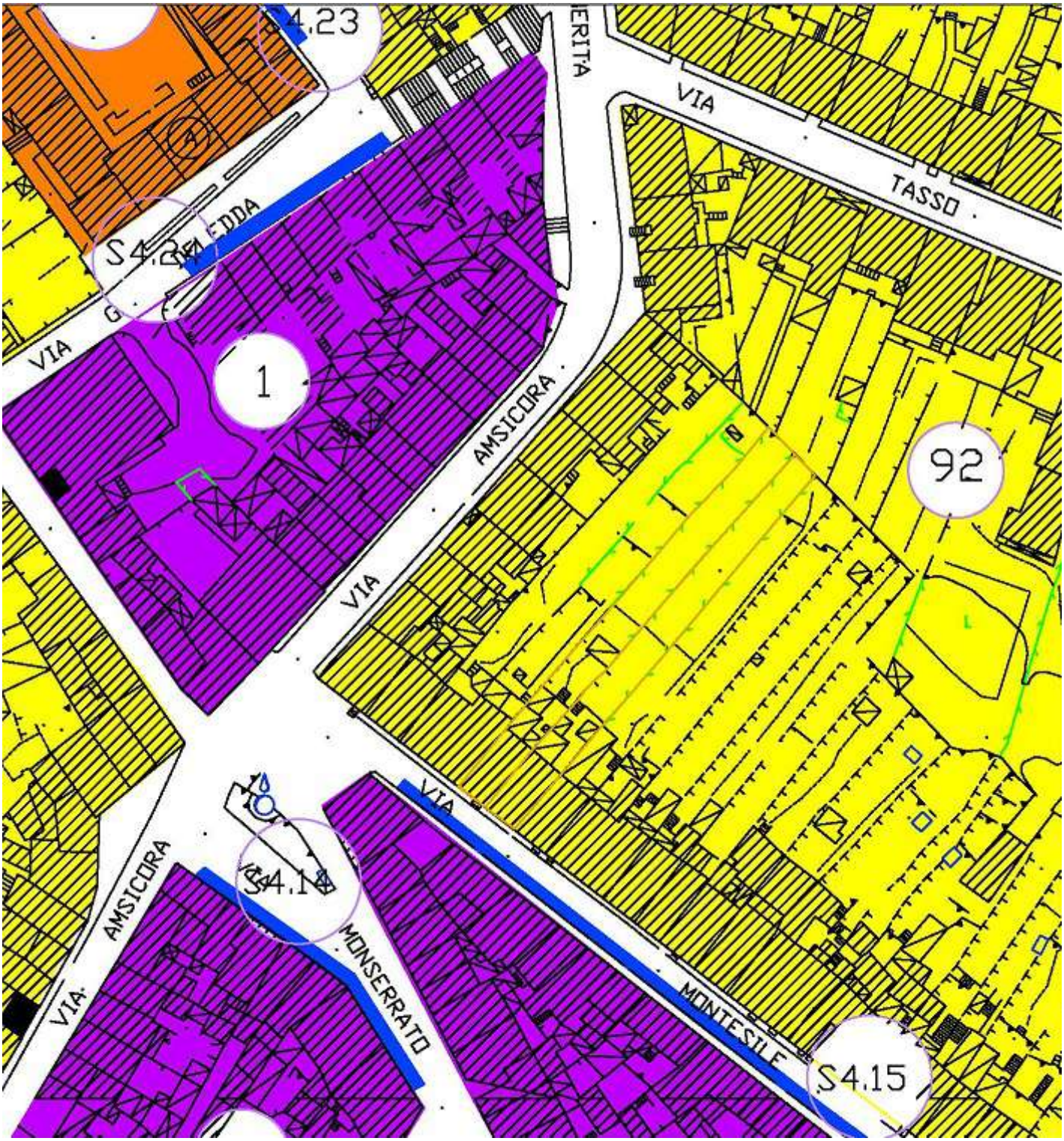

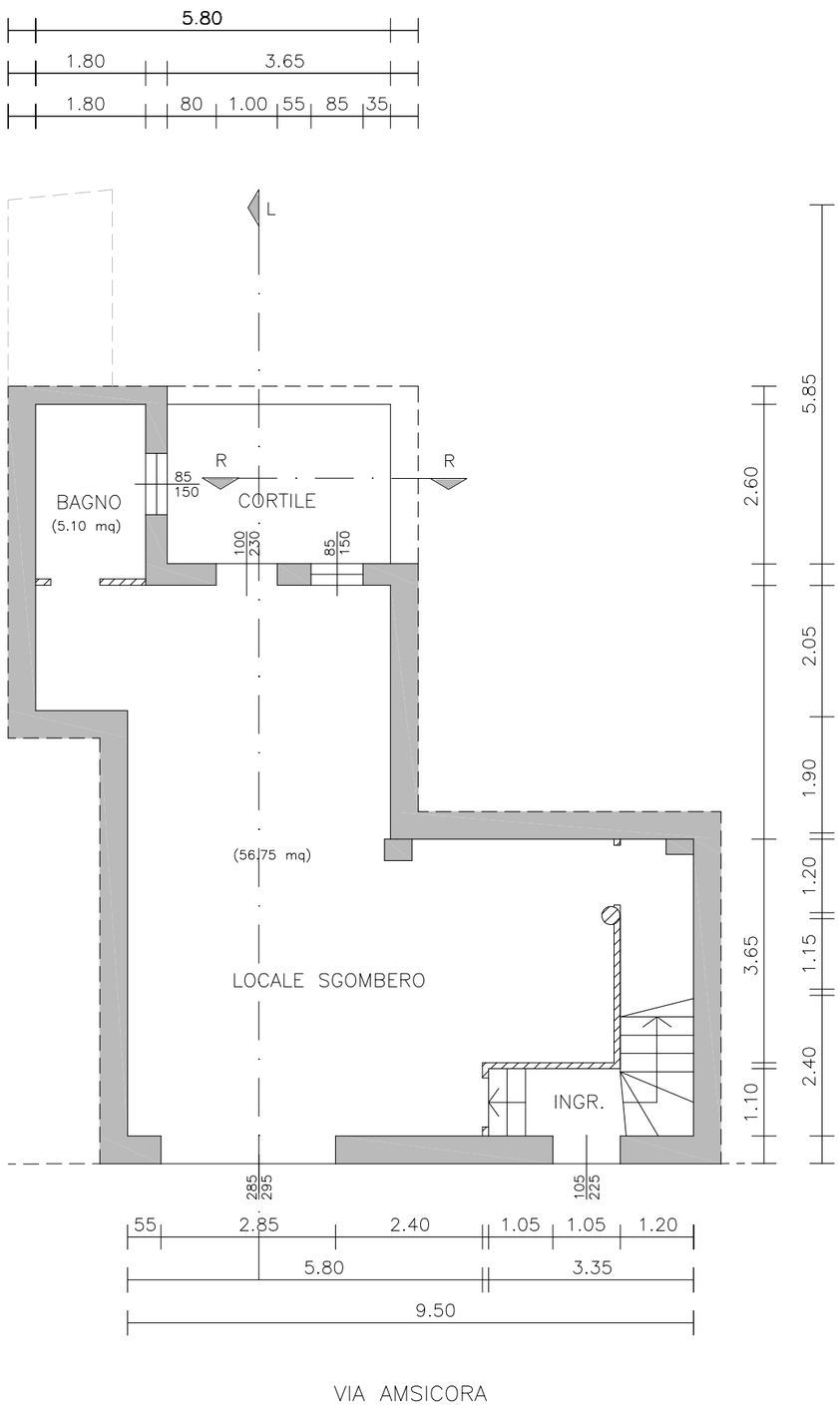

PIANO TERRA

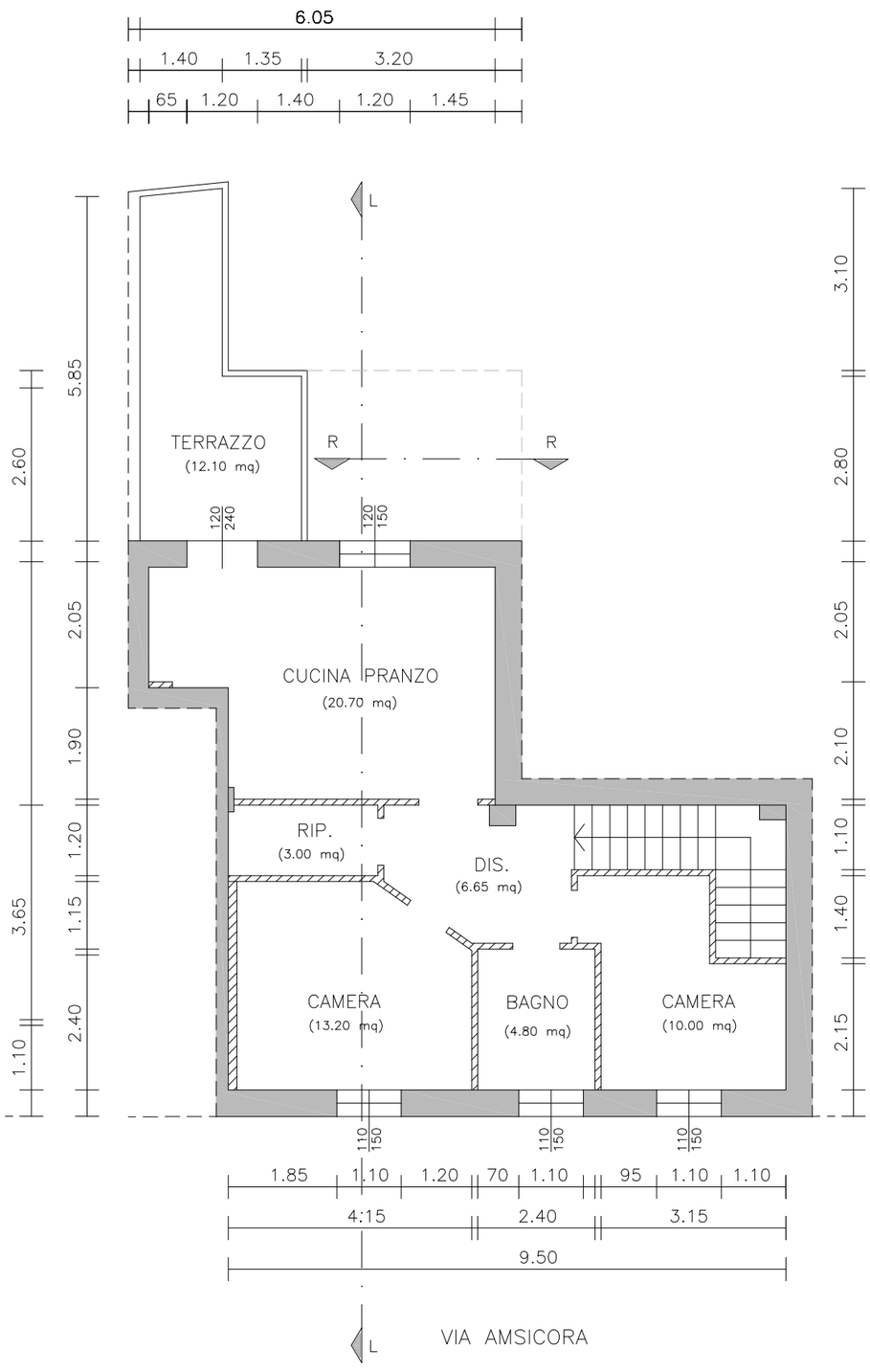

PIANO PRIMO

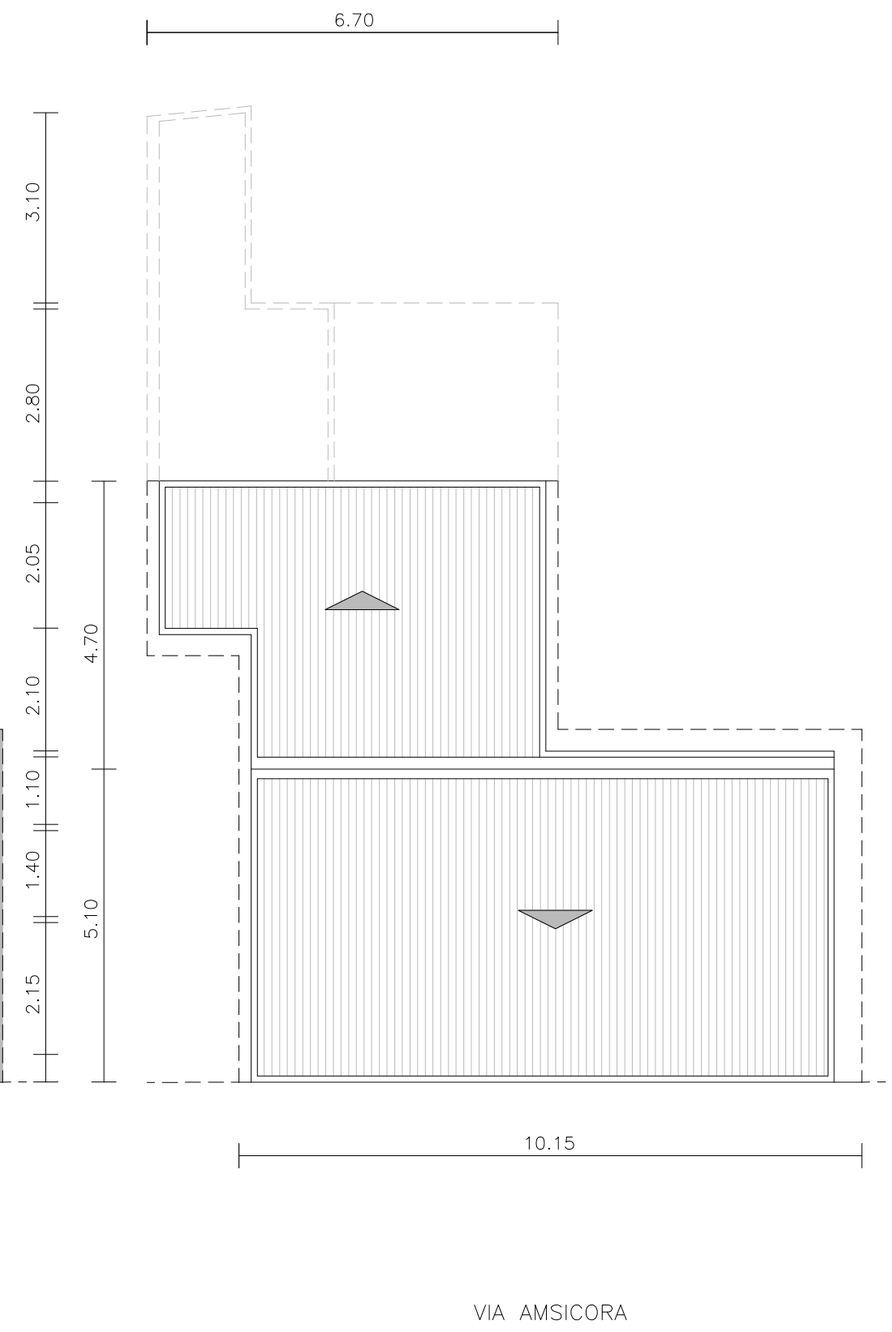

COPERTURA

COMUNE DI ITTIRI

PROVINCIA DI SASSARI

Visto d'approvazione

VARIANTE IN CORSO D'OPERA NON SOSTANZIALE ALLA PRATICA CON RICEVUTA SUAP N. – 23112022 – 1706.555865
PRESENTATA IN DATA 25/01/2023 PROT. 608 DEL 25/01/2023
RIGUARDANTE UN FABBRICATO UBICATO IN VIA AMSICORA N. 53

COMMITTENTI	PROGETTISTA
	Geom.

TAVOLA	ELABORATI IN VARIANTE	SCALA
2	(Piante . Prospetti . Sezioni)	1 : 100
DATA	ARCHIVIO	

PROSPETTO FRONTALE

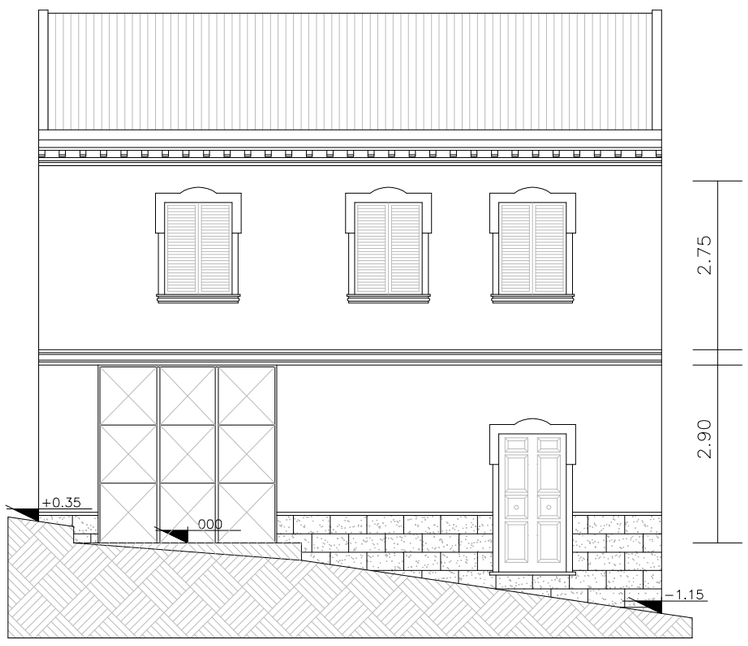

SEZIONE R–R

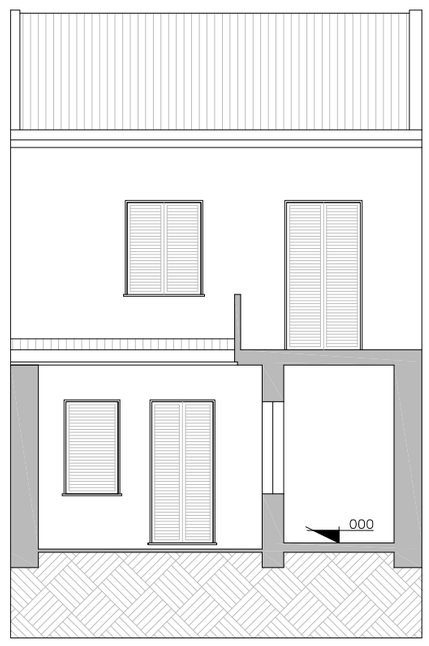
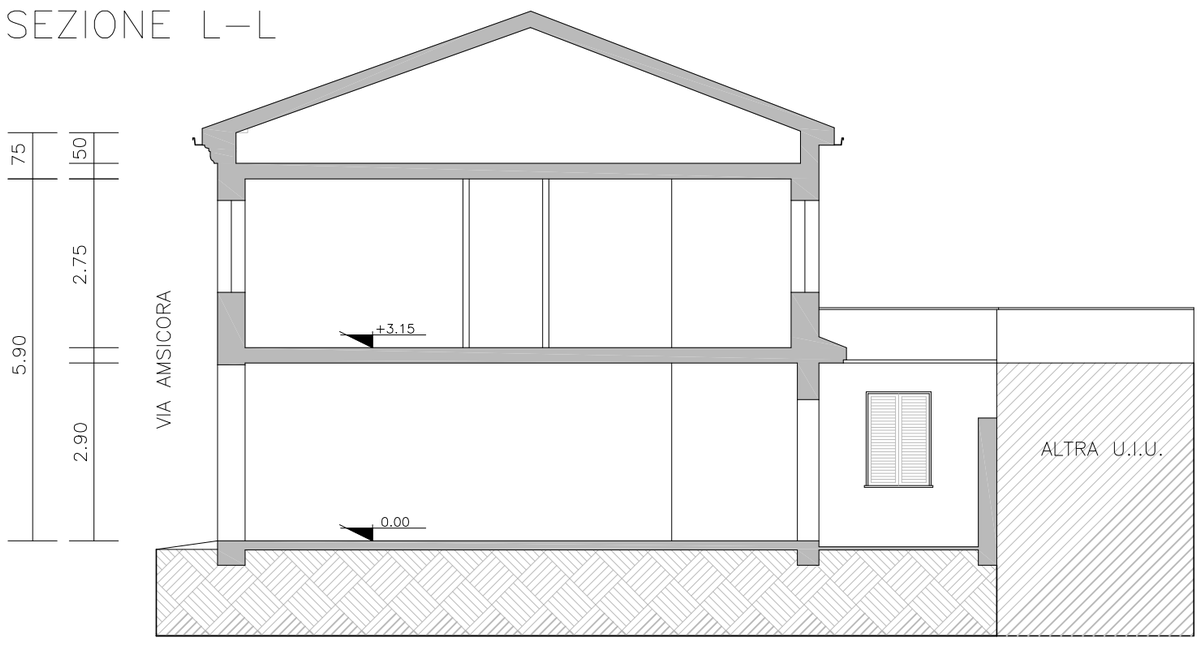
SEZIONE L–L