Tribunale di Sassari

SEZIONE EE.II.

Esecuzione Immobiliare 90/2023 del R.G.E.

G. E. Dott. Elisa Remonti

promossa da:

Che Banca! S.p.A.
Codice fiscale: 10536040966
Viale Bodio, 37 – Palazzo 4
Milano (MI)

- Avv.
- Avv.

contro:

,

RELAZIONE DEL C.T.U.
ex art. 568 C.P.C.

Ing. Alessandro A. Sanna

RELAZIONE E STIMA BENE

SOMMARIO

Incarico 1
Quesiti del giudice 1
Ulteriori domande 1
Premessa ed individuazione dei beni 1
Bene N°1 - Appartamento ubicato a Muros (SS) - Via Brigata Sassari, 6, piano 1S – T 1
Bene N°2 - Magazzino ubicato a Muros (SS) - Via Brigata Sassari, 6, piano 1S 1
Rif. unico per i due beni. 2
Lotto unico 2
Completezza documentazione ex art. 567 3
Rif. unico per i due beni. 3
Titolarità 3
Rif. unico per i due beni. 3
Confini 3
Rif. unico per i due beni. 3
Consistenza 3
Bene N°1 - Appartamento ubicato a Muros (SS) - Via Brigata Sassari, 6, piano 1S – T 3
Bene N°2 - Magazzino ubicato a Muros (SS) - Via Brigata Sassari, 6, piano 1S 4
Cronistoria Dati Catastali 4
Bene N°1 - Appartamento ubicato a Muros (SS) - Via Brigata Sassari, 6, piano 1S – T 4
Bene N°2 - Magazzino ubicato a Muros (SS) - Via Brigata Sassari, 6, piano 1S 5
Dati catastali 6
Bene N°1 - Appartamento ubicato a Muros (SS) - Via Brigata Sassari, 6, piano 1S – T 6
Bene N°2 - Magazzino ubicato a Muros (SS) - Via Brigata Sassari, 6, piano 1S 6
Rif. unico per i due beni. 6
Patti 9
Rif. unico per i due beni. 9
Stato conservativo 9
Rif. unico per i due beni. 9
Parti Comuni 10
Rif. unico per i due beni. 10
Servitù, censo, livello, usi civici 10
Rif. unico per i due beni. 10
Caratteristiche costruttive prevalenti 11
Rif. unico per i due beni. 11
Stato di occupazione 11
Rif. unico per i due beni. 11
Provenienze ventennali 12
Bene N°1 - Appartamento ubicato a Muros (SS) - Via Brigata Sassari, 6, piano 1S – T 12
Bene N°2 - Magazzino ubicato a Muros (SS) - Via Brigata Sassari, 6, piano 1S 13
Formalità pregiudizievoli 14
Rif. unico per i due beni. 14
Normativa urbanistica 15
Rif. unico per i due beni. 15
Regolarità edilizia 17
Rif. unico per i due beni. 17
Vincoli ed oneri condominiali 18
Rif. unico per i due beni. 18

Stima / formazione lotti 1
Descrizione del mercato immobiliare e formazione prezzo .....

Valori unitari di stima 19
Formazione lotti 20
Costi di ristrutturazione 21
Deprezzamenti 21
Risposta al quesito aggiuntivo del giudice 21
Firma e chiusura perizia 23

INDICE FIGURE

Figura 1 – Foto aerea 2
Figura 2 - Ricostruzione stato luoghi secondo dati catastali 7
Figura 3 - Ricostruzione stato luoghi da rilievo 8
Figura 4 - Vista interno piano superiore 9
Figura 5 - Vista interno piano inferiore 10
Figura 6 – PUC Muros 17
Figura 7 – Schema valori ambito locale Agenzia Entrate 19

INCARICO

All'udienza del 05/06/2024, il sottoscritto Ing. Sanna Alessandro Antonio, con studio in Via Bogino, 25 - 07100 - Sassari (SS), e-mail sandro.sanna@gmail.com, PEC alessandroantonio.sanna@ingpec.eu, Tel.393 9940320, veniva nominato Esperto ex art. 568 c.p.c. e in data 14/06/2024 accettava l'incarico e prestava giuramento di rito risposta su posta certificata.

QUESITI DEL GIUDICE

L'incarico iniziale assegnato dal giudice viene riportato integralmente nell'allegato 1.

ULTERIORI DOMANDE

Nell'udienza in data 27 marzo 2025, in seguito alle osservazioni dell'avvocato del creditore procedente, il Giudice chiedeva al CTU incaricato la verifica e correzione di alcuni errori e che inoltre precisasse "*...la natura dei vari deprezzamenti, distinguendo tra a) deprezzamenti funzionali alla messa a vendita del bene, inteso quali oneri di regolarizzazione e/o di agibilità del bene; da b) deprezzamenti funzionali al mero migliore utilizzo e godimento del bene...*".

PREMESSA ED INDIVIDUAZIONE DEI BENI

I beni oggetto di pignoramento sono costituiti dai seguenti immobili:

- **Bene Nº 1** - Appartamento ubicato a Muros (SS) - Via Brigata Sassari, 6, piano 1S - T
- **Bene Nº 2** - Magazzino ubicato a Muros (SS) - Via Brigata Sassari, 6, piano 1S

Nel seguito si farà riferimento ai due beni nel loro insieme dove i dati sono comuni ed ai due beni distintamente quando vi sia la necessità una descrizione di dettaglio.

Vengono quindi individuati:

BENE Nº1 - APPARTAMENTO UBICATO A MUROS (SS) - VIA BRIGATA SASSARI, 6, PIANO 1S – T

Appartamento fronte strada a due livelli più cortile sul retro costituito da un fabbricato abitativo composto da soggiorno, cucina, disimpegno, due camere e un bagno, nonché da un locale magazzino.

Le due unità immobiliari hanno rispettivamente ingressi uno dal cortile al quale si accede da una rampa di scale dalla via Mannu e l'altro dalla Via Brigata Sassari. Il locale abitazione con ingresso dal cortile in via Mannu è collegato con il piano inferiore a mezzo di una scala interna

BENE Nº2 - MAGAZZINO UBICATO A MUROS (SS) - VIA BRIGATA SASSARI, 6, PIANO 1S

Locale magazzino al piano terra di un appartamento fronte strada a due livelli più cortile sul retro. Le due unità immobiliari hanno rispettivamente ingressi uno dal cortile al quale si accede da una rampa di scale dalla via Mannu e l'altro dalla Via Brigata Sassari.

RIF. UNICO PER I DUE BENI.

La vendita dei beni non è soggetta IVA.

Per i beni in questione non è stato effettuato un accesso forzoso.

L'immobile non risulta realizzato in regime di edilizia residenziale pubblica convenzionata e agevolata e finanziata in tutto o in parte con risorse pubbliche, con vincoli ancora vigenti a carico del proprietario debitore.

LOTTO UNICO

Il lotto è formato dai seguenti beni:

- **Bene Nº 1** - Appartamento ubicato a Muros (SS) - Via Brigata Sassari, 6, piano 1S - T
- **Bene Nº 2** - Magazzino ubicato a Muros (SS) - Via Brigata Sassari, 6, piano 1S

FIGURA 1 – FOTO AEREA

COMPLETEZZA DOCUMENTAZIONE EX ART. 567

RIF. UNICO PER I DUE BENI.

Si attesta che la documentazione di cui all'art. 567 c.p.c., comma 2 risulta completa in virtù della presenza di relazione notarile redatta dal dott. Giulia Messina Vitrano, notaio in Corleone in data 24 luglio 2023 aggiornata alla data del 07 luglio 2023.

In occasione della presente relazione il sottoscritto tecnico ha effettuato autonomamente le proprie visure, aggiornate alla data del 23/01/2025 per redigere l'elenco delle iscrizioni così come da quesito n. 8 dell'incarico.

TITOLARITÀ

RIF. UNICO PER I DUE BENI.

L'immobile oggetto dell'esecuzione appartiene all'esecutato:

- (Proprietà 1/1)
  Codice fiscale:

L'immobile viene posto in vendita per i seguenti diritti:

- (Proprietà 1/1)

CONFINI

RIF. UNICO PER I DUE BENI.

Confina con via Brigata Sassari, con proprietà , con via Mannu, con proprietà eredi

CONSISTENZA

BENE N°1 - APPARTAMENTO UBICATO A MUROS (SS) - VIA BRIGATA SASSARI, 6, PIANO 1S – T

Destinazione	Superficie Netta	Superficie Lorda	Coefficiente	Superficie Convenzionale	Altezza	Piano
Abitazione	35,80 mq	42,33 mq	1	42,33 mq	2,70 m	1S
Abitazione	93,94 mq	113,00 mq	1	113,00 mq	2,80 m	T
Cortile	98,00 mq	98,00 mq	0,2	19,60 mq	0,00 m	
			Totale superficie convenzionale:	**174,93 mq**		
			Incidenza condominiale:	**0,00**	**%**	
			Superficie convenzionale complessiva:	**174,93 mq**		

Bene Nº2 - Magazzino ubicato a Muros (SS) - Via Brigata Sassari, 6, piano 1S

Destinazione	Superficie Netta	Superficie Lorda	Coefficiente	Superficie Convenzionale	Altezza	Piano
Magazzino	25,40 mq	30,30 mq	0,25	7,57 mq	2,50 m	
			Totale superficie convenzionale:	**7,57 mq**		
			Incidenza condominiale:	**0,00**	**%**	
			Superficie convenzionale complessiva:	**7,57 mq**		

CRONISTORIA DATI CATASTALI

Bene Nº1 - Appartamento ubicato a Muros (SS) - Via Brigata Sassari, 6, piano 1S – T

Periodo	Proprietà	Dati catastali
Dal **28/05/1987** al **01/01/1992**	1. 1/5 2. 1/5 3. 1/5 4. 1/5 5. 1/5	Catasto **Fabbricati** Fg. 12, Part. 229, Sub. 1 Categoria A6 Cl.1, Cons. 3,5 vani Rendita Lire 388 Piano T - 1
Dal **01/01/1992** al **26/07/2002**	1. 1/5 2. 1/5 3. 1/5 4. 1/5 5. 1/5	Catasto **Fabbricati** Fg. 12, Part. 229, Sub. 1 Categoria A6 Cl.1, Cons. 3,5 vani Rendita Lire 203.000 Piano T - 1
Dal **26/07/2002** al **29/11/2002**	1. 2/5 2. 1/5 3. 1/5 4. 1/5	Catasto **Fabbricati** Fg. 12, Part. 229, Sub. 1 Categoria A6 Cl.1, Cons. 3,5 vani Rendita Lire 203.000 Piano T - 1
Dal **29/11/2002** al **31/08/2006**	1. 2/5 2. 1/5 3. 1/5 4. 1/5	Catasto **Fabbricati** Fg. 12, Part. 229, Sub. 1 Categoria A3 Cl.1, Cons. 7 vani Rendita € 339,83 Piano S1 - T
Dal **31/08/2006** al **09/11/2015**	1.	Catasto **Fabbricati** Fg. 12, Part. 229, Sub. 1 Categoria A3 Cl.1, Cons. 7 vani Rendita € 339,83 Piano S1 - T

Dal **09/11/2015**	1.	Catasto **Fabbricati** Fg. 12, Part. 229, Sub. 1 Categoria A3 Cl.1, Cons. 7 vani Rendita € 339,83 Piano S1 – T superficie: Tot.: 192 mq escluse aree scoperte 182 mq

Bene N°2 - Magazzino ubicato a Muros (SS) - Via Brigata Sassari, 6, piano 1S

Periodo	Proprietà	Dati catastali
Dal al **30/06/1987 al 23/12/1991**	1.	Catasto Fabbricati Foglio 12 Particella 229 Subalterno 2 Rendita: Lire 222 Categoria A/6, Classe 1 Consistenza 2,0 vani
Dal **23/12/1991** al **01/01/1992**	1. 1/1 nuda proprietà 2. 1/1 usufrutto	Catasto Fabbricati Foglio 12 Particella 229 Subalterno 2 Rendita: Lire 222 Categoria A/6, Classe 1 Consistenza 2,0 vani
Dal **01/01/1992** al **19/03/1998**	1. 1/1 nuda proprietà 2. 1/1 usufrutto	Catasto Fabbricati Foglio 12 Particella 229 Subalterno 2 Rendita: Lire 116.000 Categoria A/6, Classe 1 Consistenza 2,0 vani
Dal **19/03/1998 al 08/01/2004**	1. 1/1 nuda proprietà 2. 1/1 usufrutto	Catasto Fabbricati Foglio 12 Particella 229 Subalterno 2 Rendita: Lire 116.000 Categoria A/6, Classe 1 Consistenza 2,0 vani
Dal **08/01/2004 al 30/06/2006**	1. 1/1 nuda proprietà 2. 1/1 usufrutto	Catasto Fabbricati Foglio 12 Particella 229 Subalterno 2 Rendita: € 59,91 Categoria A/6, Classe 1 Consistenza 2,0 vani
Dal **30/06/2006 al 31/08/2006**[1]	1. 1/1 nuda proprietà 2. 1/1 usufrutto	Catasto Fabbricati Foglio 12 Particella 229 Subalterno 3 Rendita: € 92,96 Categoria C/2, Classe U Consistenza 25 mq
Dal **31/08/2006 al 09/11/2015**	1.	Catasto Fabbricati Foglio 12 Particella 229 Subalterno 3 Rendita: € 92,96 Categoria C/2, Classe U Consistenza 25 mq
Dal **09/11/2015**	1.	Catasto Fabbricati Foglio 12 Particella 229 Subalterno 3 Rendita: € 92,96 Categoria C/2, Classe U Consistenza 36 mq

[1] Dalla data del 30/06/2006 il sub. 2 diventa sub. 3

DATI CATASTALI

BENE Nº1 - APPARTAMENTO UBICATO A MUROS (SS) - VIA BRIGATA SASSARI, 6, PIANO 1S – T

Catasto fabbricati (CF)											
Dati identificativi				Dati di classamento							
Sezione	Foglio	Part.	Sub.	Zona Cens.	Categoria	Classe	Consistenza	Superficie catastale	Rendita	Piano	Graffato
	12	229	1		A3	1	7 vani	192 mq	339,83 €	S1 - T	

BENE Nº2 - MAGAZZINO UBICATO A MUROS (SS) - VIA BRIGATA SASSARI, 6, PIANO 1S

Catasto fabbricati (CF)											
Dati identificativi				Dati di classamento							
Sezione	Foglio	Part.	Sub.	Zona Cens.	Categoria	Classe	Consistenza	Superficie catastale	Rendita	Piano	Graffato
	12	229	3		C/2	U	25 mq	36 mq	92,96 €	T	

RIF. UNICO PER I DUE BENI.

Corrispondenza catastale

Non sussiste corrispondenza catastale.

Come già relazionato esistono delle difformità dovute ai lavori di trasformazione del bene.

Non essendo tali lavori peraltro autorizzati si ritiene necessario riportare il bene alla condizione originaria per poter essere regolarizzato. Sarebbe possibile predisporre una variazione della planimetria catastale per renderla conforme allo stato dei luoghi, ma questa dovrebbe avvenire in seguito ad una pratica autorizzativa o ad una "mancata SCIA" e quindi successivamente alla verifica e regolarizzazione urbanistica del bene.

C'è da evidenziare inoltre una discrepanza tra i numeri civici registrati come "via Brigata Sassari n°22 piano T" per i sub 3 e "via Brigata Sassarin°6 piano S1-T" per il sub 1 pur insistendo nello stesso stabile ed essendo il sub 3 al piano inferiore rispetto al sub.1.

Da notare che nel certificato storico catastale si hanno due cognomi diversi per la stessa persona (e Si tratta di un evidente lapsus calamai in quanto hanno lo stesso codice fiscale.

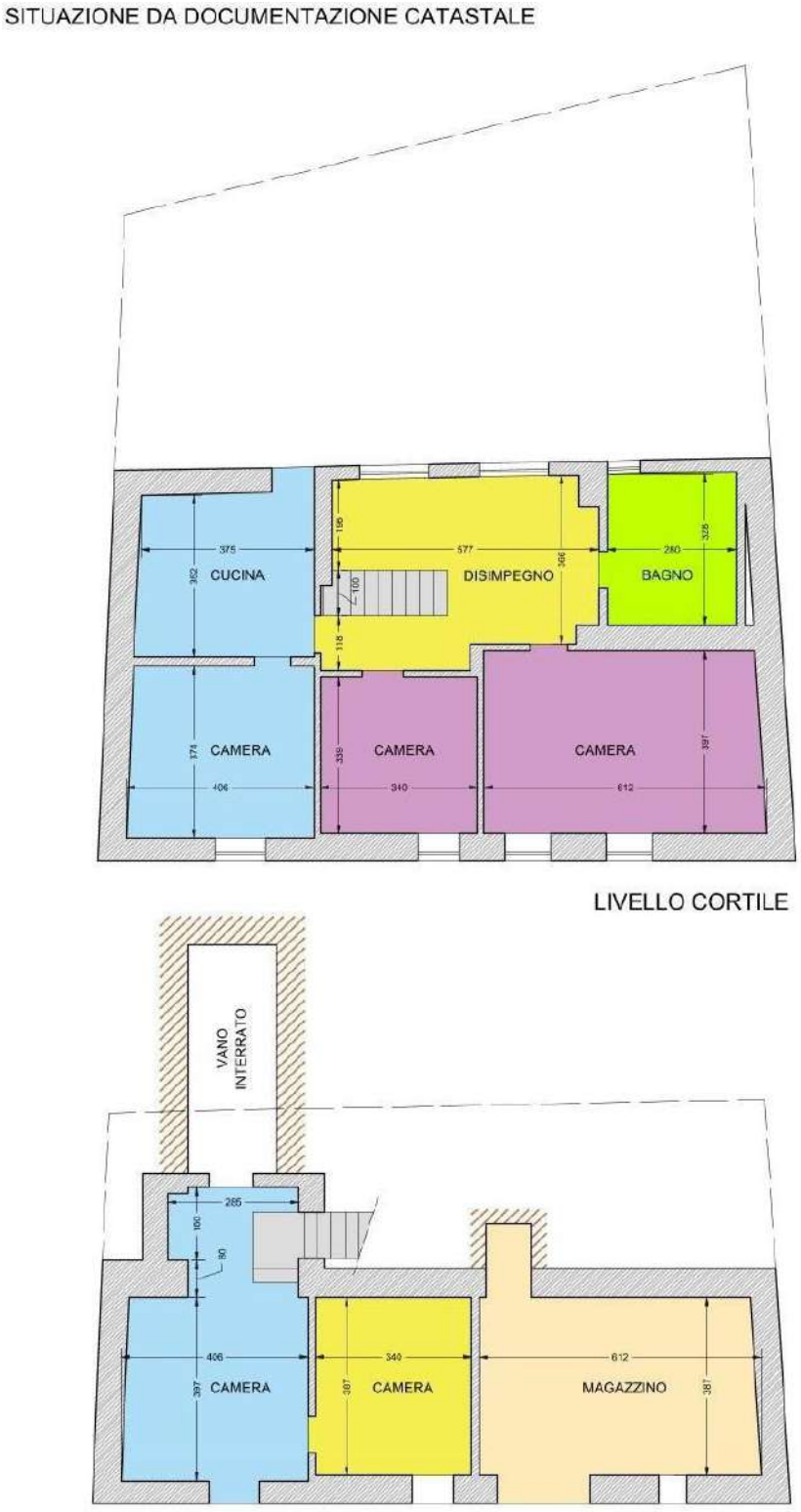

FIGURA 2 - RICOSTRUZIONE STATO LUOGHI SECONDO DATI CATASTALI

STATO DEI LUOGHI RILEVATO (con lavori di trasformazione non completati)

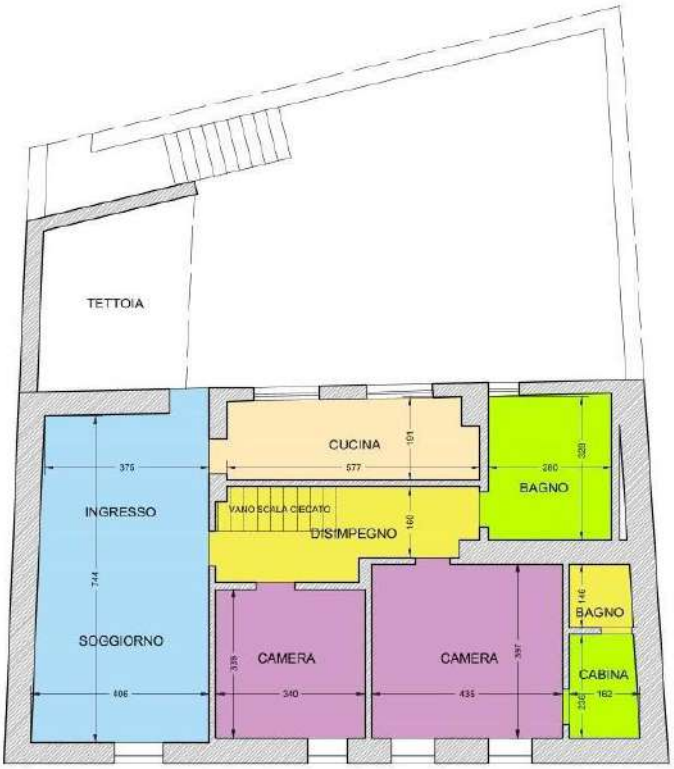

LIVELLO CORTILE

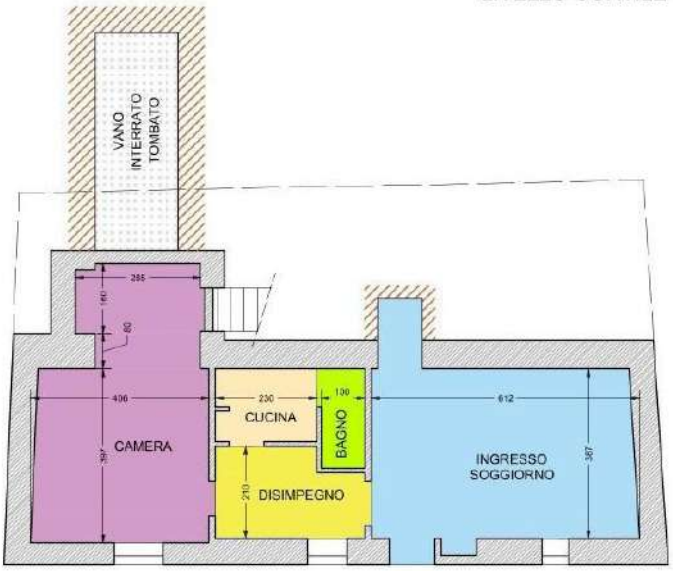

LIVELLO STRADA

FIGURA 3 - RICOSTRUZIONE STATO LUOGHI DA RILIEVO

PATTI

RIF. UNICO PER I DUE BENI.

L'immobile non risulta attualmente occupato dal proprietario esecutato né risultano contratti di locazione in essere a favore di terzi

STATO CONSERVATIVO

RIF. UNICO PER I DUE BENI.

L'immobile risulta alla data del sopralluogo disabitato ed in stato di semi-abbandono e risultano scollegate tutte le utenze. Al momento non risulta possibile un suo utilizza se non dopo un importante intervento di ripristino.

Il sopralluogo evidenzia una situazione in cui il bene è sottoposto ad un intervento di trasformazione interrotto in fase di esecuzione.

Di fatto, da quanto è stato possibile capire lo scopo dell'intervento sarebbe stato quello di dividere il bene in due distinte unità immobiliari una al livello del piano cortile ed una al livello strada con la chiusura del solaio sul vano scala.

Nella realizzazione dell'unità al piano strada si ipotizzava anche l'annessione del magazzino individuato al subalterno 3, e quindi l'apertura di una porta tra le due unità immobiliari. Per fare ciò inoltre è stato variato il prospetto chiudendo in parte l'accesso al magazzino per realizzare la porta di ingresso e trasformata una porta di ingresso dalla strada in finestra.

FIGURA 4 - VISTA INTERNO PIANO SUPERIORE

Di tali interventi non si riscontra traccia di alcuna pratica autorizzativa presso l'ufficio tecnico del comune di Muros come da allegata nota dell'ufficio tecnico.

Stante tale situazione il bene versa in condizioni generali di cattiva manutenzione sia per lo stato incompiuto sia per il fatto che risulta non abitato e non manutenuto da molto tempo.

Le pareti interne al piano inferiore sono ancora con intonaco al grezzo e da tinteggiare. Al piano superiore sono tinteggiate ma con evidenti segni di rattoppi sia in parete sia in soffitto e manifestano distacchi di intonaco e in alcuni punti tinteggiatura ormai fatiscente.

I pavimenti sono di bassa qualità, al piano inferiore sono in piastrelle tipo "cotto" mentre al piano superiore sono in parquet prefinito.

Non esiste impianto di riscaldamento.

L'impianto elettrico al piano superiore non risulta funzionante, al piano inferiore invece è presente ma in stato di completamento con le sole canalizzazioni ed i fili ma realizzato come da ipotesi di variante.

L'impianto idrico è esistente e lo scarico è collegato alla fognatura comunale al piano inferiore è solo predisposto per quanto riguarda la cucina mentre sono presenti i pezzi del bagno.

Gli infissi interni al piano inferiore sono inesistenti, al piano superiore sono di scarsa qualità.

FIGURA 5 - VISTA INTERNO PIANO INFERIORE

Gli infissi esterni al piano inferiore, a parte quello per la nuova porta sono in pessimo stato di manutenzione. Al piano superiore risultano anche in parte diroccati.

Il cortile non è agibile in quanto infestato da vegetazione che sembrerebbe essere così da svariati anni. Esiste una tettoia di realizzazione più recente anche questa non presente in alcun documento autorizzativo né visibile dalle foto aeree.

Nell'insieme il bene si presenta in pessimo stato generale.[2]

PARTI COMUNI

RIF. UNICO PER I DUE BENI.

Il bene non risulta inserito in contesto condominiale.

Sono in comune con i confinanti i muri perimetrali dell'abitazione del cortile.

SERVITÙ, CENSO, LIVELLO, USI CIVICI

RIF. UNICO PER I DUE BENI.

Non risultano servitù gravanti sul bene

[2] La documentazione fotografica completa è riportata nell'allegato C4

CARATTERISTICHE COSTRUTTIVE PREVALENTI

RIF. UNICO PER I DUE BENI.

Il bene ha le tipiche caratteristiche della edilizia economica degli anni '50 e, come già evidenziato, denuncia una evidente carenza di manutenzione:

- La tipologia costruttiva è quella di muratura portante con solaio in laterocemento.
- Fondazioni: presumibilmente di tipo continuo realizzate in calcestruzzo armato;
- Strutture verticali: in muratura di blocchi in calcare
- Facciata: intonaco civile e tinteggiatura, stato di manutenzione scarso;
- Solai: in latero-cemento;
- Copertura: il tetto del fabbricato è realizzato con due falde laterali in tegole ed una parte centrale semplicemente impermeabilizzata
- Pareti interne: molto degradate in parte con intonaco da riprendere al piano superiore e da tinteggiare al piano inferiore.
- Pavimenti in parte realizzati in piastrelle al piano inferiore
- Pavimenti in parquet prefinito al piano superiore
- Infissi esterni: legno
- Persiane: legno molto degradati
- Infissi interni: porte a battente in legno tamburato;
- Impianto elettrico e idrico: presenti al piano superiore e solo predisposto al piano inferiore, privo di certificazione di conformità. Stato pessimo.
- Impianto termico assente
- Acqua calda sanitaria da boiler elettrico.
- La facciata sulla via Brigata Sassari è da riprendere e ristrutturare.

STATO DI OCCUPAZIONE

RIF. UNICO PER I DUE BENI.

Il bene è occupato dall'esecutato Sig. che ne ha l'esclusiva disponibilità ma non lo abita per via dello stato di semiabbandono in cui versa il bene e dei lavori in corso.

PROVENIENZE VENTENNALI

BENE Nº1 - APPARTAMENTO UBICATO A MUROS (SS) - VIA BRIGATA SASSARI, 6, PIANO 1S – T

Periodo	Proprietà	Atti			
Dal **28/05/1987** al **26/07/2002**		**DENUNZIA (NEI PASSAGGI PER CAUSA DI MORTE)**			
		Rogante	**Data**	**Repertorio Nº**	**Raccolta Nº**
			28/05/1987		
		Trascrizione			
		Presso	**Data**	**Reg. gen.**	**Reg. part.**
		U.R. Sassari	20/12/2002	162	44
		Registrazione			
		Presso	**Data**	**Reg. Nº**	**Vol. Nº**
		U.R. Sassari	20/12/2002	44	162
Dal **27/07/2002** al **31/08/2006**		**TESTAMENTO OLOGRAFO**			
		Rogante	**Data**	**Repertorio Nº**	**Raccolta Nº**
		SCANU SIMONE A.	26/07/2002	244278	
		Trascrizione			
		Presso	**Data**	**Reg. gen.**	**Reg. part.**
		Registrazione			
		Presso	**Data**	**Reg. Nº**	**Vol. Nº**
		AP Sassari	23/01/2003	80	1281

Dal **31/08/2006**		**Compravendita**			
		Rogante	**Data**	**Repertorio Nº**	**Raccolta Nº**
		MANIGA GIOVANNI	31/08/2006	247986/19842	
		Trascrizione			
		Presso	**Data**	**Reg. gen.**	**Reg. part.**
		UR Sassari	07/09/2006	15612	10130
		Registrazione			
		Presso	**Data**	**Reg. Nº**	**Vol. Nº**

Bene Nº2 - Magazzino ubicato a Muros (SS) - Via Brigata Sassari, 6, piano 1S

Periodo	Proprietà	Atti			
Dal **23/06/1992** al **31/08/2006**		**TESTAMENTO OLOGRAFO**			
		Rogante	**Data**	**Repertorio Nº**	**Raccolta Nº**
		Mario Faedda.	23/06/1992	33237	
		Trascrizione			
		Presso	**Data**	**Reg. gen.**	**Reg. part.**
		Registrazione			
		Presso	**Data**	**Reg. Nº**	**Vol. Nº**
		AP Sassari	31/03/1992	669	1281
Dal **31/08/2006**		**Compravendita**			
		Rogante	**Data**	**Repertorio Nº**	**Raccolta Nº**
		MANIGA GIOVANNI	31/08/2006	247986/19842	
		Trascrizione			

		Presso	**Data**	**Reg. gen.**	**Reg. part.**
		UR Sassari	07/09/2006	15613	10131
		Registrazione			
		Presso	**Data**	**Reg. Nº**	**Vol. Nº**

Per quanto riguarda l'immobile oggetto di pignoramento:

- Sussiste continuità nelle trascrizioni per il ventennio precedente alla data di trascrizione del pignoramento;
- La situazione della proprietà antecedente il ventennio della trascrizione del pignoramento risulta variata;
- La situazione della proprietà risulta attualmente invariata.

FORMALITÀ PREGIUDIZIEVOLI

RIF. UNICO PER I DUE BENI.

Dalle visure ipotecarie effettuate presso l'Agenzia del Territorio di Sassari aggiornate al 23/01/2025, sono risultate le seguenti formalità pregiudizievoli:

Iscrizioni

- **Ipoteca volontaria** derivante da Concessione a garanzia di mutuo
  Iscritto a Sassari il 07/09/2006
  Reg. gen. 15614 - Reg. part. 2846
  Quota: 1/1
  Importo: € 160.000,00
  A favore di UNICREDIT BANCA S.p.a.
  Contro
  Capitale: € 80.000,00

Note:
Estinzione totale dell'obbligazione in data 26/11/2007
Comunicazione di estinzione n.75 del 24/01/2008
Cancellazione totale in data 24/01/2008

- **Ipoteca volontaria** derivante da Concessione a garanzia di mutuo
  Iscritto a Sassari il 23/11/2007
  Reg. gen. 20515 - Reg. part. 3868
  Quota: 1/1
  Importo: € 165.000,00
  A favore di Micos Banca S.p.a.
  Contro
  Capitale: € 110.000,00

Trascrizioni

- **Verbale di pignoramento immobili**
  Trascritto a Sassari il 07/07/2023
  Reg. gen. 12241 - Reg. part. 9172
  Quota: 1/1
  A favore di CheBanca! S.p.a.
  Contro
  Formalità a carico della procedura

Oneri di cancellazione

L'onere di cancellazione a carico della procedura è l'imposta ipotecaria, stabilita dal Testo unico delle imposte ipotecarie e catastali, art. 13 della Tariffa, nella misura dello 0,50% dell'importo di iscrizione più la tassa ipotecaria di € 35,00 e l'imposta di bollo di € 59,00.

NORMATIVA URBANISTICA

RIF. UNICO PER I DUE BENI.

Il bene si trova all'interno della zona omogenea B1.1 / Sottozona B1.1 - zona di completamento disciplinata dall'art. 60 del P.U.C del comune di Muros.

Art. 60 - SOTTOZONA B1 (zona di completamento con tessuto edilizio compatto)

Questa sottozona è da considerarsi il primo sviluppo urbano fuori del centro storico ed è sottoposta parzialmente a P.P (D.A. nº 1985/U del 12.11.82, ormai decorso.

Gli interventi edificatori, in lotti già normati dal decorso P.P. (D.A. nº 1985/U/82) dovranno seguire le indicazioni del suddetto strumento attuativo, ai sensi dell'art. 17 della legge nº 1150/42.

Questa sottozona di completamento può essere oggetto di intervento edilizio diretto, nel rispetto delle seguenti prescrizioni:

a 0,80 mq/mq

- *Altezza massima: mt. 10,50*
- *I.f.f. : 3,00 mc/mq in assenza di P.P. oppure fino ad un massimo di 4 mc/mq in presenza di piano attuativo;*

- *Numero massimo dei piani: 3 fuori terra*
- *Distanza tra le pareti prospicienti di cui almeno una finestrata: mt. 8.*

Valgono le norme di cui all'art. 5 del D.A. 20.12.83

Distanza minima dai confini:

- *le costruzioni potranno sorgere sui confini di proprietà ovvero potranno distare minimo mt. 4.00.*

Distacco tra edifici:

- *la distanza minima tra due edifici non potrà essere inferiore a mt. 8,00, se con almeno una delle due pareti finestrate.*

Nelle zone inedificate esistenti o risultanti libere in seguito a demolizione, contenute in un tessuto urbano già definito o consolidato, che si estendono sul fronte stradale o in profondità per una lunghezza inferiore a mt. 20, nel caso di impossibilità di costruire in aderenza, qualora il rispetto delle distanze tra pareti finestrate comporti l'inutilizzazione dell'area o una soluzione tecnica inaccettabile, il Comune può consentire la riduzione delle distanze, nel rispetto delle disposizioni del Codice Civile.

La concessione di tale speciale ed eccezionale beneficio sarà valutata con particolare attenzione dalla C.E.

Al fine di migliorare le condizioni igieniche dei fabbricati esistenti, è consentita l'apertura di finestre nei vani privi di luci dirette a distanze inferiori a quelle sopraindicate, purché nel rispetto delle disposizioni fissate al riguardo dal Codice Civile.

Per quanto riguarda la distanza tra pareti non finestrate, valgono le norme del Codice Civile.

Sup. minima di parcheggio: ogni nuova costruzione dovrà essere dotata di posto macchina coperto o scoperto nella misura minima di 1 mq/10 mc. di costruzione.

Le autorimesse potranno essere anche interrate o seminterrate, compatibilmente con la soluzione architettonica accettabile dell'ingresso lato strada.

La disciplina dei cui al comma h) del presente articolo non si applica agli interventi di restauro, ristrutturazione e a quelli, in generale di recupero del patrimonio edilizio residenziale esistente, per i fabbricati realizzati antecedentemente l'entrata in vigore della legge nº 765/'67.

Per edifici con altre destinazioni, si veda il precedente art. 34 delle presenti N.T.A.

Piantumazione a verde: tutte le aree scoperte dovranno essere tenute a verde privato per almeno il 50% della relativa superficie.

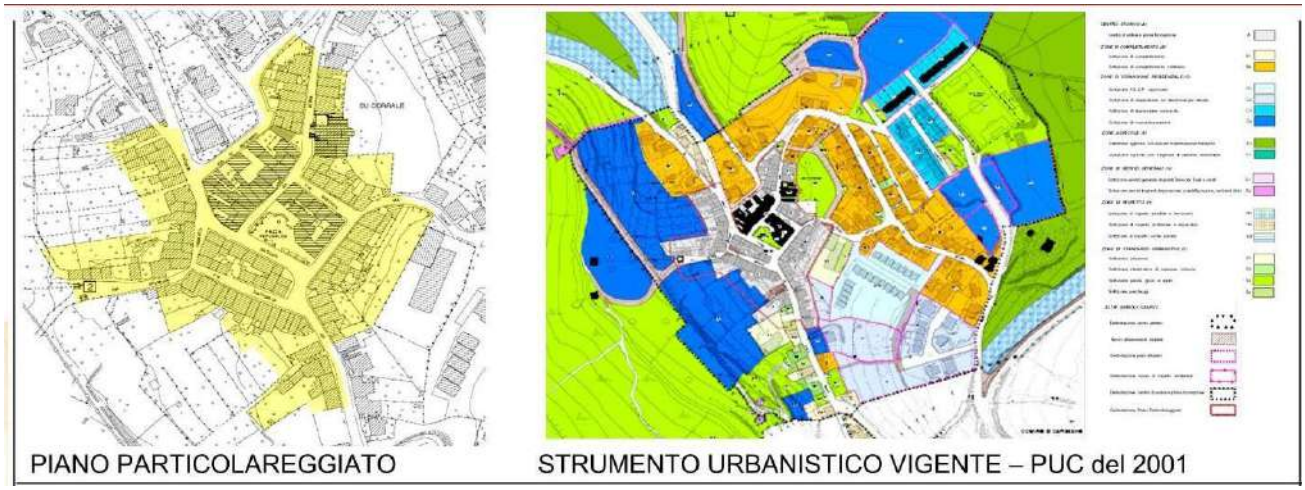

FIGURA 6 – PUC MUROS

REGOLARITÀ EDILIZIA

RIF. UNICO PER I DUE BENI.

L'immobile **non risulta regolare** per la legge nº 47/1985.

La costruzione è antecedente al 01/09/1967.

Non sono presenti vincoli artistici, storici o alberghieri.

Non sono presenti diritti demaniali o usi civici.

L'immobile non risulta agibile.

Come da dichiarazione del responsabile dell'ufficio tecnico del comune di Muros in riscontro alla richiesta di accesso agli atti relativa all'acquisizione di documenti inerenti la concessione edilizia e/o concessione in sanatoria e ogni altro atto in possesso dell'immobile oggetto di perizia, negli atti e archivi non risulta alcuna pratica edilizia per l'immobile in oggetto.

Certificazioni energetiche e dichiarazioni di conformità

- Esiste il certificato energetico dell'immobile (APE)
  (redatto e prodotto e trasmesso al S.I.R.A. Sardegna dal sottoscritto Esperto del giudice come da punto 12 dell'incarico ricevuto)
- Non esiste la dichiarazione di conformità dell'impianto elettrico.
- Non esiste la dichiarazione di conformità dell'impianto termico.
- Non esiste la dichiarazione di conformità dell'impianto idrico.

VINCOLI ED ONERI CONDOMINIALI

RIF. UNICO PER I DUE BENI.

Non sono presenti vincoli od oneri condominiali.

Non sono presenti oneri pendenti di altro genere sul bene

STIMA / FORMAZIONE LOTTI

DESCRIZIONE DEL MERCATO IMMOBILIARE E FORMAZIONE PREZZO

La base di stima del mercato immobiliare a Muros è praticamente inesistente, Muros ha una popolazione di 819 abitanti. Dai dati dell'osservatorio immobiliare solamente meno dell'1% di tutti gli annunci immobiliari della provincia sono relativi Muros

In totale sono stati rilevati dall'osservatorio immobiliare 31 annunci immobiliari, di cui 10 in vendita e 21 in affitto, con un indice complessivo di 37 annunci per mille abitanti.

Secondo i dati dell'OMI, il prezzo degli appartamenti nelle diverse zone a Muros è compreso tra 755 €/m² e 1.000 €/m² per la compravendita e tra 3,4 €/m² mese e 4,5 €/m² mese per quanto riguarda le locazioni.

A dicembre 2024 per gli immobili residenziali in vendita sono stati richiesti in media € 805 al metro quadro, con una diminuzione del 14,81% rispetto a dicembre 2023 (945 €/m²). Negli ultimi 2 anni, il prezzo medio all'interno del comune di Muros ha raggiunto il suo massimo nel mese di giugno 2024, con un valore di € 1.025 al metro quadro. Il mese in cui è stato richiesto il prezzo più basso è stato marzo 2023: per un immobile in vendita sono stati richiesti in media € 744 al metro quadro.

In sintesi le quotazioni ufficiali dell'Agenzia delle Entrate per il comune di Muros con riferimento al primo semestre dell'anno 2024 per abitazioni di tipo economico si attestano alla forchetta di valori compresi tra i 700 ed i 900 €/mq.

Banca dati delle quotazioni immobiliari - Risultato

Risultato interrogazione: Anno 2024 - Semestre 1
Provincia: SASSARI
Comune: MUROS
Fascia/zona: Centrale/CENTRO%20URBANO
Codice zona: B1
Microzona: 1
Tipologia prevalente: Abitazioni di tipo economico
Destinazione: Residenziale

Tipologia	Stato conservativo	Valore Mercato (€/mq)		Superficie (L/N)	Valori Locazione (€/mq x mese)		Superficie (L/N)
		Min	Max		Min	Max	
Abitazioni civili	Normale	800	1100	L	3,4	4,6	L
Abitazioni di tipo economico	Normale	700	900	L	3	3,8	L
Box	Normale	300	350	L	1,5	1,8	L

FIGURA 7 – SCHEMA VALORI AMBITO LOCALE AGENZIA ENTRATE

In considerazione della posizione periferica del bene e della conformazione con una parte interrata e senza aperture il prezzo di compravendita col bene **completamente ristrutturato** si attesta sul valore minimo di 700 €/mq.

Si è controllato presso l'IVG la valutazione e le iniziative di acquisto ad oggi di beni simili, in particolare nei comuni vicini di Ossi, di Usini e di Uri, e si è potuto constatare la completa stagnazione del mercato, il che porta a grandi ribassi nelle offerte di acquisto. La valutazione non può ovviamente basarsi su tali situazioni particolari legate al tipo di vendita forzata dei beni, ma non può non tenerne in parte conto, ragione per cui in maniera cautelativa si ipotizza un prezzo di compravendita ribassato di una ulteriore aliquota dei circa il 15%.

VALORI UNITARI DI STIMA

Considerando quindi la qualità, la posizione del bene e il suo stato di conservazione, nell'ipotesi di bene liberamente commerciabile ed in condizioni di fruibilità, il sottoscritto CTU in base a tutto quanto riportato nella presente relazione, agli esiti del sopralluogo, alla valutazione comparativa dei vari prezzi unitari ed in base alla sua esperienza e formazione professionale ritiene equo formare un prezzo di applicazione unico per il bene in valutazione, parametro inteso per un bene **completamente ristrutturato e regolarizzato:**

Valore unitario [€/mq]
595,00

FORMAZIONE LOTTI

Lo scrivente ha ritenuto opportuno procedere alla formazione di un lotto unico così costituito:

- **Bene Nº 1** - Appartamento ubicato a Muros (SS) - Via Brigata Sassari, 6, piano 1S

  Appartamento fronte strada a due livelli più cortile sul retro costituito da un fabbricato abitativo composto da soggiorno, cucina, disimpegno, due camere e un bagno, nonché da un locale magazzino. Le due unità immobiliari hanno rispettivamente ingressi uno dal cortile al quale si accede da una rampa di scale dalla via Mannu e l'altro dalla Via Brigata Sassari. Il locale abitazione con ingresso dal cortile in via Mannu è collegato con il piano inferiore a mezzo di una scala interna.

  Identificato al catasto Fabbricati - Fg. 12, Part. 229, Sub. 1, Categoria A3

  L'immobile viene posto in vendita per il diritto di Proprietà (1/1)

  Valore di stima del bene: € 104.083,35

- **Bene Nº 2** - Magazzino ubicato a Muros (SS) - Via Brigata Sassari, 6, piano 1S

  Locale magazzino al piano terra di un appartamento fronte strada a due livelli più cortile sul retro. Le due unità immobiliari hanno rispettivamente ingressi uno dal cortile al quale si accede da una rampa di scale dalla via Mannu e l'altro dalla Via Brigata Sassari.

  Identificato al catasto Fabbricati - Fg. 12, Part. 229, Sub. 3, Categoria A6

  L'immobile viene posto in vendita per il diritto di Proprietà (1/1)

  Valore di stima del bene: € 4.504,15

Identificativo corpo	Superficie convenzionale	Valore unitario	Valore complessivo	Quota in vendita	Totale
Bene Nº 1 - Appartamento Muros (SS) - Via Brigata Sassari, 6, piano 1S	174,93 mq	595,00 €/mq	€ 104.083,35	100,00%	€ 104.083,35
Bene Nº 2 - Magazzino Muros (SS) - Via Brigata Sassari, 6, piano 1S	7,57 mq	595,00 €/mq	€ 4.504,15	100,00%	€ 4.504,15
				Valore di stima:	**€ 108.587,50**

Valore di stima lorda: € **108.587,50**

COSTI DI RISTRUTTURAZIONE

Per stimare i costi di ristrutturazione da porre in detrazione tra i deprezzamenti ci si riferisce ai dati rilevati da diversi siti specializzati (*hausme.it, edilnet.it, domidea-ristrutturazioni.it etc.*) e si sono ipotizzate alcune voci tipiche quali:

- piccole modifiche alla distribuzione interna
- rifacimento di bagni e cucina
- nuovi impianti
- ripristino pavimenti ammalorati (in parte anche sovrapposti)
- pitturazione
- nuovi infissi esterni e porte interne (e/o ripristino di quelli esistenti)

Ovvero quella che tecnicamente viene comunemente chiamata "ristrutturazione minima", ma che in questo caso è anche indispensabile.[3] Visto lo stato in cui al momento versa il bene.

DEPREZZAMENTI

Tipologia deprezzamento	Valore	Tipo
Mancata SCIA e costo tecnico di regolarizzazione e progettazione variante e DL	12.000,00	€
Aggiornamento dati e planimetrie catastali	2.000,00	€
Demolizione e smaltimento tettoia abusiva e ripristino funzionalità cortile	3.500,00	€
Completamento dei lavori di ristrutturazione edilizia ed impiantistica (stimato in 180 €/mq x 220 mq lordi)	39.600,00	€
Oneri per certificazioni, collaudi ed ottenimento dell'agibilità	3.500,00	€
Totale	**60.600,00**	**€**

RISPOSTA AL QUESITO AGGIUNTIVO DEL GIUDICE

Il valore dei deprezzamenti utilizzato è comprensivo di una serie di lavorazioni atte a rendere appetibile e vendibile il bene. Alcuni di questi interventi migliorativi non sono essenziali per la piena funzionalità e commerciabilità dell'immobile, quali tinteggiature interne di carattere estetico e sostituzione degli infissi esistenti in assenza di comprovate condizioni di degrado strutturale.
Tali interventi, sebbene migliorativi sotto il profilo estetico o energetico, **e** pur potendo incrementare il valore percepito dell'immobile sul mercato, **non compromettono la fruibilità, la regolarità urbanistica o l'abitabilità del bene**, e pertanto possono non venire considerati ai fini della determinazione del valore

[3] *Per tutto quanto sopra riportato è necessario segnalare in conclusione che il bene oggetto di perizia non sarebbe regolarmente commerciabile e che per renderlo tale in estrema sintesi necessiterebbe di:*

- *lavori edilizi di ristrutturazione*
- *regolarizzazione edilizia e certificazioni*
- *certificato di agibilità*

con i relativi costi sopra stimati ed i corrispondenti tempi tecnici ed amministrativi per avere la piena fruibilità e commerciabilità del bene.

In sostanza si possono escludere tutte le pitturazioni interne di pareti e soffitti (630 mq) e la ristrutturazione degli infissi esterni (18 mq) e la sostituzione deli infissi interni (n.5)

Importi che si possono escludere dal conteggio dei deprezzamenti

Pitturazioni interne	mq 630,00	8,5 €/mq	€ 5.335,00
Ristrutturazione infissi esterni	mq 18,00	450 €/mq	€ 8.100,00
Sostituzione porter interne	n. 5	110,00 €/cad	€ 550,00
		Totale	**€ 13.985,00**

Valore di stima lordo + € **108.587,50**

Importo complessivo deprezzamento: - **€ 60.600,00**

Importo deprezzamento non necessario per la vendita **+ € 13.985,00**

Valore finale di stima: **€ 61.972,50**

In conto tondo quindi:

Valore finale di stima **€ 62.000,00 (EURO SESSANTADUEMILA/00)**

FIRMA E CHIUSURA PERIZIA

Assolto il proprio mandato, il sottoscritto Esperto ex art. 568 C.P.C., avendo dato evidenza della stessa alle parti ricevute, deposita la relazione di stima presso questo Spettabile Tribunale, tanto in assolvimento dell'incarico conferitogli dalla S.V. e resta a disposizione per eventuali chiarimenti

Sassari, li 02/05/2025

L'Esperto ex art. 568 C.P.C.
Ing. Alessandro Antonio Sanna

Allegati:

- *B1) Quesiti del giudice*
- *C1) Documentazione Agenzia Entrate (Catasto)*
- *C2) Documentazione Agenzia Entrate (Conservatoria)*
- *C3) Dichiarazione Ufficio Tecnico Comune di Muros*
- *C4) Documentazione Fotografica*
- *C5) Attestazione Prestazione Energetica*

ATTESTATO DI PRESTAZIONE ENERGETICA DEGLI EDIFICI

CODICE IDENTIFICATIVO: AS 01/25 — VALIDO FINO: 25/01/2035

APE 2015

DATI GENERALI

Destinazione d'uso

- [X] Residenziale
- [ ] Non residenziale

Classificazione D.P.R. 412/93: E.1(1)

Oggetto dell'attestato

- [X] Intero edificio
- [ ] Unità immobiliare
- [ ] Gruppo di unità immobiliari

Numero di unità immobiliari di cui è composto l'edificio: 2

- [ ] Nuova costruzione
- [X] Passaggio di proprietà
- [ ] Locazione
- [ ] Ristrutturazione importante
- [ ] Riqualificazione energetica
- [ ] Altro:_____

Dati identificativi

Regione: Sardegna

Comune: Muros (SS)

Indirizzo: Via Brigata Sassari 6

Piano: T-1

Interno: -

Coordinate GIS: 40,666667, 8,616667

Zona climatica: D

Anno di costruzione: 1964

Superficie utile riscaldata: 164,0 m²

Superficie utile raffrescata: 0,0 m²

V lordo riscaldato: 565,0 m³

V lordo raffrescato: 0,0 m³

Comune catastale	F818								Sezione		Foglio		12				Particella		229	
Subalterni	da	1	a	1		da	3	a	3		da		a			da		a		
Altri subalterni																				

Servizi energetici presenti

- [X] Climatizzazione invernale
- [ ] Climatizzazione estiva
- [ ] Ventilazione meccanica
- [X] Prod. acqua calda sanitaria
- [ ] Illuminazione
- [ ] Trasporto di persone o cose

PRESTAZIONE ENERGETICA GLOBALE E DEL FABBRICATO

La sezione riporta l'indice di prestazione energetica globale non rinnovabile in funzione del fabbricato e dei servizi energetici presenti, nonché la prestazione energetica del fabbricato, al netto del rendimento degli impianti presenti.

Prestazione energetica del fabbricato

INVERNO	ESTATE

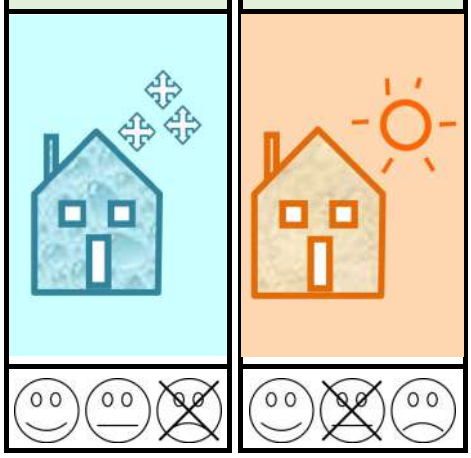

Prestazione energetica globale

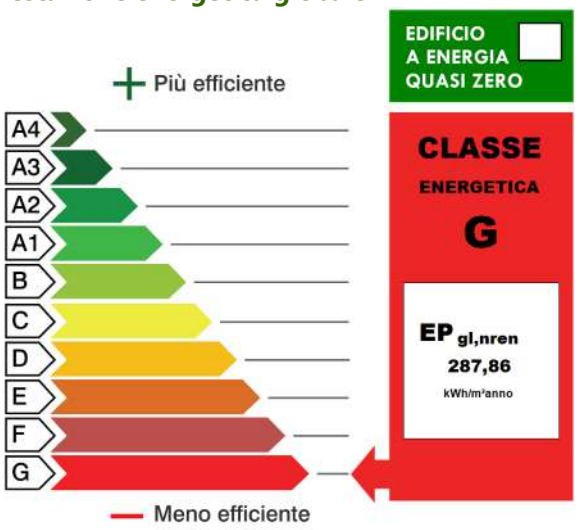

Riferimenti

Gli immobili simili a questo avrebbero in media la seguente classificazione:

Se nuovi:

C (67,32 kWh/m²)

Se esistenti:

PRESTAZIONE ENERGETICA DEGLI IMPIANTI E CONSUMI STIMATI

La sezione riporta gli indici di prestazione energetica rinnovabile e non rinnovabile, nonché una stima dell'energia consumata annualmente dall'immobile secondo un uso standard.

Prestazioni energetiche degli impianti e stima dei consumi annui di energia

	FONTI ENERGETICHE UTILIZZATE	Quantità annua consumata in uso standard (specificare unità di misura)	Indici di prestazione energetica globali ed emissioni
☒	Energia elettrica da rete	3351 kWh	Indice della prestazione energetica non rinnovabile EPgl,nren kWh/m² anno 287,86
☒	Gas naturale	4099 m³	
☐	GPL		
☐	Carbone		
☐	Gasolio e olio combustibile		
☐	Biomasse solide		Indice della prestazione energetica rinnovabile EPgl,ren kWh/m² anno 9,60
☐	Biomasse liquide		
☐	Biomasse gassose		
☐	Solare fotovoltaico		
☐	Solare termico		
☐	Eolico		Emissioni di CO_2 kg/m² anno 59,0
☐	Teleriscaldamento		
☐	Teleraffrescamento		
☐	Altro (specificare)		

RACCOMANDAZIONI

La sezione riporta gli interventi raccomandati e la stima dei risultati conseguibili, con il singolo intervento o con la realizzazione dell'insieme di essi, esprimendo una valutazione di massima del potenziale di miglioramento dell'edificio o immobile oggetto dell'attestato di prestazione energetica.

RIQUALIFICAZIONE ENERGETICA E RISTRUTTURAZIONE IMPORTANTE

INTERVENTI RACCOMANDATI E RISULTATI CONSEGUIBILI

Codice	TIPO DI INTERVENTO RACCOMANDATO	Comporta una ristrutturazione importante	Tempo di ritorno dell'investimento anni	Classe Energetica raggiungibile con l'intervento	CLASSE ENERGETICA raggiungibile se si realizzano tutti gli interventi raccomandati
REN1	Intervento sulle strutture opache	No	3,5 anni	G (206,05 kWh/m²anno)	F (172,86) kWh/m² anno
REN2	Intervento sui serramenti	No	9,5 anni	G (254,67 kWh/m²anno)	
REN3					
REN4					
REN5					
REN6					

DATI ENERGETICI GENERALI

Energia esportata	0,00 **kWh/anno**	**Vettore energetico:** -

DATI DI DETTAGLIO DEL FABBRICATO

SUPERFICI E RAPPORTO DI FORMA		
V - Volume riscaldato	565,0	**m³**
Superficie disperdente	381,6	**m²**
Rapporto S/V	0,68	
$EP_{H,nd}$	182,13	**kWh/m² anno**
Asol,est/A suputile	0,0255	**-**
YIE	1,525	**W/m²K**

DATI DI DETTAGLIO DEGLI IMPIANTI

Servizio energetico	Tipo di impianto	Anno di installazione	Codice catasto regionale impianti	Vettore energetico utilizzato	Potenza Nominale kW	Efficienza media stagionale		EPren	EPnren
Climatizzazione invernale	1- Impianto simulato in quanto assente			Metano		0,734	η_H	0,00 kWh/m²anno	248,02 kWh/m²anno
	2-								
Climatizzazione estiva	1-						η_C		
	2-								
Produzione acqua calda sanitaria	Generatore a energia elettrica	2018		Energia elettrica	1,20	0,277	η_W	9,60 kWh/m²anno	39,84 kWh/m²anno
Impianti combinati									
Prod. da fonti rinnovabili	1-								
	2-								
Ventilazione meccanica									
Illuminazione									
Trasporto di persone o cose	1-								
	2-								

INFORMAZIONI SUL MIGLIORAMENTO DELLA PRESTAZIONE ENERGETICA

La sezione riporta informazioni sulle opportunità, anche in termini di strumenti di sostegno nazionali o locali, legate all'esecuzione di diagnosi energetiche e interventi di riqualificazione energetica, comprese le ristrutturazioni importanti.

SOGGETTO CERTIFICATORE

☐ Ente/Organismo pubblico	☒ Tecnico abilitato	☐ Organismo/Società

Nome e Cognome / Denominazione	Sanna Alessandro
Indirizzo	Via Bogino 25 07100 Sassari (SS)
E-mail	sandro.sanna@gmail.com
Telefono	
Titolo	Ing.
Ordine/iscrizione	Ingegneri 419
Dichiarazione di indipendenza	Il sottoscritto certificatore, consapevole delle responsabilità assunte ai sensi degli artt.359 e 481 del Codice Penale, DICHIARA di aver svolto con indipendenza ed imparzialità di giudizio l'attività di Soggetto Certificatore del sistema edificio impianto oggetto del presente attestato e l'assenza di conflitto di interessi ai sensi dell'art.3 del D.P.R. 16 aprile 2013, n. 75.
Informazioni aggiuntive	Albo certificatori R.A.S. n. 218

SOPRALLUOGHI E DATI DI INGRESSO

E' stato eseguito almeno un sopralluogo/rilievo sull'edificio obbligatorio per la redazione del presente APE?	Sì

SOFTWARE UTILIZZATO

Il software utilizzato risponde ai requisiti di rispondenza e garanzia di scostamento massimo dei risultati conseguiti rispetto ai valori ottenuti per mezzo dello strumento di riferimento nazionale?	Sì
Ai fini della redazione del presente attestato è stato utilizzato un software che impieghi un metodo di calcolo semplificato?	No

Il presente attestato è reso, dal sottoscritto, in forma di dichiarazione sostitutiva di atto notorio ai sensi dell'articolo 47 del D.P.R. 445/2000 e dell'articolo 15, comma 1 del D.Lgs 192/2005 così come modificato dall'articolo 12 del D.L 63/2013.

Data di emissione 25/01/2025

Firma e timbro del tecnico_____

LEGENDA E NOTE PER LA COMPILAZIONE

Il presente documento attesta la **prestazione** e la **classe energetica** dell'edificio o dell'unità immobiliare, ovvero la quantità di ener-gia necessaria ad assicurare il comfort attraverso i diversi servizi erogati dai sistemi tecnici presenti, in condizioni convenzionali d'uso. Al fine di individuare le potenzialità di miglioramento della prestazione energetica, l'attestato riporta informazioni specifiche sulle prestazioni energetiche del fabbricato e degli impianti. Viene altresì indicata la classe energetica più elevata raggiungibile in caso di realizzazione delle misure migliorative consigliate, così come descritte nella sezione "**raccomandazioni**" (pag.2).

PRIMA PAGINA

Informazioni generali: tra le informazioni generali è riportata la motivazione alla base della redazione dell'APE. Nell'ambito del periodo di validità, ciò non preclude l'uso dell'APE stesso per i fini di legge, anche se differenti da quelli ivi indicati.
Prestazione energetica globale (EPgl,nren) : fabbisogno annuale di energia primaria non rinnovabile relativa a tutti i servizi ero-gati dai sistemi tecnici presenti, in base al quale è identificata la classe di prestazione dell'edificio in una scala da A4 (edificio più efficiente) a G (edificio meno efficiente).
Prestazione energetica del fabbricato: indice qualitativo del fabbisogno di energia necessario per il soddisfacimento del confort interno, indipendente dalla tipologia e dal rendimento degli impianti presenti. Tale indice da un'indicazione di come l'edificio, d'estate e d'inverno, isola termicamente gli ambienti interni rispetto all'ambiente esterno. La scala di valutazione qualitativa utilizza-ta osserva il seguente criterio:

QUALITA' ALTA	**QUALITA' MEDIA**	**QUALITA' BASSA**

I valori di soglia per la definizione del livello di qualità, suddivisi per tipo di indicatore, sono riportati nelle Linee guida per l'attestazione energetica degli edifici di cui al decreto previsto dall'articolo 6, comma 12 del d.lgs. 192/2005.
Edificio a energia quasi zero: edificio ad altissima prestazione energetica, calcolata conformemente alle disposizioni del decreto legislativo 19 agosto 2005, n. 192 e del decreto ministeriale sui requisiti minimi previsto dall'articolo 4, comma 1 del d.lgs. 192/2005. Il fabbisogno energetico molto basso o quasi nullo è coperto in misura significativa da energia da fonti rinnovabili, pro-dotta all'interno del confine del sistema (in situ). Una spunta sull'apposito spazio adiacente alla scala di classificazione indica l'appartenenza dell'edificio oggetto dell'APE a questa categoria.
Riferimenti: raffronto con l'indice di prestazione globale non rinnovabile di un edificio simile ma dotato dei requisiti minimi degli edifici nuovi, nonché con la media degli indici di prestazione degli edifici esistenti simili, ovvero contraddistinti da stessa tipologia d'uso, tipologia costruttiva, zona climatica, dimensioni ed esposizione di quello oggetto dell'attestato.

SECONDA PAGINA

Prestazioni energetiche degli impianti e consumi stimati: la sezione riporta l'indice di prestazione energetica rinnovabile e non rinnovabile dell'immobile oggetto di attestazione. Tali indici informano sulla percentuale di energia rinnovabile utilizzata dall'immobile rispetto al totale. La sezione riporta infine una stima del quantitativo di energia consumata annualmente dall'immobile secondo un uso standard, suddivisi per tipologia di fonte energetica utilizzata.

Raccomandazioni: di seguito si riporta la tabella che classifica le tipologie di intervento raccomandate per la riqualificazione e-nergetica e la ristrutturazione importante.

RIQUALIFICAZIONE ENERGETICA E RISTRUTTURAZIONE IMPORTANTE EDIFICIO/UNITA' IMMOBILIARE - Tabella dei Codici Intervento

Codice	TIPO DI INTERVENTO
REN1	FABBRICATO - INVOLUCRO OPACO
REN2	FABBRICATO - INVOLUCRO TRASPARENTE
REN3	IMPIANTO CLIMATIZZAZIONE - INVERNO
REN4	IMPIANTO CLIMATIZZAZIONE - ESTATE
REN5	ALTRI IMPIANTI
REN6	FONTI RINNOVABILI

TERZA PAGINA

La terza pagina riporta la quantità di energia prodotta in situ ed esportata annualmente, nonché la sua tipologia.
Riporta infine, suddivise in due sezioni relative rispettivamente al fabbricato e agli impianti, i dati di maggior dettaglio alla base del calcolo.