TRIBUNALE DI SASSARI

SEZIONE EE.II.

Perizia dell'Esperto ex art. 568 c.p.c. Dott.ssa Carboni Maria Grazia nell'Esecuzione Immobiliare 124/2023 del R.G.E.

promossa da

contro

Dott.ssa Carboni Maria Grazia Sede legale Via Ugo la Malfa, 32– 07100 Sassari
Tel. 3476650385; E-mail: studiomariagraziacarboni@gmail.com Pec: maria_grazia.carboni@conafpec.it
C.F. CRBMGR78H56I452Z - P.IVA 02351260902

Firmato Da: CARBONI MARIA GRAZIA Emesso Da: NAMIRIAL CA FIRMA QUALIFICATA Serial#: 2ac261897f278213

SOMMARIO

Incarico 4

Premessa 4

Descrizione 4

Bene N° 1 - Fabbricato artigianale ubicato a SOrso (SS) - Zona Artigianale Sant'Igliano - Foglio 56, particella 1233, sub 1 4

Bene N° 2 - Fabbricato artigianale ubicato a SOrso (SS) - Zona Artigianale Sant'Igliano - Foglio 56, particella 1233, sub 2 5

LOTTO 1 5

Completezza documentazione ex art. 567 5

Titolarità 5

Consistenza 6

CRONISTORIA Dati Catastali 6

Dati Catastali 7

STATO CONSERVATIVO 7

PARTI COMUNI 7

stato occupazione 7

Provenienze Ventennali 8

formalita' pregiudizievoli 8

normativa urbanistica 8

Regolarità edilizia 9

Confronto tra stato attuale e progetto autorizzato - difformità 9

Sanabilità 9

Certificazioni energetiche e dichiarazioni di conformità 10

vincoli od oneri condominiali 10

LOTTO 2 11

Completezza documentazione ex art. 567 11

Titolarità 11

Consistenza 11

CRONISTORIA Dati Catastali 12

Dati Catastali 12

STATO CONSERVATIVO 13

PARTI COMUNI 13

stato occupazione 13

Provenienze Ventennali 13

formalita' pregiudizievoli 13

normativa urbanistica 14

Firmato Da: CARBONI MARIA GRAZIA Emesso Da: NAMIRIAL CA FIRMA QUALIFICATA Serial#: 2ac261897f278213

Regolarità edilizia 14
Confronto tra stato attuale e progetto autorizzato - difformità 14
Sanabilità 15
Certificazioni energetiche e dichiarazioni di conformità 16
vincoli od oneri condominiali 16
Stima / Formazione lotti 17
Aspetti economici e procedimenti estimativi - Generalità 17
Valutazione del più probabile valore di mercato 18
Lotto 1 20
Lotto 2 20
Riepilogo bando d'asta 22
Lotto 1 22
Lotto 2 22
Schema riassuntivo Esecuzione Immobiliare 124/2023 del R.G.E. 23
Lotto 1 23
Lotto 2 23

Firmato Da: CARBONI MARIA GRAZIA Emesso Da: NAMIRIAL CA FIRMA QUALIFICATA Serial#: 2ac261897f278213

INCARICO

All'udienza del 4 giugno 2024, la sottoscritta DOTT.SSA CARBONI MARIA GRAZIA con studio in Sassari (SS), e-mail: studiomariagraziacarboni@gmail.com PEC: maria_grazia.carboni@conafpec.it, veniva nominato Esperto ex art. 568 c.p.c. La nomina è stata notificata il giorno 05 giugno 2024 e in data 10 giugno 2024 accettava l'incarico e prestava giuramento di rito.

PREMESSA

I beni oggetto di pignoramento sono costituiti dai seguenti immobili:

- **Bene 1** – Fabbricato artigianale ubicato a Sorso (SS) - Zona Artigianale Sant'Igliano N. Snc - Piano T Censito nel Catasto Fabbricati del Comune di Sorso al Foglio 56, particella 1233, sub 1, categoria C/3, classe 2, 210 mq, rendita 466,36 €

- **Bene 2** - Fabbricato artigianale ubicato a Sorso (SS) - Zona Artigianale Sant'Igliano N. Snc - Piano T Censito nel Catasto Fabbricati del Comune di Sorso al Foglio 56, particella 1233, sub 2, categoria C/3, classe 2, 210 mq, rendita 466,36 €

I suddetti bene sono stati ispezionati, misurati e fotografati dalla sottoscritta in un sopralluogo effettuato il 29/07/2024 alle ore 16:00 con la collaborazione del custode giudiziario (IVG) e il permesso Sig. occupante affittuario e dell'esecutato Sig. . Non è stato pertanto necessario effettuare un accesso forzoso. Si allegano le fotografie rappresentative dello stato attuale delle unità immobiliari. (Allegato n 1).
Gli immobili risultano essere catastalmente e realmente divisi e indipendenti e formano pertanto due lotti separati.

DESCRIZIONE

BENE N° 1 - FABBRICATO ARTIGIANALE UBICATO A SORSO (SS) - ZONA ARTIGIANALE SANT'IGLIANO - FOGLIO 56, PARTICELLA 1233, SUB 1

L'immobile oggetto del pignoramento è censito al N.C.E.U. del Comune di Sorso al Foglio 56, particella 1233, sub 1 ed è situato in Zona Artigianale Sant'Igliano, zona industriale/artigianale del centro abitato del Comune di Sorso
L'unità ad uso artigianale è ubicata al piano terra di un immobile che si sviluppa su n° 1 piani fuori terra e, da patio esterno di proprietà esclusiva.
Dalla strada principale, si accede per mezzo di cancello carraio, al patio di pertinenza della proprietà; percorrendo tale patio si può accedere al locale ufficio nel lato sinistro dell'immobile e tramite portellone frontale direttamente al locale attività: L'unità immobiliare è composta da: locale attività uffici con annessi servizi, locale deposito al piano primo (sopra locale uffici) e patio esterno.
La struttura portante e il solaio dello stabile sono di tipo prefabbricato (intelaiato), le tamponature principali in laterizio, i solai intermedi sono misti in legno nella zona ufficio e in latero-cemento nella zona servizi.
L'unita immobiliare presenta pavimentazione in battuto di cemento nel locale attività, in gress nel locale uffici, le pareti sono intonacati e opportunamente tinteggiate/i, ad eccezione delle pareti dei servizi igienici che risultano rivestite con piastrelle; gli infissi esterni sono in ferro con vetro singolo con annessi portelloni in ferro, le porte interne risultano in compensato, gli impianti idrico-sanitario dell'immobile è realizzati sottotraccia mentre l'impianto elettrico è di tipo industriale

Firmato Da: CARBONI MARIA GRAZIA Emesso Da: NAMIRIAL CA FIRMA QUALIFICATA Serial#: 2ac261897f278213

BENE N° 2 - FABBRICATO ARTIGIANALE UBICATO A SORSO (SS) - ZONA ARTIGIANALE SANT'IGLIANO - FOGLIO 56, PARTICELLA 1233, SUB 2

L'immobile oggetto del pignoramento è censito al N.C.E.U. del Comune di Sorso al Foglio 56, particella 1233, sub 2 ed è situato in Zona Artigianale Sant'Igliano, zona industriale/artigianale del centro abitato del Comune di Sorso.
L'unità ad uso artigianale è ubicata al piano terra di un immobile che si sviluppa su n° 1 piani fuori terra e, da patio esterno di proprietà esclusiva.
Dalla strada principale, si accede per mezzo di cancello carraio e rampa, al patio di pertinenza della proprietà; percorrendo tale patio si può accedere tramite portellone frontale direttamente al locale attività.
L'unità immobiliare è composta da: locale attività ufficio costituito da struttura precaria (soppalco) e patio esterno.
La struttura portante e il solaio dello stabile sono di tipo prefabbricato (intelaiato), le tamponature principali in laterizio, i solai intermedi sono misti in legno nella zona ufficio.
L'unita immobiliare presenta pavimentazione in battuto di cemento, le pareti sono intonacati e opportunamente tinteggiate/i; gli infissi esterni sono in ferro con vetro singolo con annessi portelloni in ferro, le porte interne risultano in compensato, l'impianto elettrico è di tipo industriale

LOTTO 1

Il lotto è formato dai seguenti beni:

- **Bene 1** - Fabbricato artigianale ubicato a Sorso (SS) - Zona Artigianale Sant'Igliano N. Snc - Piano T
  Censito nel Catasto Fabbricati del Comune di Sorso al Foglio 56, particella 1233, sub 1, categoria C/3, classe 2, 210 mq, rendita 466,36 €

COMPLETEZZA DOCUMENTAZIONE EX ART. 567

In relazione al controllo della completezza della documentazione ex art. 567 si riferisce quanto segue.
Il creditore procedente ha prodotto un Certificato notarile sostitutivo della certificazione storica ipotecaria e catastale a firma del Dott. Maurizio Lunetta, Notaio in San Giuseppe Jato, Nuoro (Pa). Tale Certificato, attesta le risultanze delle visure storiche catastali e dei registri immobiliari relative all'immobile pignorato fino al 24/10/2023.
Sono inoltre presenti l'atto di pignoramento e la relativa trascrizione
La suddetta certificazione è stata integrata dalla sottoscritta con le visure catastali e ipotecarie aggiornate, con la planimetria catastale dell'unità immobiliare, oltre che alla documentazione comunale.
La documentazione integrativa acquisita dalla sottoscritta si trova allegata alla presente perizia come Allegato n. 2 (documentazione catastale e ispezione ipotecaria) e, Allegato n. 3 (documentazione comunale).

Si attesta perciò che la documentazione di cui all'art. 567 c.p.c., comma 2 risulta completa.

TITOLARITÀ

I dati sulla titolarità, la provenienza ventennale, la cronistoria catastale e le formalità pregiudizievoli sono stati estratti dalla suddetta Certificazione notarile a cui si rinvia per controllo e per ogni ulteriore informazione non riversata in questa relazione.

Il bene pignorato non corrisponde a quello descritto nel titolo di provenienza (atto cessione mutuo) inquanto lo stesso è stato oggetto variazioni catastali successive eseguite per l'edificazione dell'immobile artigianale oggi

Firmato Da: CARBONI MARIA GRAZIA Emesso Da: NAMIRIAL CA FIRMA QUALIFICATA Serial#: 2ac261897f278213

presente. Si evidenzia che allo stato originario il bene oggetto di mutuo risultava essere definito da un "Lotto di area edificabile sito all'interno del comparto D13 del Piano Urbanistico Comunale, contrassegnato con il n. 9, della superficie complessiva di 1244 mq circa, distinto nel Catasto Terreni del Comune di Sorso al Foglio 56: Mappale 563, 559, 574. Il Mappale 559 unitamente ai Mappali 563 e 574 sono stati variati e unificati costituendo l'Ente Urbano distinto con il Mappale 1233 in cui attualmente sorgono le unità immobiliari distinte al Catasto Fabbricati con il Foglio 56, Mappale 1233 subalterni 1 e 2, oggetto di pignoramento.

L'immobile oggetto dell'esecuzione appartiene ai seguenti esecutati:

- (Proprietà 1/1)
  Codice fiscale:

Il bene sopra indicato è pignorato **per intero** e viene posto in vendita per i seguenti diritti:

- (Proprietà 1/1)

CONSISTENZA

Destinazione	Superficie Lorda	Coefficiente	Superficie Convenzionale	Altezza	Piano
Locale attività	194,00 mq	1,00	194,00 mq	5,50 m	T
Zona Uffici e annessi	36,00 mq	1,00	36,00 mq	2,70 m	T
Deposito soppalco	31,00 mq	0,25	7,75 mq	2,55 m	1° soppalco
Area Esterna	396,00 mq	0,10	39,60 mq		
		Totale superficie convenzionale	**277,35 mq**		
		Totale superficie in C.T.	**277,00 mq**		

La misura della superficie convenzionale è arrotondata al metro quadrato e la sua valutazione del fabbricato viene effettuata sulla base della superficie commerciale lorda (comprensiva dei muri) corretta di un coefficiente detto "coefficiente di ragguaglio" così come riportato "nell'Allegato C del DPR 138 del 23 marzo 1998" e nelle "Norme UNI 10750:2005"

Il bene non è comodamente divisibile.

CRONISTORIA DATI CATASTALI

L'identificazione catastale dell'unità immobiliare risulta aver subito le variazioni sottoindicate relativamente all' identificativo e alla categoria catastale così come riportato nella visura storica (Allegato 2).

Periodo	Proprietà	Dati Catastali
Dal 10/12/2021 al 15/12/2021	) Proprietà 1/1	Catasto Fabbricati Fg. 56, Part. 1233 Categoria F/6
Dal 15/12/2021 all'attualità	) Proprietà 1/1	Catasto Fabbricati Fg. 56, Part. 1233, Sub. 1 Categoria C/3 Cl.2, Cons. 210 mq Rendita € 466,36 Piano T

Firmato Da: CARBONI MARIA GRAZIA Emesso Da: NAMIRIAL CA FIRMA QUALIFICATA Serial#: 2ac261897f278213

DATI CATASTALI

Catasto fabbricati (CF)											
Dati identificativi				Dati di classamento							
Sezione	Foglio	Part.	Sub.	Zona Cens.	Categoria	Classe	Consistenza	Superficie catastale	Rendita	Piano	Graffato
	56	1233	1		C3	2	210 mq	270 mq	466,36 €	T	si

Corrispondenza catastale

NON Sussiste corrispondenza tra lo stato dei luoghi attuale e la planimetria catastale agli atti dell'Agenzia delle Entrate - Ufficio del Territorio di Sassari (Catasto).
Dal confronto tra lo stato rilevato e le planimetrie catastali in atti, si evidenzia la presenza della mancata identificazione al piano primo, sopra soppalco ufficio, del locale deposito
Le difformità sopra indicate all'interno dell'appartamento potranno essere regolarizzate mediante predisposizione di un atto di aggiornamento tramite procedura DOCFA presso l'Agenzia delle Entrate, per diversa distribuzione interna il cui costo si stima in € 500,00 tra oneri professionali e tributi speciali catastali (50,00 €).
Tale variazione può essere eseguita solo previa presentazione della relativa pratica di accertamento di conformità da presentare presso l'Ufficio Tecnico del Comune di Sassari, per cui la sottoscritta ritiene di non poter procedere in questa perizia alla regolarizzazione catastale in quanto le trasformazioni operate dovrebbero essere prima sanate dal punto di vista edilizio-urbanistico.
Si è riscontrato, a seguito dell'esame della documentazione in atti e, dall'esito di verifiche effettuate dalla scrivente, sia presso gli uffici dell'Agenzia del Territorio che tramite sopralluoghi che, gli attuali dati identificativi dell'unità immobiliare (numeri di Foglio, Particella, Subalterno, consistenza) corrispondono a quelli riportati nell'atto di pignoramento.

STATO CONSERVATIVO

Dal sopralluogo compiuto si è potuto desumere che il complesso immobiliare appare in buone condizioni conservative e di manutenzione.
L'unità immobiliare oggetto di esecuzione si presenta in un buono stato di manutenzione.

PARTI COMUNI

Non sono presenti parti comuni.

STATO OCCUPAZIONE

Il bene oggetto del pignoramento risulta in piena proprietà del soggetto pignorato e, al momento del sopralluogo risulta occupato tramite regolare contratto di affitto alla Ditta "
stipulato in data 25/01/2022, registrato in Sassari in data 25/01/2022 al n.000696 – serie 3T codice identificativo n. , della durata di 6 anni a decorrere dal 01/01/2022 e con scadenza il 01/01/2028, con rinnovo tacito per uguale periodo, salvo disdetta per finita locazione da comunicare all'altra parte almeno 6 mesi prima della scadenza.

Firmato Da: CARBONI MARIA GRAZIA Emesso Da: NAMIRIAL CA FIRMA QUALIFICATA Serial#: 2ac261897f278213

Nell'unità immobiliare sono presenti arredi e suppellettili che non rientrano tra i beni oggetto di questo pignoramento e che, pertanto, dovranno essere sgomberati a cura dei proprietari.

PROVENIENZE VENTENNALI

Per quanto riguarda l'immobile oggetto di pignoramento, sulla base dei dati reperiti dalla relazione notarile e, dalla visura ipotecaria storica reperita dalla sottoscritta, si evidenzia che:

- Sussiste continuità nelle trascrizioni per il ventennio precedente alla data di trascrizione del pignoramento;
- La situazione della proprietà antecedente il ventennio della trascrizione del pignoramento risulta variata;
- La situazione della proprietà risulta attualmente invariata.

FORMALITA' PREGIUDIZIEVOLI

A seguito dell'esecuzione dell'ispezione ipotecaria al fine di ottenere l'elenco aggiornato delle iscrizioni e trascrizioni a carico dei beni, si sono evidenziate le seguenti formalità riportate nell'Allegato 2 nel periodo di riferimento dal 19/10/1989 al 08/11/2024. (Ispezione n. T7213 del 10/11/2024)

TRASCRIZIONE del 23/10/2023 - ATTO ESECUTIVO O CAUTELARE - VERBALE DI PIGNORAMENTO IMMOBILI - Registro Particolare 13949 Registro Generale 18424 Pubblico ufficiale - UFFICIALE GIUDIZIARIO Repertorio 1983 del 22/09/2023
Nota disponibile in formato elettronico

Si evidenzia così come richiesto dall'Avv.to Demontis si evidenzia che il terreno originario distinto col Mappale 559 è stato sostituito dal Mappale 1233, al quale sono stati uniti i Mappali 563 e 574, così costituendo l'Ente Urbano censito col Mappale 1233; quest'ultimo, attualmente, corrisponde con le 2 unità immobiliari distinte al CF al Foglio 56, Mappale 1233, sub. 1 e sub. 2, oggetto di pignoramento.
Sul terreno così come da note allagate e da relazione notarile risulta essere presente
TRASCRIZIONE del 03/11/2006 - IPOTECA VOLONTARIA Derivante da CONCESSIONE A GARANZIA DI MUTUO CONDIZIONATO - Registro Particolare 3525 Registro Generale 18950 Pubblico ufficiale – Notaio PORQUEDDU ANDREA Repertorio 4602/2564 del 02/11/2006

NORMATIVA URBANISTICA

L'immobile in oggetto ricade secondo il P.U.C vigente del Comune di Sorso in Zona D – Sottozona D2.1.13- Insediamenti produttivi e artigianali compatibili con la residenza esistenti realizzati a seguito di Piano Insediamenti Produttivi (P.I.P.) normati dagli art. 25 delle NTA allegato allo strumento vigente.
Ricade inoltre per i piani sovraordinati in:
- secondo il **PGRA-F** (Piano di Gestione Rischio Alluvioni-Frane) l'immobile oggetto di relazione ricade in: zona Hg0 - Aree per le quali non sono state individuati fenomeni franosi in atto o potenziali
- secondo il **P.P.R**. l'immobile in oggetto ricade: nell'Ambito di Paesaggio 14 – Golfo dell'Asinara normate dagli art. 6, 12, 13, 14, 15, 107 e 112 delle NTA allegate al PPR vigente all'interno delle zone Tutelata - Beni Paesaggistici Ambientali (ex. Art. 143 D.Lgs. 42/2004 – Fascia Costiera normati dagli art. 8, 17, 18, 19, 20 delle NTA allegate al PPR

Firmato Da: CARBONI MARIA GRAZIA Emesso Da: NAMIRIAL CA FIRMA QUALIFICATA Serial#: 2ac261897f278213

REGOLARITÀ EDILIZIA

In merito alla regolarità dell'immobile, si relaziona quanto segue: (vedi Allegato 4).
A seguito di richiesta di accesso agli atti presso il Comune di Sorso (Prot.N. 23671 del 23/07/2024) si evidenzia che lo stabile in cui insite l'immobile oggetto di procedura è stato edificato mediante le seguenti concessioni:

- Concessione edilizia n. 70 del 29 giugno 2004 rilasciata alla Ditta per la costruzione di un "Capannone da destinare ad attività artigianale per deposito di materiale edili nell'area P.I.P. lotto n. 9 – Comparto di Lottizzazione D13 in Località Prunosa"
- Concessione edilizia in rinnovo n. 13 del 07 febbraio 2006;
- Concessione edilizia in variante n. 51 del 20 giugno 2007;
- SCIA in Sanatoria Concessione prot. N. 15694/323 del 03/06/2021 rilasciata alla Ditta per Scia in Sanatoria Per Variante In Corso D'opera Riguardante I Lavori Effettuati Nel Periodo Di Vigenza Del Titolo Abilitativo E Che Hanno Portato Ad Una Diversa Distribuzione Interna Degli Ambienti E La Modifica Di Prospetto Nel Capannone Artigianale In Sorso Area P.I.P. - Lotto N.9;
- Provvedimento unico n. 97 del 15/07/2021 rilasciato alla Ditta per Ristrutturazione Edilizia Per La Suddivisione Di Un Capannone Artigianale Da Una A Due Unità in Sorso Area P.I.P. - Lotto N.9 -

Si evidenzia altresì la presenza Dichiarazione di agibilità presentata con prot. N. 37695/780 del 30/12/2021

Confronto tra stato attuale e progetto autorizzato - difformità

Dal confronto tra gli elaborati grafici reperiti nel Provvedimento unico n. 97 del 15/07/2021 e lo stato reale, si evidenzia l'assenza di difformità rilevanti. Per completezza d'informazioni si sottolinea la mancata rappresentazione grafica della pianta del locale deposito inserito nel locale soppalco, rilevabile graficamente invece nelle sezioni presenti.

Si evidenzia altresì la presenza di un lieve difformità relativa all'altezza interna dei locali pari a 5,50 m, contro i 5,00 m indicati progettualmente.

Sanabilità

Si premette innanzi tutto che la sottoscritta non può pronunciarsi in modo definitivo in sostituzione degli Enti pubblici preposti a decidere sulle istanze di sanatoria dei privati con giudizi connotati da discrezionalità tecnico valutativa solo ad essi riservata e che può portare a diversi esiti. Può solo fornire un parere formato sulla base di orientamenti informali espressi dagli Uffici competenti che non esprimono valutazioni conclusive in assenza di un formale deposito di un progetto da istruire. Pertanto, tenendo conto di questo limite, all'esito dei colloqui avuti con gli uffici competenti si può riferire quanto di seguito.

Quanto alla possibilità di richiedere e ottenere una sanatoria ai sensi dell'art. 36 del T.U. dell'edilizia (DPR 380/2001) e dell'art. 16 della L. R. 23/85, tenendo in considerazione che le modiche delle disposizioni interne rilevate nell'unita unità immobiliare, sono definite ai sensi dell'art. 15 comma 2 punto b della LR 23/85 individuati al punto 351.k dell'Allegato B alla DGR 49/19 del 05/12/2019, interventi di manutenzione straordinaria che non riguardino le parti strutturali dell'edificio, *inquanto opere o modifiche necessarie per rinnovare e sostituire parti anche strutturali degli edifici, nonché per realizzare ed integrare i servizi igienico-sanitari e tecnologici, sempre che non alterino la volumetria complessiva degli edifici e non comportino mutamenti urbanisticamente rilevanti delle destinazioni d'uso implicanti incremento del carico urbanistico. …… Nell'ambito degli interventi di manutenzione straordinaria sono ricompresi anche quelli consistenti nel*

Firmato Da: CARBONI MARIA GRAZIA Emesso Da: NAMIRIAL CA FIRMA QUALIFICATA Serial#: 2ac261897f278213

frazionamento o accorpamento delle unità immobiliari con esecuzione di opere anche se comportanti la variazione delle superfici delle singole unità immobiliari nonché del carico urbanistico purché non sia modificata la volumetria complessiva degli edifici e si mantenga l'originaria destinazione d'uso. Nell'ambito degli interventi di manutenzione straordinaria sono comprese anche le modifiche ai prospetti degli edifici legittimamente realizzati necessarie per mantenere o acquisire l'agibilità dell'edificio ovvero per l'accesso allo stesso, che non pregiudichino il decoro architettonico dell'edificio, purché l'intervento risulti conforme alla vigente disciplina urbanistica ed edilizia e non abbia ad oggetto immobili sottoposti a tutela cosi come indicato nell'art. 3 Dpr 380/2001; sulla disposizioni dell'art 16 comma a dell'Allegato A alla DGR 49/19 del 05/12/2019, gli interventi oggetto di accertamento, ricadono nell'ambito delle "sanatorie" che si perfezionano attraverso la trasmissione di una dichiarazione autocertificativa ed il versamento di una sanzione ad effetto sanante di importo predeterminato per la mancata comunicazione di edilizia libera di cui alla L.R. n. 23/1985, art. 15, comma 7, pari a € 500.

Il costo delle regolarizzazioni amministrative si stima orientativamente intorno al 4% dell'attuale valore di mercato dell'appartamento e comprensive degli oneri professionali di un tecnico abilitato per la redazione della pratica edilizia, diritti istruttori a sanzione amministrativa. Pertanto, il valore di stima di questo immobile sarà ridotto della suddetta percentuale.

Eventuali maggiori costi si dovranno considerare compresi nella percentuale applicata per l'assenza di garanzia da vizi (es. impianti elettrici e idrici non a norma e da certificare, perdite d'acqua occulte, ecc. ecc.).

Il valore di stima dell'appartamento sarà cautelativamente ridotto di un ulteriore 2% forfettario per tenere conto dell'assenza di garanzia per vizi della cosa che caratterizza le vendite nelle aste giudiziarie.

Si sottolinea che la valutazione sopra esposta è riferita al momento in cui questa è stata eseguita, in quanto il continuo aggiornamento della normativa del settore, potrebbero creare modifiche dei parametri valutativi utilizzati.

Certificazioni energetiche e dichiarazioni di conformità

- Non esiste il certificato energetico dell'immobile / APE. La sottoscritta ha pertanto proceduto con la sua redazione (Allegato n. 5).
- Non esiste la dichiarazione di conformità dell'impianto elettrico.
- Non esiste la dichiarazione di conformità dell'impianto termico.
- Non esiste la dichiarazione di conformità dell'impianto idrico.

VINCOLI OD ONERI CONDOMINIALI

NON Sono presenti, oneri condominiali
SONO presenti vincoli paesaggistici,

Firmato Da: CARBONI MARIA GRAZIA Emesso Da: NAMIRIAL CA FIRMA QUALIFICATA Serial#: 2ac261897f278213

LOTTO 2

Il lotto è formato dai seguenti beni:

- **Bene 2** - Fabbricato artigianale ubicato a Sorso (SS) - Zona Artigianale Sant'Igliano N. Snc - Piano T
  Censito nel Catasto Fabbricati del Comune di Sorso al Foglio 56, particella 1233, sub 2, categoria C/3, classe 2, 210 mq, rendita 466,36 €

COMPLETEZZA DOCUMENTAZIONE EX ART. 567

In relazione al controllo della completezza della documentazione ex art. 567 si riferisce quanto segue. Il creditore procedente ha prodotto un Certificato notarile sostitutivo della certificazione storica ipotecaria e catastale a firma del Dott. Maurizio Lunetta, Notaio in San Giuseppe Jato, Nuoro (Pa). Tale Certificato, attesta le risultanze delle visure storiche catastali e dei registri immobiliari relative all'immobile pignorato fino al 24/10/2023.
Sono inoltre presenti l'atto di pignoramento e la relativa trascrizione
La suddetta certificazione è stata integrata dalla sottoscritta con le visure catastali e ipotecarie aggiornate, con la planimetria catastale dell'unità immobiliare, oltre che alla documentazione comunale.
La documentazione integrativa acquisita dalla sottoscritta si trova allegata alla presente perizia come Allegato n. 2 (documentazione catastale e ispezione ipotecaria) e, Allegato n. 3 (documentazione comunale).

Si attesta perciò che la documentazione di cui all'art. 567 c.p.c., comma 2 risulta completa.

TITOLARITÀ

I dati sulla titolarità, la provenienza ventennale, la cronistoria catastale e le formalità pregiudizievoli sono stati estratti dalla suddetta Certificazione notarile a cui si rinvia per controllo e per ogni ulteriore informazione non riversata in questa relazione.

Il bene pignorato non corrisponde a quello descritto nel titolo di provenienza (atto cessione mutuo) inquanto lo stesso è stato oggetto variazioni catastali successive eseguite per l'edificazione dell'immobile artigianale oggi presente. Si evidenzia che allo stato originario il bene oggetto di mutuo risultava essere definito da un "Lotto di area edificabile sito all'interno del comparto D13 del Piano Urbanistico Comunale, contrassegnato con il n. 9, della superficie complessiva di 1244 mq circa, distinto nel Catasto Terreni del Comune di Sorso al Foglio 56: Mappale 563, 559, 574. Il Mappale 559 unitamente ai Mappali 563 e 574 sono stati variati e unificati costituendo l'Ente Urbano distinto con il Mappale 1233 in cui attualmente sorgono le unità immobiliari distinte al Catasto Fabbricati con il Foglio 56, Mappale 1233 subalterni 1 e 2, oggetto di pignoramento

L'immobile oggetto dell'esecuzione appartiene ai seguenti esecutati:

- (Proprietà 1/1)
  Codice fiscale:

Il bene sopra indicato è pignorato **per intero** e viene posto in vendita per i seguenti diritti:

- (Proprietà 1/1)

CONSISTENZA

Destinazione	Superficie Lorda	Coefficiente	Superficie Convenzionale	Altezza	Piano
Locale attività	194,00 mq	1,00	194,00 mq	5,50 m	T

Firmato Da: CARBONI MARIA GRAZIA Emesso Da: NAMIRIAL CA FIRMA QUALIFICATA Serial#: 2ac261897f278213

Zona Ufficio	31,00 mq	1,00	31,00 mq	2,70 m	T
Area Esterna	384,00 mq	0,10	38,40 mq		
		Totale superficie convenzionale	**263,40 mq**		
		Totale superficie in C.T.	**263,00 mq**		

La misura della superficie convenzionale è arrotondata al metro quadrato e la sua valutazione del fabbricato viene effettuata sulla base della superficie commerciale lorda (comprensiva dei muri) corretta di un coefficiente detto "coefficiente di ragguaglio" così come riportato "nell'Allegato C del DPR 138 del 23 marzo 1998" e nelle "Norme UNI 10750:2005"

Il bene non è comodamente divisibile.

CRONISTORIA DATI CATASTALI

L'identificazione catastale dell'unità immobiliare risulta aver subito le variazioni sottoindicate relativamente all' identificativo e alla categoria catastale così come riportato nella visura storica (Allegato 2).

Periodo	Proprietà	Dati Catastali
Dal 10/12/2021 al 15/12/2021	) Proprietà 1/1	Catasto Fabbricati Fg. 56, Part. 1233 Categoria F/6
Dal 15/12/2021 all'attualità	) Proprietà 1/1	Catasto Fabbricati Fg. 56, Part. 1233, Sub. 1 Categoria C/3 Cl.2, Cons. 210 mq Rendita € 466,36 Piano T

DATI CATASTALI

Catasto fabbricati (CF)											
Dati identificativi				Dati di classamento							
Sezione	Foglio	Part.	Sub.	Zona Cens.	Categoria	Classe	Consistenza	Superficie catastale	Rendita	Piano	Graffato
	56	1233	2		C3	2	210 mq	262 mq	466,36 €	T	si

Corrispondenza catastale

NON Sussiste corrispondenza tra lo stato dei luoghi attuale e la planimetria catastale agli atti dell'Agenzia delle Entrate - Ufficio del Territorio di Sassari (Catasto).

Dal confronto tra lo stato rilevato e le planimetrie catastali in atti, si evidenzia la realizzazione di un soppalco precario in legno, con la creazione al piano terra del locale ufficio.

Le difformità sopra indicate all'interno dell'appartamento potranno essere regolarizzate mediante predisposizione di un atto di aggiornamento tramite procedura DOCFA presso l'Agenzia delle Entrate, per diversa distribuzione interna il cui costo si stima in € 500,00 tra oneri professionali e tributi speciali catastali (50,00 €).

Firmato Da: CARBONI MARIA GRAZIA Emesso Da: NAMIRIAL CA FIRMA QUALIFICATA Serial#: 2ac261897f278213

Tale variazione può essere eseguita solo previa presentazione della relativa pratica di accertamento di conformità da presentare presso l'Ufficio Tecnico del Comune di Sassari, per cui la sottoscritta ritiene di non poter procedere in questa perizia alla regolarizzazione catastale in quanto le trasformazioni operate dovrebbero essere prima sanate dal punto di vista edilizio-urbanistico.
Si è riscontrato, a seguito dell'esame della documentazione in atti e, dall'esito di verifiche effettuate dalla scrivente, sia presso gli uffici dell'Agenzia del Territorio che tramite sopralluoghi che, gli attuali dati identificativi dell'unità immobiliare (numeri di Foglio, Particella, Subalterno, consistenza) corrispondono a quelli riportati nell'atto di pignoramento.

STATO CONSERVATIVO

Dal sopralluogo compiuto si è potuto desumere che il complesso immobiliare appare in buone condizioni conservative e di manutenzione.
L'unità immobiliare oggetto di esecuzione si presenta in un buono stato di manutenzione.

PARTI COMUNI

Non sono presenti parti comuni.

STATO OCCUPAZIONE

Il bene oggetto del pignoramento risulta in piena proprietà del soggetto pignorato e, al momento del sopralluogo risulta occupato dallo stesso, per lo svolgimento della propria attività imprenditoriale. Nell'unità immobiliare sono presenti arredi e suppellettili che non rientrano tra i beni oggetto di questo pignoramento e che, pertanto, dovranno essere sgomberati a cura dei proprietari.

PROVENIENZE VENTENNALI

Per quanto riguarda l'immobile oggetto di pignoramento, sulla base dei dati reperiti dalla relazione notarile e, dalla visura ipotecaria storica reperita dalla sottoscritta, si evidenzia che:

- Sussiste continuità nelle trascrizioni per il ventennio precedente alla data di trascrizione del pignoramento;
- La situazione della proprietà antecedente il ventennio della trascrizione del pignoramento risulta variata;
- La situazione della proprietà risulta attualmente invariata.

FORMALITA' PREGIUDIZIEVOLI

A seguito dell'esecuzione dell'ispezione ipotecaria al fine di ottenere l'elenco aggiornato delle iscrizioni e trascrizioni a carico dei beni, si sono evidenziate le seguenti formalità riportate nell'Allegato 2 nel periodo di riferimento dal 19/10/1989 al 08/11/2024. (Ispezione n. T7294 del 10/11/2024)

TRASCRIZIONE del 23/10/2023 - ATTO ESECUTIVO O CAUTELARE - VERBALE DI PIGNORAMENTO IMMOBILI - Registro Particolare 13949 Registro Generale 18424 Pubblico ufficiale-UFFICIALE GIUDIZIARIO Repertorio 1983 del 22/09/2023
Nota disponibile in formato elettronico

Firmato Da: CARBONI MARIA GRAZIA Emesso Da: NAMIRIAL CA FIRMA QUALIFICATA Serial#: 2ac261897f278213

Si evidenzia così come richiesto dall'Avv.to Demontis si evidenzia che il terreno originario distinto col Mappale 559 è stato sostituito dal Mappale 1233, al quale sono stati uniti i Mappali 563 e 574, così costituendo l'Ente Urbano censito col Mappale 1233; quest'ultimo, attualmente, corrisponde con le 2 unità immobiliari distinte al CF al Foglio 56, Mappale 1233, sub. 1 e sub. 2, oggetto di pignoramento.
Sul terreno così come da note allagate e da relazione notarile risulta essere presente
TRASCRIZIONE del 03/11/2006 - IPOTECA VOLONTARIA Derivante da CONCESSIONE A GARANZIA DI MUTUO CONDIZIONATO - Registro Particolare 3525 Registro Generale 18950 Pubblico ufficiale – Notaio PORQUEDDU ANDREA Repertorio 4602/2564 del 02/11/2006

NORMATIVA URBANISTICA

L'immobile in oggetto ricade secondo il P.U.C vigente del Comune di Sorso in Zona D – Sottozona D2.1.13- Insediamenti produttivi e artigianali compatibili con la residenza esistenti realizzati a seguito di Piano Insediamenti Produttivi (P.I.P.) normati dagli art. 25 delle NTA allegato allo strumento vigente.
Ricade inoltre per i piani sovraordinati in:
- secondo il **PGRA-F** (Piano di Gestione Rischio Alluvioni-Frane) l'immobile oggetto di relazione ricade in: zona Hg0 - Aree per le quali non sono state individuati fenomeni franosi in atto o potenziali
- secondo il **P.P.R.** l'immobile in oggetto ricade: nell'Ambito di Paesaggio 14 – Golfo dell'Asinara normate dagli art. 6, 12, 13, 14, 15, 107 e 112 delle NTA allegate al PPR vigente all'interno delle zone Tutelata - Beni Paesaggistici Ambientali (ex. Art. 143 D.Lgs. 42/2004 – Fascia Costiera normati dagli art. 8, 17, 18, 19, 20 delle NTA allegate al PPR

REGOLARITÀ EDILIZIA

In merito alla regolarità dell'immobile, si relaziona quanto segue: (vedi Allegato 4).
A seguito di richiesta di accesso agli atti presso il Comune di Sorso (Prot.N. 23671 del 23/07/2024l 10/06/2024) si evidenzia che lo stabile in cui insite l'immobile oggetto di procedura è stato edificato mediante le seguenti concessioni:

- Concessione edilizia n. 70 del 29 giugno 2004 rilasciata alla Ditta per la costruzione di un "Capannone da destinare ad attività artigianale per deposito di materiale edili nell'area P.I.P. lotto n. 9 – Comparto di Lottizzazione D13 in Località Prunosa"
- Concessione edilizia in rinnovo n. 13 del 07 febbraio 2006;
- Concessione edilizia in variante n. 51 del 20 giugno 2007;
- SCIA in Sanatoria Concessione -27052021-1028.320538 prot. N. 15694/323 del 03/06/2021 rilasciata alla Ditta per Scia in Sanatoria Per Variante In Corso D'opera Riguardante I Lavori Effettuati Nel Periodo Di Vigenza Del Titolo Abilitativo E Che Hanno Portato Ad Una Diversa Distribuzione Interna Degli Ambienti E La Modifica Di Prospetto Nel Capannone Artigianale In Sorso Area P.I.P. - Lotto N.9;
- Provvedimento unico n. 97 del 15/07/2021 rilasciato alla Ditta per Ristrutturazione Edilizia Per La Suddivisione Di Un Capannone Artigianale Da Una A Due Unità In Sorso Area P.I.P. - Lotto N.9 -

Si evidenzia altresì la presenza Dichiarazione di agibilità presentata con prot. N. 37695/780 del 30/12/2021

Confronto tra stato attuale e progetto autorizzato - difformità

Firmato Da: CARBONI MARIA GRAZIA Emesso Da: NAMIRIAL CA FIRMA QUALIFICATA Serial#: 2ac261897f278213

Dal confronto tra gli elaborati grafici reperiti nel Provvedimento unico n. 97 del 15/07/2021 e lo stato reale, si evidenzia la presenza di difformità relative alla realizzazione di un locale ufficio ottenuto mediante la realizzazione di un soppalco precario in legno.

Si evidenzia altresì la presenza di un lieve difformità relativa all'altezza interna dei locali pari a 5,50 m, contro i 5,00 m indicati progettualmente.

Sanabilità

Si premette innanzi tutto che la sottoscritta non può pronunciarsi in modo definitivo in sostituzione degli Enti pubblici preposti a decidere sulle istanze di sanatoria dei privati con giudizi connotati da discrezionalità tecnico valutativa solo ad essi riservata e che può portare a diversi esiti. Può solo fornire un parere formato sulla base di orientamenti informali espressi dagli Uffici competenti che non esprimono valutazioni conclusive in assenza di un formale deposito di un progetto da istruire. Pertanto, tenendo conto di questo limite, all'esito dei colloqui avuti con gli uffici competenti si può riferire quanto di seguito.

Quanto alla possibilità di richiedere e ottenere una sanatoria ai sensi dell'art. 36 del T.U. dell'edilizia (DPR 380/2001) e dell'art. 16 della L. R. 23/85,tenendo in considerazione che le modiche delle disposizioni interne rilevate nell'unita unità immobiliare, sono definite ai sensi dell'art. 15 comma 2 punto b della LR 23/85 individuati al punto 351.k dell'Allegato B alla DGR 49/19 del 05/12/2019, interventi di manutenzione straordinaria che non riguardino le parti strutturali dell'edificio, *inquanto opere o modifiche necessarie per rinnovare e sostituire parti anche strutturali degli edifici, nonché per realizzare ed integrare i servizi igienico-sanitari e tecnologici, sempre che non alterino la volumetria complessiva degli edifici e non comportino mutamenti urbanisticamente rilevanti delle destinazioni d'uso implicanti incremento del carico urbanistico. …… Nell'ambito degli interventi di manutenzione straordinaria sono ricompresi anche quelli consistenti nel frazionamento o accorpamento delle unità immobiliari con esecuzione di opere anche se comportanti la variazione delle superfici delle singole unità immobiliari nonché del carico urbanistico purché non sia modificata la volumetria complessiva degli edifici e si mantenga l'originaria destinazione d'uso. Nell'ambito degli interventi di manutenzione straordinaria sono comprese anche le modifiche ai prospetti degli edifici legittimamente realizzati necessarie per mantenere o acquisire l'agibilità dell'edificio ovvero per l'accesso allo stesso, che non pregiudichino il decoro architettonico dell'edificio, purché l'intervento risulti conforme alla vigente disciplina urbanistica ed edilizia e non abbia ad oggetto immobili sottoposti a tutela* cosi come indicato nell'art. 3 Dpr 380/2001; sulla disposizioni dell'art 16 comma a dell'Allegato A alla DGR 49/19 del 05/12/2019, gli interventi oggetto di accertamento, ricadono nell'ambito delle "sanatorie" che si perfezionano attraverso la trasmissione di una dichiarazione autocertificativa ed il versamento di una sanzione ad effetto sanante di importo predeterminato per la mancata comunicazione di edilizia libera di cui alla L.R. n. 23/1985, art. 15, comma 7, pari a € 500.

Il costo delle regolarizzazioni amministrative si stima orientativamente intorno al 4% dell'attuale valore di mercato dell'appartamento e comprensive degli oneri professionali di un tecnico abilitato per la redazione della pratica edilizia, diritti istruttori a sanzione amministrativa. Pertanto, il valore di stima di questo immobile sarà ridotto della suddetta percentuale.

Eventuali maggiori costi si dovranno considerare compresi nella percentuale applicata per l'assenza di garanzia da vizi (es. impianti elettrici e idrici non a norma e da certificare, perdite d'acqua occulte, ecc. ecc.).

Il valore di stima dell'appartamento sarà cautelativamente ridotto di un ulteriore 2% forfettario per tenere conto dell'assenza di garanzia per vizi della cosa che caratterizza le vendite nelle aste giudiziarie.

Si sottolinea che la valutazione sopra esposta è riferita al momento in cui questa è stata eseguita, in quanto il continuo aggiornamento della normativa del settore, potrebbero creare modifiche dei parametri valutativi utilizzati.

Firmato Da: CARBONI MARIA GRAZIA Emesso Da: NAMIRIAL CA FIRMA QUALIFICATA Serial#: 2ac261897f278213

Certificazioni energetiche e dichiarazioni di conformità

- Non esiste il certificato energetico dell'immobile / APE. La sottoscritta ha pertanto proceduto con la sua redazione (Allegato n. 5).
- Non esiste la dichiarazione di conformità dell'impianto elettrico.
- Non esiste la dichiarazione di conformità dell'impianto termico.
- Non esiste la dichiarazione di conformità dell'impianto idrico.

VINCOLI OD ONERI CONDOMINIALI

NON SONO presenti, oneri condominiali.
SONO presenti vincoli paesaggistici,

Firmato Da: CARBONI MARIA GRAZIA Emesso Da: NAMIRIAL CA FIRMA QUALIFICATA Serial#: 2ac261897f278213

STIMA / FORMAZIONE LOTTI

Il valore commerciale dei beni pignorati è stato determinato sulla base delle seguenti variabili: ubicazione dell'immobile, caratteristiche e peculiarità della zona oltre che dalla facilità di raggiungimento, stato di manutenzione, conservazione, finitura e confort, consistenza, regolarità geometrica della forma, sussistenza di eventuali vincoli e servitù passive o attive, suoi dati metrici ed infine la situazione del mercato e della domanda e dell'offerta. Tutti questi elementi, in coesistenza all'esame di alcune documentazioni ufficiali ed esperita un'attenta e puntuale ricerca volta a determinare l'attuale valore di mercato indicando sia il valore per metro quadro che il valore complessivo, tenendo conto altresì di eventuali adeguamenti e correzioni della stima, hanno concorso a determinare il più probabile valore di compravendita da attribuire agli immobili oggetto della stima.

ASPETTI ECONOMICI E PROCEDIMENTI ESTIMATIVI - GENERALITÀ

Scopo della stima è quello di determinare il "valore venale" in un comune commercio. Per "valore venale", termine giuridico equivalente al "più probabile valore di mercato", si intende quel valore che avrebbe la maggior probabilità tra quelli possibili, di segnare il punto d'incontro tra domanda e offerta, in una libera contrattazione tra una pluralità di operatori economici di un dato mercato.

Allo stato attuale non è possibile applicare la metodologia MCA (Market Comparison Approach) basata su reali compravendite, in quanto, nonostante indagini di mercato, consultazioni di intermediari immobiliari, non è stato possibile reperire, nelle zone in esame, gli atti di vendita delle unità immobiliari oggetto di compravendita, da cui reperire oltre ai prezzi di vendita e la superficie catastale, tutte le altre caratteristiche intrinseche di ogni singolo immobile necessarie per la definizione dei parametri necessari all'applicazione della metodologia sopra indicata.

Per quanto sopra esposto, il procedimento di stima adottato nella valutazione del valore di mercato dell'immobile, vista la destinazione speciale dell'immobile, tenendo conto altresì che generalmente il mercato degli edifici industriali e artigianali è caratterizzato da un numero esiguo di transazioni, che rende non praticabile l'applicazione del metodo della comparazione per la stima del loro valore, si ritiene opportuno adottare il metodo di stima del "**Cost Approach"** detto anche metodo del "costo di ricostruzione deprezzato", un procedimento di stima mirato a determinare il valore di un immobile attraverso la somma del valore del suolo e del costo di ricostruzione dell'edificio, eventualmente deprezzato

Tale metodo si fonda sul principio che, nella maggior parte dei casi, un investitore non sarà disposto a pagare per un immobile una somma superiore al valore del terreno sul quale l'immobile è costruito e al costo di costruzione dell'edificio, al netto di un eventuale deprezzamento.

In altri termini, l'acquirente potenziale opterà tra l'acquisto di un immobile esistente e la costruzione di un edificio con le stesse caratteristiche su un terreno simile, tenendo conto del grado di deprezzamento del bene esistente. Il valore di ricostruzione verrà valutato sulla base delle indicazioni contenute nella circolare 6/2012 dell'Agenzia delle Entrate, in cui si dovrà dapprima calcolare il costo di costruzione totale, sommando:

- il costo di costruzione delle singole parti del complesso analizzato - le spese tecniche necessarie, - gli oneri comunali da versare. Andrà quindi calcolato il valore dell'area (come percentuale del costo di costruzione o a metro quadro) e successivamente l'utile promotore. Sommando i tre valori (costo di costruzione, valore dell'area ed utile promotore) avremo il valore a nuovo, cui andrà sottratto il deprezzamento per vetustà e obsolescenza tecnologica che potrà essere calcolato con la funzione lineare oppure applicando la formula proposta dall'U.E.C. (Union Européenne des Expert Comptables Economiques et Financiers) ed ulteriori eventuali detrazioni dovute alle spese per la regolarizzazione edilizia e/o catastale e per interventi edilizi di manutenzione straordinaria atti a riportare l'immobile a condizioni di ordinarietà. Il tutto verrà eseguito valutando la costruzione in assenza di finanziamento e/o prestito bancario e quindi di fatto senza la definizione degli oneri finanziari derivanti

Firmato Da: CARBONI MARIA GRAZIA Emesso Da: NAMIRIAL CA FIRMA QUALIFICATA Serial#: 2ac261897f278213

Il risultato della stima è da intendersi rigorosamente riferito e limitato alla data in cui sono state effettuate le relative indagini e, in quanto valore previsionale medio ordinario, può discostarsi dal prezzo conseguente ad una eventuale effettiva compravendita dipendente da fattori soggettivi e dalla capacità contrattuale dei contraenti. Per quanto sopra esposto tale valore potrà variare del cosiddetto "margine di trattativa", in genere compreso tra il 5% ed il 15% del prezzo di vendita offerto.

Fase applicativa

VALUTAZIONE DEL PIÙ PROBABILE VALORE DI MERCATO

Sulla base di quanto recentemente indicato, si procede con l'applicazione della formula per il calcolo del valore di mercato tramite il costo di costruzione in cui il valore di mercato si ottiene:

Valore Ricostruzione = Vc+ Oneri+ U.P. CC+ V. Area+ U.P. VA -V dep. – S.r. -Sm

Dove:

Vc = valore di Costo per la realizzazione delle opere

Oneri = oneri legati a spese tecniche, oneri comunali ect…

U.P.CC = Utile del promotore sul costo di costruzione

V. Area = Valore Area di sedime

U.P.VA = Utile del promotore sul valore dell'area

V. dep.= Valore di deprezzamento ottenuto dal prodotto del valore di costo comprensivo di oneri e il coefficiente di deprezzamento per vetustà è collegato alla durata di vita utile dell'edificio e può calcolarsi con la formula di origine sperimentale dell'Unione Europea degli Esperti contabili (U.E.E.C.) $D = [(As+20)^2 / 140] – 2,86$, dove **D** rappresenta il deprezzamento in percentuale del valore a nuovo mentre **As** esprime il rapporto in percentuale tra gli anni di vita dell'edificio e la sua vita utile.

S.r. = Spese di regolarizzazione

S.m . Spese di manutenzione

Si procede alle determinazioni dei singoli valori dell'equazione

Valore di Costo di riproduzione

Per la determinazione del costo di riproduzione ottenuto tramite il prodotto della somma dei singoli prodotti delle superfici lorde di pavimento individuate per piano e destinazione d'uso, per il costo di costruzione unitario di ciascuna di esse. I costi unitari sono stati dedotti dalla vigente letteratura tecnica in materia, vedasi in particolare il P*rezzario di massima unità immobiliari urbane a destinazione speciale e particolare - Elementi di riferimento per le stime secondo il criterio a valore di costo di ricostruzione deprezzato dell'Agenzia delle Entrate*, o dal *Prontuario delle Tipologie Edilizie 2024 del DEI.*

Visto che la valutazione della superficie convenzionale/commerciale complessiva, è stata valutata come la sommatoria delle singole superfici ragguagliate ottenute rapportando mediante dei coefficienti di ragguaglio, le singole superfici delle pertinenze alla superfice principale dell'attività, si ritiene corretto valutare il costo di costruzione relativo all'area di attività, ottenuta dalla media dei valori ricavati dalla letteratura sopra e di seguito schematizzata: Prezziario Dei 2024 per "(capannone classe 500 con copertura piana" in cui si rileva un di valore di **€/mq 637,00**.

Determinazione Oneri indiretti

Si osserva che gli oneri indiretti così come indicato nelle note allegate a prezziario di massima su addetto, sono comprese nel valore sopra riportato e per tale motivo non vengono calcolate.

Determinazione Utile del promotore sul costo di costruzione

Si osserva che gli oneri indiretti così come indicato nelle note allegate a prezziario di riferimento, sono comprese nel valore sopra riportato e per tale motivo non vengono calcolate.

Determinazione Valore dell'Area

Firmato Da: CARBONI MARIA GRAZIA Emesso Da: NAMIRIAL CA FIRMA QUALIFICATA Serial#: 2ac261897f278213

Nel caso in specie, la determinazione di tale ultimo valore riveste particolare carattere di aleatorietà, considerato che la potenzialità edificatoria delle suddette aree (che ne determina in buona parte il relativo valore) è determinata proprio dalla preesistenza dei fabbricati in esame, senza i quali la stessa sarebbe assolutamente ridotta. Si aggiunga per altro che non risultano di facile acquisizione dati economici relativi a transazioni recenti di aree edificabili di analoga destinazione che permetterebbero l'utilizzo del metodo della comparazione diretta per la determinazione del valore dell'area su cui insistono gli immobili oggetto di stima. Per ovviare a tale inconveniente, si è fatto ricorso ad una metodologia analitica sostitutiva, che fornirà un dato approssimativo, ma scientificamente sostenibile da adottare in questa sede valutativa. Il valore del sedime edificabile viene quindi valutato con il metodo sintetico di trasformazione denominato metodo dell'incidenza d'area secondo la relazione VAREA = (Crip x I.A.) / (1 – I.A.) Dove: Crip = Costo di Riproduzione a nuovo; I.A. = Coefficiente di incidenza d'area.

Stante la destinazione produttiva degli immobili in oggetto si ritiene opportuno considerare un coefficiente I.A. non inferiore al 12% così come indicato nella circolare dell'Agenzia delle Entrate sopra citata, si ottiene un valore pari a **€/mq 86,86**

Determinazione Utile del promotore sul valore dell'area

L'utile del promotore sarà valutato in percentuale sul valore di riproduzione a nuovo, relativo alla sola quota parte derivante dai costi diretti ed indiretti relativi al fabbricato nella misura del 10% pari a €**/mq 8,69**

Determinazione Valore deprezzamento

Considerando che la vita utile del fabbricato può essere considerata in 50 anni e, che tenendo conto dell'anno di costruzione del complesso originario individuabile nel 2007, si è considerata un'età effettiva del fabbricato pari a 4 anni da inserire nella già citata formula per il calcolo del coefficiente di deprezzamento dell'immobile e conseguentemente del costo globale di riproduzione, pari al 10,00%

Si evidenzia che la percentuale di deprezzamento sopra determinata deve essere applicata, nel valore di riproduzione a nuovo, alla sola quota parte derivante dai costi diretti ed indiretti relativi al fabbricato e non a quelli relativi all'area, con un Valore di deprezzamento pari a **€/mq 20,34**

Determinazione costi di regolarizzazione

Il cui valore verrà valutato in sede di stima

Determinazione costi manutenzione

Così come già riportato precedentemente si evidenzia che è necessario eseguire una valutazione in merito agli interventi edilizi di manutenzione straordinaria atti a riportare l'immobile a condizioni di ordinarietà.

Sulla base di quanto sopra esposto si ottiene un valore di ricostruzione in **CT di €/mq 669,00.**

Tanto rilevato, considerato che:

- Gli immobili in esame si trova in buono stato di manutenzione e conservazione;
- Gli immobili dovranno essere oggetto di regolarizzazioni edilizie, i cui costi potrebbero avere una incidenza di circa il 4% e 10% dell'attuale valore dell'immobile;
- la vendita avverrà senza garanzie per vizi della cosa, ragion per cui si ritiene opportuno applicare una riduzione forfettaria del valore che si ritiene congruo quantificare nel 2% dell'importo stimato;

Lo scrivente ha ritenuto opportuno procedere alla formazione dei seguenti lotti:

Firmato Da: CARBONI MARIA GRAZIA Emesso Da: NAMIRIAL CA FIRMA QUALIFICATA Serial#: 2ac261897f278213

LOTTO 1

Bene N° 1 - Fabbricato artigianale ubicato a Sorso (SS) - Zona Artigianale Sant'Igliano N. Snc
Identificato al catasto Fabbricati - Foglio 56, particella 1233, sub 1, categoria C/3
L'immobile viene posto in vendita per il diritto di Proprietà (1/1)
Valore di stima del bene: **€ 174.190,00**

Identificativo corpo	Superficie convenzionale	Valore unitario	Valore complessivo	Quota in vendita	Totale
Lotto 1 - Fabbricato artigianale ubicato a Sorso (SS) - Zona Artigianale Sant'Igliano N. Snc – Piano T	277,00 mq	699,00€/mq	€ 185.313,00	100%	€ 185.313,00
Valore di stima:					€ 185.313,00
A dedurre costi di regolarizzazione edilizia e catastale (- 4%)					-€ 7.413,00
A dedurre riduzione di valore per assenza di garanzia per vizi della cosa (- 2 %)					-€ 3.706,00
Più probabile valore di mercato al netto delle riduzioni					€ 174.194,00
arrotondamento					-€ 4,00
Più probabile valore di mercato arrotondato					**174.190,00 €**

LOTTO 2

Bene N° 2 - Fabbricato artigianale ubicato a Sorso (SS) - Zona Artigianale Sant'Igliano N. Snc
Identificato al catasto Fabbricati - Foglio 56, particella 1233, sub 1, categoria C/3
L'immobile viene posto in vendita per il diritto di Proprietà (1/1)
Valore di stima del bene: **165.390,00 €**

Identificativo corpo	Superficie convenzionale	Valore unitario	Valore complessivo	Quota in vendita	Totale
Lotto 2 - Fabbricato artigianale ubicato a Sorso (SS) - Zona Artigianale Sant'Igliano N. Snc – Piano T	263,00 mq	699,00€/mq	€ 175.947,00	100%	€ 175.947,00
Valore di stima:					€ 175.947,00
A dedurre costi di regolarizzazione edilizia e catastale (- 4%)					-€ 7.038,00
A dedurre riduzione di valore per assenza di garanzia per vizi della cosa (- 2 %)					-€ 3.519,00
Più probabile valore di mercato al netto delle riduzioni					€ 165.390,00
arrotondamento					€ -
Più probabile valore di mercato arrotondato					**165.390,00 €**

Per un valore totale del compendio pignorato così schematizzato:
Lotto 1 valore pari a € 174.190,00
Lotto 2 valore pari a € 165.390,00
Valore Totale pari a € 339.580,00 €
Assolto il proprio mandato, il sottoscritto Esperto ex art. 568 c.p.c. deposita la relazione di stima presso questo Spettabile Tribunale, tanto in assolvimento dell'incarico conferitogli dalla S.V. e resta a disposizione per eventuali chiarimenti.

Sassari, li 12/11/2024

L'Esperto ex art. 568 c.p.c.
Dott.ssa Carboni Maria Grazia
(CTU ed ESPERTO STIMATORE QUALIFICATO)

Firmato Da: CARBONI MARIA GRAZIA Emesso Da: NAMIRIAL CA FIRMA QUALIFICATA Serial#: 2ac261897f278213

ELENCO ALLEGATI:

- ✓ N° 1 Doc. Fotografica
- ✓ N° 2 Doc. Catastale e Ispezione Ipotecaria
- ✓ N° 3 Doc. Comunale
- ✓ N° 4 Elaborati Grafici
- ✓ N° 5 Attestato Prestazione Energetica (APE)

Firmato Da: CARBONI MARIA GRAZIA Emesso Da: NAMIRIAL CA FIRMA QUALIFICATA Serial#: 2ac261897f278213

RIEPILOGO BANDO D'ASTA

LOTTO 1

- **Bene N° 1** - Fabbricato artigianale ubicato a Sorso (SS) - Zona Artigianale Sant'Igliano N. Snc - Piano T
- Identificato al catasto Fabbricati - Foglio 56, particella 1233, sub 1, categoria C/3
  L'unità ad uso artigianale è ubicata al piano terra di un immobile che si sviluppa su n° 1 piani fuori terra e, da patio esterno di proprietà esclusiva. Dalla strada principale, si accede per mezzo di cancello carraio, al patio di pertinenza della proprietà; percorrendo tale patio si può accedere al locale ufficio nel lato sinistro dell'immobile e tramite portellone frontale direttamente al locale attività: L'unità immobiliare è composta da: locale attività uffici con annessi servizi, locale deposito al piano primo (sopra locale uffici) e patio esterno.
- L'immobile viene posto in vendita per il diritto di Proprietà (1/1)

LOTTO 2

- **Bene N° 2** - Fabbricato artigianale ubicato a Sorso (SS) - Zona Artigianale Sant'Igliano N. Snc - Piano T
- Identificato al catasto Fabbricati - Foglio 56, particella 1233, sub 1, categoria C/3
  L'unità ad uso artigianale è ubicata al piano terra di un immobile che si sviluppa su n° 1 piani fuori terra e, da patio esterno di proprietà esclusiva. Dalla strada principale, si accede per mezzo di cancello carraio e rampa, al patio di pertinenza della proprietà; percorrendo tale patio si può accedere tramite portellone frontale direttamente al locale attività. L'unità immobiliare è composta da: locale attività ufficio costituito da struttura precaria (soppalco) e patio esterno.
- L'immobile viene posto in vendita per il diritto di Proprietà (1/1)

Firmato Da: CARBONI MARIA GRAZIA Emesso Da: NAMIRIAL CA FIRMA QUALIFICATA Serial#: 2ac261897f278213

SCHEMA RIASSUNTIVO
ESECUZIONE IMMOBILIARE 124/2023 DEL R.G.E.

LOTTO 1

Bene N° 1 – Fabbricato artigianale			
Ubicazione:	Sorso (SS) - Zona Artigianale Sant'Igliano N. Snc		
Diritto reale:	Proprietà	**Quota**	1/1
Tipologia immobile:	Locale Artigianale Identificato al catasto Fabbricati - Foglio 56, particella 1233, sub 1, categoria C/3	**Superficie**	277,00 mq
Stato conservativo:	Dal sopralluogo compiuto si è potuto desumere che il complesso immobiliare appare in buone condizioni conservative e di manutenzione. L'unità immobiliare oggetto di esecuzione si presenta in un buono stato di manutenzione		
Descrizione:	L'unità ad uso artigianale è ubicata al piano terra di un immobile che si sviluppa su n° 1 piani fuori terra e, da patio esterno di proprietà esclusiva. Dalla strada principale, si accede per mezzo di cancello carraio, al patio di pertinenza della proprietà; percorrendo tale patio si può accedere al locale ufficio nel lato sinistro dell'immobile e tramite portellone frontale direttamente al locale attività: L'unità immobiliare è composta da: locale attività uffici con annessi servizi, locale deposito al piano primo (sopra locale uffici) e patio esterno.		
Vendita soggetta a IVA:	N.D		
Continuità trascrizioni ex art. 2650 c.c.:	SI		

LOTTO 2

Bene N° 2 – Fabbricato artigianale			
Ubicazione:	Sorso (SS) - Zona Artigianale Sant'Igliano N. Snc		
Diritto reale:	Proprietà	**Quota**	1/1
Tipologia immobile:	Locale Artigianale Identificato al catasto Fabbricati - Foglio 56, particella 1233, sub 2, categoria C/3	**Superficie**	263,00 mq
Stato conservativo:	Dal sopralluogo compiuto si è potuto desumere che il complesso immobiliare appare in buone condizioni conservative e di manutenzione. L'unità immobiliare oggetto di esecuzione si presenta in un buono stato di manutenzione.		
Descrizione:	L'unità ad uso artigianale è ubicata al piano terra di un immobile che si sviluppa su n° 1 piani fuori terra e, da patio esterno di proprietà esclusiva. Dalla strada principale, si accede per mezzo di cancello carraio e rampa, al patio di pertinenza della proprietà; percorrendo tale patio si può accedere tramite portellone frontale direttamente al locale attività. L'unità immobiliare è composta da: locale attività ufficio costituito da struttura precaria (soppalco) e patio esterno.		
Vendita soggetta a IVA:	N.D		
Continuità trascrizioni ex art. 2650 c.c.:	SI		

Firmato Da: CARBONI MARIA GRAZIA Emesso Da: NAMIRIAL CA FIRMA QUALIFICATA Serial#: 2ac261897f278213

RISPOSTA ALLE OSSERVAZIONI DELLE PARTI ALLA CONSULENZA TECNICA DEL CTU

PREMESSA

La sottoscritta Dott.ssa Carboni Maria Grazia, libero professionista regolarmente iscritta all'Ordine dei Dottori Agronomi e Forestali della Provincia di Sassari con n. 786 ed a quello dei Consulenti Tecnici del Tribunale di Sassari, a seguito di disposizioni del G.E., contenute nel verbale di udienza ha inviato alle parti per via telematica in data 14/11/2024, la relazione tecnica e i relativi allegati, al fine di poter presentare, nel termine di 15 giorni, le relative osservazioni.

CONSIDERAZIONI

A seguito della perizia trasmessa, pervenivano alla sottoscritta in data 30/11/2024, le osservazioni delle parti, delle quali lette attentamente si evidenzia quanto segue:

PARTE ATTRICE – AVV.TO DEMONTIS SARA

Nelle osservazioni l'avv.to Demontis legale di parte attrice, indica quanto segue:
"riscontro la Sua cortese relativa alla procedura in oggetto e, in nome e per conto del creditore procedente Organa SPV Srl, comunico di non avere particolari osservazioni da avanzare alla bozza della perizia trasmessami.
Segnalo però che nell'elenco delle formalità pregiudizievoli viene riportato unicamente il pignoramento; in realtà, come indicato nel certificato notarile in atti, i cespiti sono gravati dall'ipoteca di 1° grado in favore della banca mutuante (allora Banca di Credito Sardo Spa, poi incorporata in Intesa SanPaolo Spa e, quest'ultima, banca cedente il credito oggi vantato dalla Organa SPV Srl).
Infatti, l'ipoteca iscritta sull'area si estende ai miglioramenti, alle addizioni e alle altre costruzioni ex art. 2811 CC (allego per pronto reperimento le note di iscrizione).
Se possibile, Le sarei quindi grata se potesse integrare il dato, inserendo le formalità già evidenziate nella certificazione, specificando, in particolare, che il terreno distinto col Mappale 559 è stato sostituito dal Mappale 1233, al quale sono stati uniti i Mappali 563 e 574, così costituendo l'Ente Urbano censito col Mappale 1233; quat'ultimo, attualmente, corrisponde con le 2 unità immobiliari distinte al CF al Foglio 56, Mappale 1233, sub. 1 e sub. 2, oggetto di pignoramento"

Sulla base delle osservazioni dell'avv.to Demontis, la sottoscritta valutati gli atti presentati, prosegue con le integrazioni delle note, che saranno ripotate nella perizia predisposte conferma in ogni sua parte la relazione.

Sassari, li 02/12/2024

L'Esperto ex art. 568 c.p.c.
Dott.ssa Carboni Maria Grazia
(CTU ed ESPERTO STIMATORE QUALIFICATO)

Firmato Da: CARBONI MARIA GRAZIA Emesso Da: NAMIRIAL CA FIRMA QUALIFICATA Serial#: 2ac261897f278213

Stato Catastale

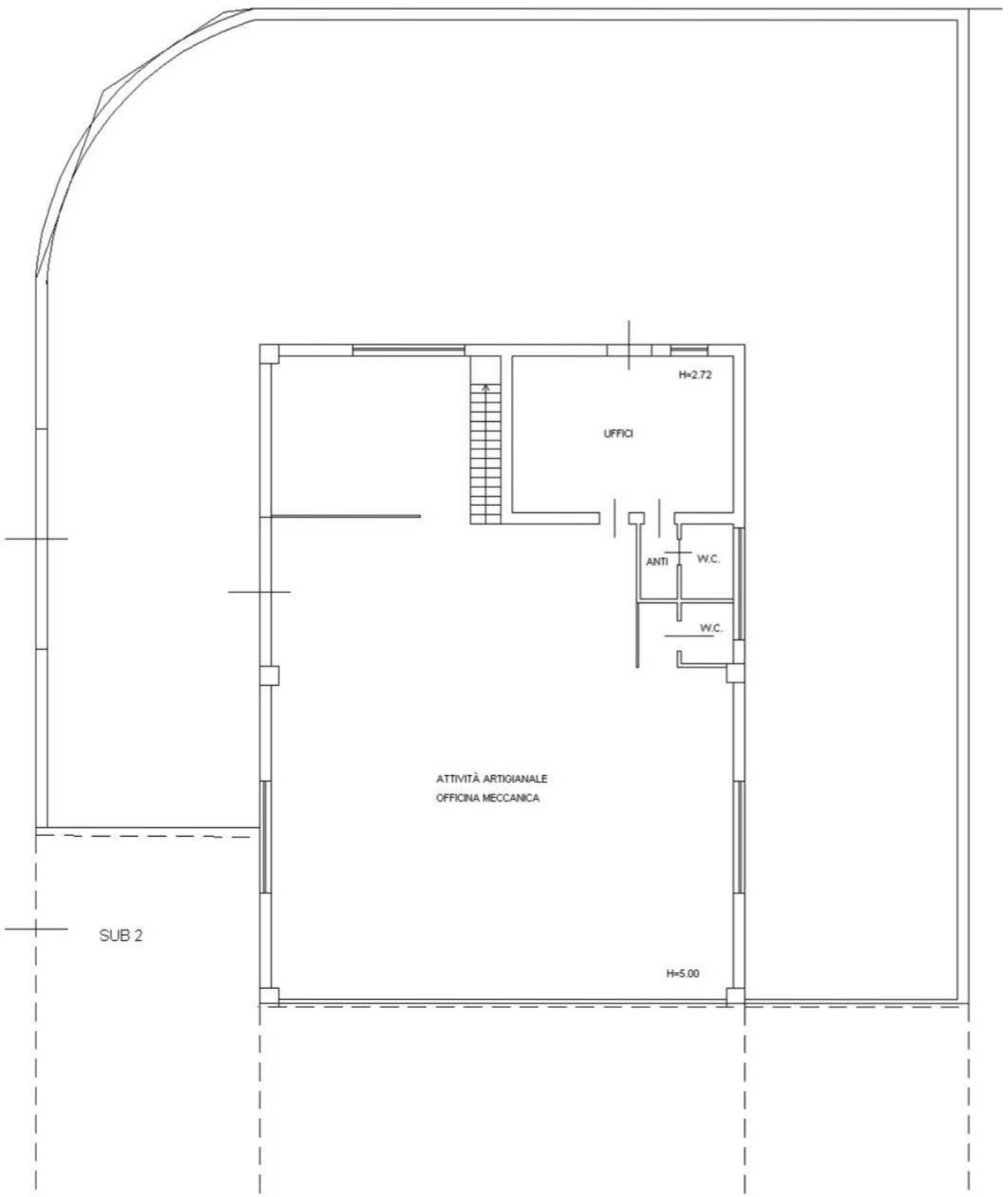

Altezza rilevata 5,50 non 5,00 come da indicazioni planimetria catasto

Stato Rilevato

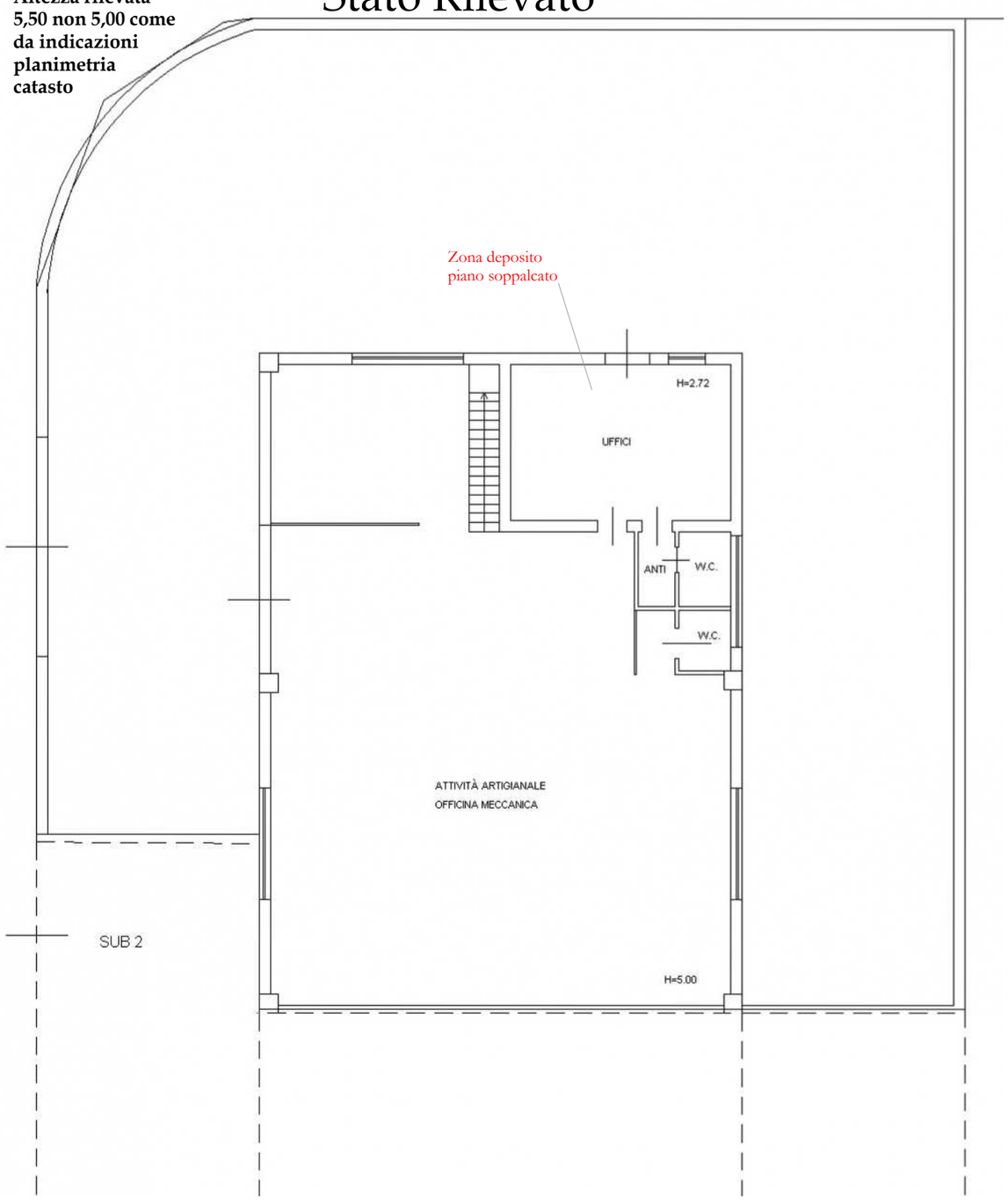

TAV. 4	**Tribunale Ordinario di Sassari** **Es. Imm. R.G. 124/2023**	**VERIFICA** **CONFORMITÀ CATASTALE**	***LOTTO 1*** Fg 56 Mapp. 1233 Sub 1

Firmato Da: CARBONI MARIA GRAZIA Emesso Da: NAMIRIAL CA FIRMA QUALIFICATA Serial#: 2ac261897f278213

Stato Assentito

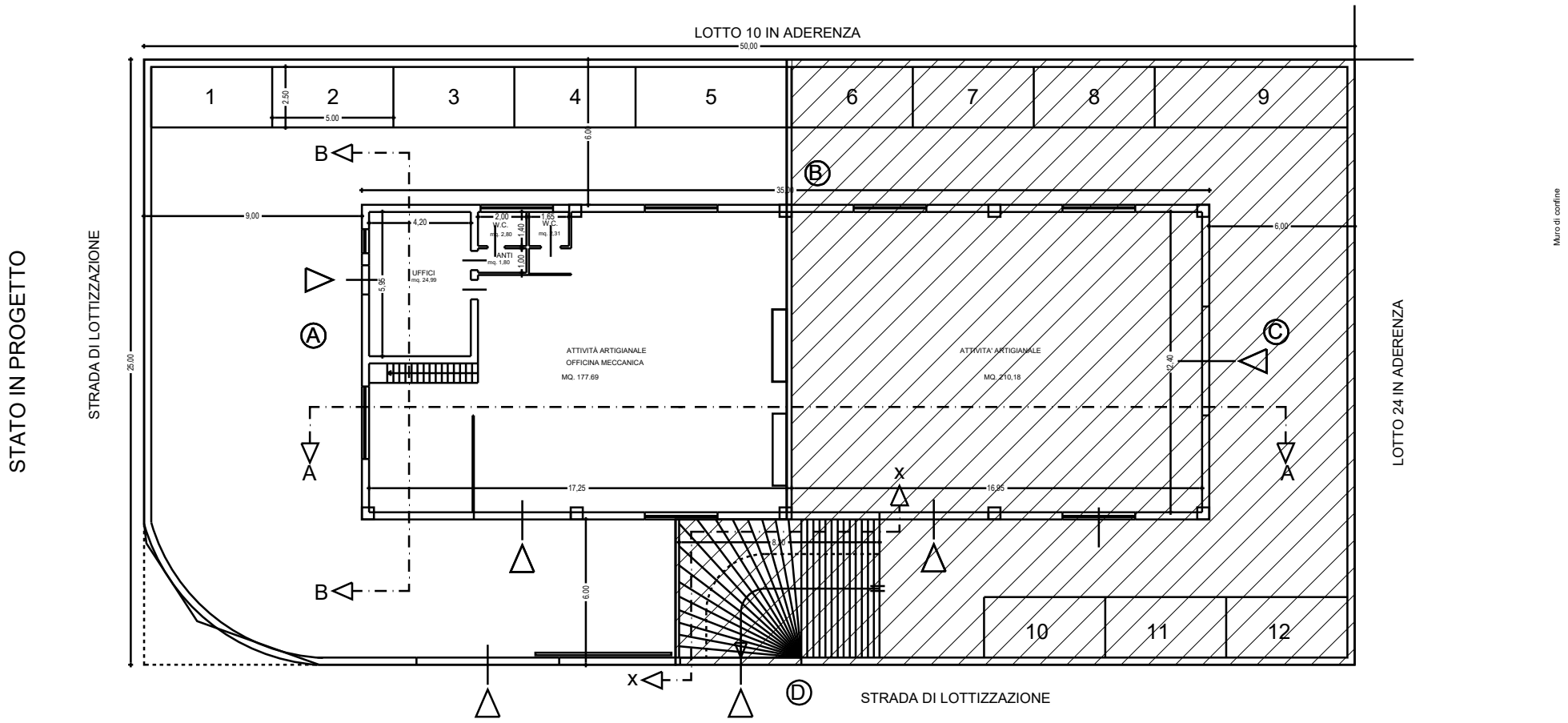

PIANTA

Stato Rilevato

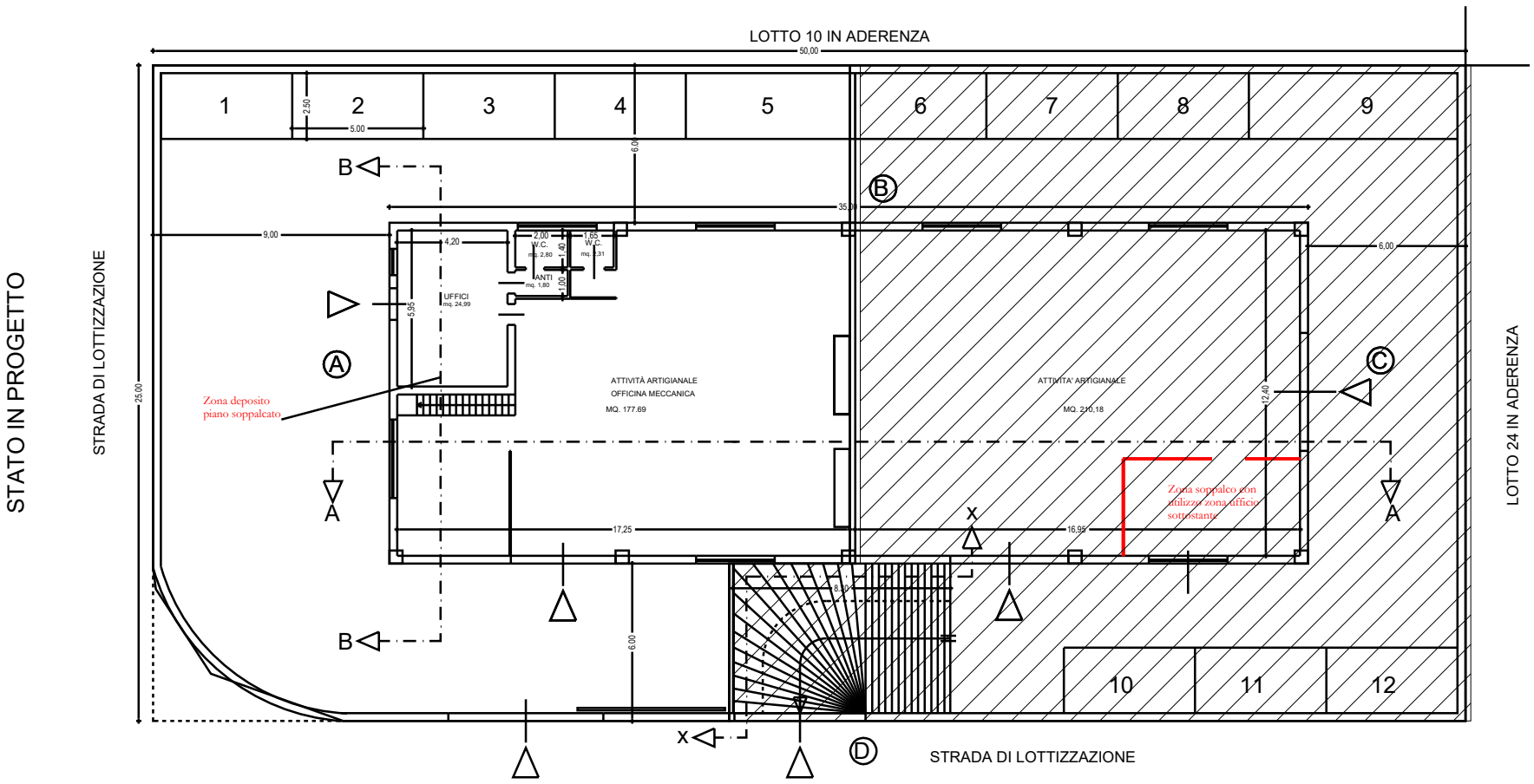

PIANTA

TAV. 4 A **CONFORMITÀ EDILZIA**	**Tribunale Ordinario di Sassari** **Causa Civile R.G. 124/2023**	***LOTTO 1*** Fg 56 Mapp. 1233 Sub 1

Firmato Da: CARBONI MARIA GRAZIA Emesso Da: NAMIRIAL CA FIRMA QUALIFICATA Serial#: 2ac261897f278213

LOTTO 1

FOTO 1- Accesso laterale ufficio

FOTO 2- Accesso locale attività

FOTO 3- Cancello ingresso

Firmato Da: CARBONI MARIA GRAZIA Emesso Da: NAMIRIAL CA FIRMA QUALIFICATA Serial#: 2ac261897f278213

ATTESTATO DI PRESTAZIONE ENERGETICA

Area geografica

Regione **Sardegna**

Provincia di **Sassari**

Comune di **SORSO**

Ubicazione intervento

Zona Artigianale Sant'Igliano , Snc

Proprietà

Progettista

Costruttore

Tecnico

Dott.ssa Carboni Maria Grazia

CODICE CERTIFICATO

SS01-SORSO11/2024

Data elaborazione: 11/11/2024

Firmato Da: CARBONI MARIA GRAZIA Emesso Da: NAMIRIAL CA FIRMA QUALIFICATA Serial#: 2ac261897f278213

ATTESTATO DI PRESTAZIONE ENERGETICA DEGLI EDIFICI

CODICE CERTIFICATO: SS01-SORSO11/2024 VALIDO FINO AL: 11/11/2034

APE 2015

DATI GENERALI

Destinazione d'uso

- [ ] Residenziale
- [X] Non residenziale

Classificazione D.P.R. 412/93: E.8

Oggetto dell'attestato

- [ ] Intero edificio
- [X] Unità immobiliare
- [ ] Gruppo di unità immobiliari

numero di unità immobiliari di cui è composto l'edificio: 2

- [ ] Nuova costruzione
- [ ] Passaggio di proprietà
- [ ] Locazione
- [ ] Ristrutturazione importante
- [ ] Riqualificazione energetica
- [X] Altro: CTU TRIBUANALE SASSARI

Dati identificativi

Regione:	Sardegna
Comune:	SORSO
Indirizzo:	Zona Artigianale Sant'Igliano , n. Snc
Piano:	T
Interno:	
Coordinate GIS:	40,803578 ; 8,582603

Zona climatica:	C
Anno di costruzione:	2021
Superficie utile riscaldata (m^2):	210,35
Superficie utile raffrescata (m^2):	0,00
Volume lordo riscaldato (m^3):	1322,88
Volume lordo raffrescato (m^3):	0,00

Comune catastale			SORSO						Sezione			Foglio		56			Particella		1233		
Subalterni	da	1	a	1		da		a			da		a			da		a			
Altri subalterni																					

Servizi energetici presenti

- [X] Climatizzazione invernale
- [ ] Ventilazione meccanica
- [ ] Illuminazione
- [ ] Climatizzazione estiva
- [ ] Prod. acqua calda sanitaria
- [ ] Trasporto di persone o cose

PRESTAZIONE ENERGETICA GLOBALE E DEL FABBRICATO

La sezione riporta l'indice di prestazione energetica globale non rinnovabile in funzione del fabbricato e dei servizi energetici presenti, nonché la prestazione energetica del fabbricato, al netto del rendimento degli impianti presenti.

Prestazione energetica del fabbricato

INVERNO	ESTATE

Prestazione energetica globale

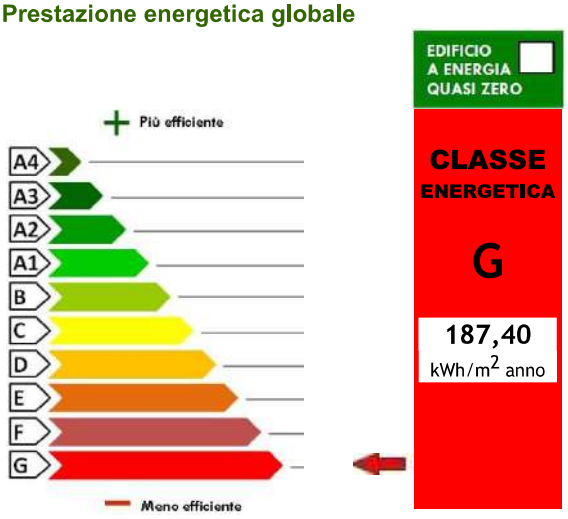

Riferimenti

Gli immobili simili a questo avrebbero in media la seguente classificazione:

se nuovi:

A1

24,63 kWh/m^2 anno

Firmato Da: CARBONI MARIA GRAZIA Emesso Da: NAMIRIAL CA FIRMA QUALIFICATA Serial#: 2ac261897f278213

PRESTAZIONE ENERGETICA DEGLI IMPIANTI E CONSUMI STIMATI

La sezione riporta l'indice di prestazione energetica rinnovabile e non rinnovabile, nonchè una stima dell'energia annua consumata annualmente dall'immobile secondo un uso standard.

Prestazioni energetiche degli impianti e stima dei consumi di energia

	FONTI ENERGETICHE UTILIZZATE	Quantità annua consumata in uso standard
☐	Energia elettrica da rete	-
X	Gas naturale	3.972,65 m³
☐	GPL	-
☐	Carbone	-
☐	Gasolio	-
☐	Olio combustibile	-
☐	Propano	-
☐	Butano	-
☐	Kerosene	-
☐	Antracite	-
☐	Biomasse	-
☐	Solare fotovoltaico	-
☐	Solare termico	-
☐	Eolico	-
☐	Teleriscaldamento	-
☐	Teleraffrescamento	-
☐	Altro	-

Indici di prestazione energetica globali ed emissioni

Indice della prestazione energetica non rinnovabile
EPgl,nren
kWh/m² anno
187,40

Indice della prestazione energetica rinnovabile
EPgl,ren
kWh/m² anno
0,00

Emissioni di CO_2
kg/m² anno
37,48

RACCOMANDAZIONI

La sezione riporta gli interventi raccomandati e la stima dei risultati conseguibili, con il singolo intervento o con la realizzazione dell'insieme di essi, esprimendo una valutazione di massima del potenziale di miglioramento dell'edificio o dell'immobile oggetto dell'attestato di prestazione energetica.

RIQUALIFICAZIONE ENERGETICA E RISTRUTTURAZIONE IMPORTANTE
INTERVENTI RACCOMANDATI E RISULTATI CONSEGUIBILI

Codice	TIPO DI INTERVENTO RACCOMANDATO	Comporta una ristrutturazione importante	Tempo di ritorno dell'investimento [anni]	Classe energetica raggiungibile con l'intervento [EPgl,nren - kWh/m² anno]	CLASSE ENERGETICA raggiungibile se si realizzano tutti gli interventi raccomandati
REN1					E 52,41 kWh/m² anno 5 anni
REN2					
REN3	Installazione dei seguenti impianti: Condizionatori/Split, Scaldacqua	No	4,6	E - 52,41	
REN4					
REN5					
REN6					

Firmato Da: CARBONI MARIA GRAZIA Emesso Da: NAMIRIAL CA FIRMA QUALIFICATA Serial#: 2ac261897f278213

ALTRI DATI ENERGETICI GENERALI

Energia esportata	0,00 kWh/anno	Vettore energetico: -

ALTRI DATI DI DETTAGLIO DEL FABBRICATO

V - Volume riscaldato	1322,880	m^3
S - Superficie disperdente	867,693	m^2
Rapporto S/V	0,656	
$EP_{H,nd}$	137,3	kWh/m^2 anno
$A_{sol,est}/A_{sup,utile}$	0,06	-
Y_{IE}	0,21	W/m^2K

DATI DI DETTAGLIO DEGLI IMPIANTI

Servizio energetico	Tipo di impianto	Anno di installazione	Codice catasto regionale impianti termici	Vettore energetico utilizzato	Potenza Nominale kW	Efficienza media stagionale	EPren kWh/m^2 anno	EPnren kWh/m^2 anno
Climatizzazione invernale	SIMULATO IN QUANTO ASSENTE					0,733 η_H	0,0	187,4
Climatizzazione estiva						η_C		
Prod. acqua calda sanitaria						η_W		
Impianti combinati								
Produzione da fonti rinnovabili								
Ventilazione meccanica								
Illuminazione								
Trasporto di persone o cose								

Firmato Da: CARBONI MARIA GRAZIA Emesso Da: NAMIRIAL CA FIRMA QUALIFICATA Serial#: 2ac261897f278213

INFORMAZIONI SUL MIGLIORAMENTO DELLA PRESTAZIONE ENERGETICA

La sezione riporta informazioni sulle opportunità, anche in termini di strumenti di sostegno nazionali o locali, legate all'esecuzione di diagnosi energetiche e interventi di riqualificazione energetica, comprese le ristrutturazioni importanti.

Gli interventi suggeriti consentono un apprezzabile miglioramento delle prestazioni e le spese da sostenere sono attualmente incentivabili mediante pratica di detrazione delle spese per riqualificazione energetica.

SOGGETTO CERTIFICATORE

☐ Ente / Organismo pubblico	☒ Tecnico abilitato	☐ Organismo / Società

Nome e Cognome / Denominazione	Dott.ssa Carboni Maria Grazia
Indirizzo	Via Ugo la Malfa, 32 - 07100 - SASSARI (SS)
E-mail	studiomariagraziacarboni@gmail.com maria_grazia.carboni@conafpec.it
Telefono	
Titolo	DOTT. AGRONOMO
Ordine/Iscrizione	ORDINE DOTT.RI AGRONOMI E DOTT.RI FORESTALI DELLA PROVINCIA DI SASSARI N. 786
Dichiarazione di indipendenza	*Consapevole delle responsabilità assunte in relazione ai contenuti del presente attestato di prestazione energetica, ai sensi degli artt. 359, 481 del Codice Penale, DICHIARO di poter svolgere con indipendenza ed imparzialità di giudizio, l'attività di soggetto certificatore per il sistema edificio/impianto di cui al punto 1 "informazioni generali" vista l'assenza di conflitti di interesse come esplicitati nel DPR n. 75 del 16 aprile 2013, articolo 3, comma 1, lettere a) e b).*
Informazioni aggiuntive	

SOPRALLUOGHI E DATI DI INGRESSO

E' stato eseguito almeno un sopralluogo/rilievo sull'edificio obbligatorio per la redazione del presente APE?	**Sì**

SOFTWARE UTILIZZATO

Il software utilizzato risponde ai requisiti di rispondenza e garanzia di scostamento massimo dei risultati conseguiti rispetto ai valori ottenuti per mezzo dello strumento di riferimento nazionale?	**Sì**
Ai fini della redazione del presente attestato è stato utilizzato un software che impieghi un metodo di calcolo semplificato?	**No**

Il presente attestato è reso, dal sottoscritto, in forma di dichiarazione sostitutiva di atto notorio ai sensi dell'articolo 47 del D.P.R. 445/2000 e dell'articolo 15, comma 1 del D.Lgs. 192/2005 così come modificato dall'articolo 12 del D.L. 63/2013

Data di emissione 11/11/2024 Firma e timbro del tecnico o firma digitale _____

Firmato Da: CARBONI MARIA GRAZIA Emesso Da: NAMIRIAL CA FIRMA QUALIFICATA Serial#: 2ac261897f278213

Il presente documento attesta la **prestazione** e la **classe energetica** dell'edificio o dell'unità immobiliare, ovvero la quantità di energia necessaria ad assicurare il confort attraverso i diversi servizi erogati dai sistemi tecnici presenti, in condizioni convenzionali d'uso. Al fine di individuare le potenzialità di miglioramento della prestazione energetica, l'attestato riporta informazioni specifiche sulle prestazioni energetiche del fabbricato e degli impianti. Viene altresì indicata la classe energetica più elevata raggiungibile in caso di realizzazione delle misure migliorative consigliate, così come descritte nella sezione "**raccomandazioni**" (pag. 2).

PRIMA PAGINA

Informazioni generali: tra le informazioni generali è riportata la motivazione alla base della redazione dell'APE. Nell'ambito del periodo di validità, ciò non preclude l'uso dell'APE stesso per i fini di legge, anche se differenti da quelli ivi indicati.
Prestazione energetica globale (EPgl,nren): fabbisogno annuale di energia primaria non rinnovabile relativa a tutti i servizi erogati dai sistemi tecnici presenti, in base al quale è identificata la classe di prestazione dell'edificio in una scala da A4 (edificio più efficiente) a G (edificio meno efficiente).
Prestazione energetica del fabbricato: indice qualitativo del fabbisogno di energia necessario per il soddisfacimento del confort interno, indipendente dalla tipologia e dal rendimento degli impianti presenti. Tale indice da un'indicazione di come l'edificio, d'estate e d'inverno, isola termicamente gli ambienti interni rispetto all'ambiente esterno. La scala di valutazione qualitativa utilizzata osserva il seguente criterio:

QUALITA' ALTA	QUALITA' MEDIA	QUALITA' BASSA

I valori di soglia per la definizione del livello di qualità, suddivisi per tipo di indicatore, sono riportati nelle Linee guida per l'attestazione energetica degli edifici di cui al decreto previsto dall'articolo 6, comma 12 del D.Lgs. 192/2005.
Edificio a energia quasi zero: edificio ad altissima prestazione energetica, calcolata conformemente alle disposizioni del decreto legislativo 19 agosto 2005, n. 192 e del decreto ministeriale sui requisiti minimi previsto dall'articolo 4, comma 1 del D.Lgs. 192/2005. Il fabbisogno energetico molto basso o quasi nullo è coperto in misura significativa da energia da fonti rinnovabili, prodotta all'interno del confine del sistema (in situ). Una spunta sull'apposito spazio adiacente alla scala di classificazione indica l'appartenenza dell'edificio oggetto dell'APE a questa categoria.
Riferimenti: raffronto con l'indice di prestazione globale non rinnovabile di un edificio simile ma dotato dei requisiti minimi degli edifici nuovi, nonchè con la media degli indici di prestazione degli edifici esistenti simili, ovvero contraddistinti da stessa tipologia d'uso, tipologia costruttiva, zona climatica, dimensioni ed esposizione di quella oggetto dell'attestato.

SECONDA PAGINA

Prestazioni energetiche degli impianti e consumi stimati: la sezione riporta l'indice di prestazione energetica rinnovabile e non rinnovabile dell'immobile oggetto di attestazione. Tali indici informano sulla percentuale di energia rinnovabile utilizzata dall'immobile rispetto al totale. La sezione riporta infine una stima del quantitativo di energia consumata annualmente dall'immobile secondo un uso standard, suddivisi per tipologia di fonte energetica utilizzata.
Raccomandazioni: di seguito si riporta la tabella che classifica le tipologie di intervento raccomandate per la riqualificazione energetica e la ristrutturazione importante.

RIQUALIFICAZIONE ENERGETICA E RISTRUTTURAZIONE IMPORTANTE EDIFICIO/UNITA' IMMOBILIARE - Tabella dei Codici

Codice	TIPO DI INTERVENTO
REN1	FABBRICATO - INVOLUCRO OPACO
REN2	FABBRICATO - INVOLUCRO TRASPARENTE
REN3	IMPIANTO CLIMATIZZAZIONE - INVERNO
REN4	IMPIANTO CLIMATIZZAZIONE - ESTATE
REN5	ALTRI IMPIANTI
REN6	FONTI RINNOVABILI

TERZA PAGINA

La terza pagina riporta la quantità di energia prodotta in situ ed esportata annualmente, nonchè la sua tipologia.
Riporta infine, suddivise in due sezioni relative rispettivamente al fabbricato e agli impianti, i dati di maggior dettaglio alla base del calcolo.

Firmato Da: CARBONI MARIA GRAZIA Emesso Da: NAMIRIAL CA FIRMA QUALIFICATA Serial#: 2ac261897f278213

Pratica Edilizia n° **135**
Anno **2007**

Comune di Sorso

Provincia di Sassari

AUTORIZZAZIONE DI VARIANTE N. 51

IL RESPONSABILE DEL SERVIZIO URBANISTICA

Vista la concessione n° **13** del **07/02/2006** rilasciata alla **Ditta** , con residenza a P.I. per l'esecuzione dei lavori **di costruzione di un capannone artigianale per deposito materiali ed attrezzature edili nel lotto n° 9 del P.I.P. del comparto D13 del PUC;**,

Presa in esame la richiesta presentata in data **18/06/2007** prot. n° **8307** dal concessionario per ottenere l'autorizzazione di variante alla concessione edilizia già rilasciata n° **13/2006**;

Accertato che la domanda è stata presentata prima della dichiarazione di ultimazione dei lavori;

Ritenuto dall'esame dei documenti prodotti che le varianti richieste:

- Sono conformi agli strumenti urbanistici e al regolamento edilizio vigenti;
- Non sono in contrasto agli strumenti urbanistici e al regolamento edilizio adottati;
- Non comportano modifiche della sagoma e non violano le eventuali prescrizioni contenute nella concessione edilizia;
- Non modificano la destinazione d'uso e la categoria edilizia;

Visto il T.U. delle disposizioni legislative e regolamentari in materia edilizia (D.P.R. n° 380/2001);

Visto l'art. 13 della Legge Regionale 23/85 e successive modifiche ed integrazioni;

Viste le leggi 17.08.1942, n° 1150, e 06.08.1967, n° 765;

Visto dell'Ufficio Tecnico Comunale in data **22/06/07**;

Visti gli atti tecnici ed amministrativi;

Vista il parere della A.S.L. n° 1 di Sassari sui requisiti igienico-sanitari in data **15/06/07**;

Visti i disegni di progetto allegati alla domanda, a firma del **Dott. Ing.** ,

AUTORIZZA

la **Ditta** ad apportare alla concessione n° **13** rilasciata in data **07/02/2006** la variante per le modifiche interne e di prospetto ferme restando, anche per i lavori di variante, le condizioni tutte prescritte nella originaria concessione, compreso il termine di ultimazione dei lavori e quelle che qui di seguito si indicano:

Sorso, lì 25 GIU 2007

IL RESPONSABILE DEL SERVIZIO
Ing. Marco Delrio

COMUNE DI SORSO - Urbanistica

I sottoscritti dichiarano di accettare la presente autorizzazione.

Addì, 25 GIU 2007

Firma

Visto, per accettazione e ricevuta della presente concessione

IL CONCESSIONARIO

SORSO, lì 07 FEB 2006

RELAZIONE DI NOTIFICA

PUBBLICAZIONE ALL'ALBO

La presente concessione è stata messa in pubblicazione dal _____ al _____ registrata al n° _____ R.P.

PROROGA DEI TERMINI

IL RESPONSABILE DEL SERVIZIO

- Vista la domanda di _____ in data _____ prot. n° _____;
- Ritenute valide le motivazioni che hanno ritardato l'esecuzione dei lavori previsti nella presente concessione;
- Visto l'art. 15 del D.P.R. 6 giugno 2001 n° 380,

CONCEDE

la proroga del termine di validità della presente concessione, al fine di consentire l'ultimazione dei lavori, per un periodo di _____ a partire dal _____

SORSO, lì _____

IL RESPONSABILE DEL SERVIZIO

_____

VOLTURA DELLA CONCESSIONE

IL RESPONSABILE DEL SERVIZIO

- Vista la richiesta di _____ in data _____ prot. n° _____, tendente ad ottenere il trasferimento della titolarità della presente concessione, con allegata documentazione comprovante l'avvenuta acquisizione del titolo ad edificare;
- Visto l'art. 11 del D.P.R. 6 giugno 2001 n° 380,

TRASFERISCE IL TITOLO DELLA PRESENTE CONCESSIONE A

(generalità del concessionario) *(codice fiscale)*

SORSO, lì _____

IL RESPONSABILE DEL SERVIZIO

_____

COPIA ARTICO

Pratica Edilizia n° **26** anno **2004**

marca da bollo

COMUNE DI SORSO

Provincia di Sassari

CONCESSIONE EDILIZIA n° 13 del 07 FEB 2006

IL RESPONSABILE DEL SERVIZIO URBANISTICA

VISTA la **domanda di rinnovo** in data **08/09/2005** protocollo n° 12119 presentata dal Sig. , **RAPPRESENTANTE LEGALE DELLA DITTA** ' " per ottenere il rilascio di concessione edilizia per l'esecuzione dei lavori di **costruzione di un capannone da destinare ad attività artigianale per deposito di materiali edili nell'area del P.I.P., lotto n° 9, comparto D13** in **località "La Prunosa"**

VISTO che il richiedente ha titolo alla concessione in qualità di **proprietario** come risulta da documentazione esibita;

VISTA la propria precedente Concessione Edilizia n° **70** del **29/06/2004**;

VISTI i pareri:

- della Azienda Sanitaria Locale di Sassari n° 1 in data **06/09/05**;
- dell'Ufficio Tecnico Comunale in data **10/01/06**;

PRESO ATTO che la Commissione Edilizia Comunale ha espresso parere favorevole nella seduta del **27/10/05**;

VISTO in data prot. U.T.U. ;

VISTO lo strumento urbanistico comunale vigente;

VISTI i regolamenti comunali di edilizia, igiene e polizia urbana;

VISTO il T.U. delle disposizioni legislative e regolamentari in materia edilizia (D.P.R. n° 380/2001);

VISTE le leggi regionali 11 ottobre 1985 n° 23, 22 dicembre 1989 n° 45 e successive modifiche e integrazioni;

- ;

VISTO che, agli effetti del contributo di concessione di cui all'art. 16 del T.U. delle disposizioni legislative e regolamentari in materia edilizia (D.P.R. n° 380/2001)

a) il contributo riferito agli oneri di urbanizzazione già assolto con C.E. 70/2004 ;

b) il contributo riferito al costo di costruzione gia assolto con C.E. 70/2004;

RILASCIA CONCESSIONE EDILIZIA A

P.IVA

---

per l'esecuzione dei lavori di **costruzione di un capannone da destinare ad attività artigianale all'interno del P.I.P., comparto D13 lotto n° 9** con destinazione **deposito materiali edili** in **località "La Prunosa"** catasto **terreni** foglio **56** mappale/i n° **559-563-574** quali risultano dal progetto redatto dal **Dott. Ing.** C.F. composto di n° 3 tavole che, vistate, sono allegate alla precedente Concessione Edilizia n° 70 del 29/06/2004 come parte integrante.

I lavori dovranno essere iniziati entro 1 anno dalla data di rilascio della presente ed ultimati entro 3 anni dalla data di inizio dei lavori.

I lavori stessi dovranno essere eseguiti nel rispetto del progetto e delle destinazioni d'uso approvate nonché con osservanza delle leggi e regolamenti e prescrizioni di seguito riportate.

Avvertenze e prescrizioni

La presente concessione è rilasciata fatti salvi i diritti di terzi.

Il concessionario, il direttore dei lavori e il costruttore sotto la loro piena ed esclusiva responsabilità, devono adottare tutti quei mezzi ed accorgimenti necessari per evitare pericoli di qualsiasi genere che possono derivare dall'esecuzione delle opere. Essi sono responsabili d'ogni inosservanza sia delle norme generali di leggi e regolamenti che delle modalità d'esecuzione della concessione.

Il titolare della concessione non può comunque dare inizio ai lavori se non abbia prima comunicato al responsabile del Servizio il nominativo, la qualifica è l'indirizzo del direttore dei lavori, del costruttore ed eventualmente del tecnico dell'impresa, e tale comunicazione non sia stata confermata dalla firma di questo ultimo, e non abbia provveduto all'adempimento di cui all'art. 8 della legge 5.11.1971 n° 1086 e successive modifiche ed integrazioni.

Ogni variazione successiva deve essere cominciata dagli interessati al responsabile del Servizio entro 8 giorni.

Il titolare della concessione e il direttore dei lavori devono comunicare la data d'effettivo inizio dei lavori entro 5 giorni dall'effettivo inizio.

Il direttore dei lavori ed il concessionario, deve comunicare la fine dei lavori ad ultimazione avvenuta degli stessi, nel caso di mancata ultimazione dei lavori nel termine prescritto, salvo il caso di proroga consentita dalle vigenti disposizioni, dovrà essere richiesta una nuova concessione per la parte non ultimata, ed il concessionario deve chiedere al comune la visita definitiva per il rilascio del certificato di abitabilità e /o agibilità.

In tutti i cantieri di lavoro deve essere affissa, in vista del pubblico, una tabella delle dimensioni di cm 40x60, chiaramente leggibile, in cui siano indicati: 1) cognome e nome del proprietario committente ed eventualmente dell'Amministrazione pubblica interessata ai lavori. 2) cognome, nome e titolo professionale del progettista e del direttore dei lavori e del calcolatore delle opere in cemento armato. 3) denominazione dell'impresa assuntrice dei lavori ed eventualmente indicazione che i lavori sono eseguiti in economia diretta. 4) nome, cognome e qualifica dall'assistente. 5) estremi della concessione con la data del rilascio. 6) data dell'inizio dei lavori ufficialmente comunicata.

Ogni cantiere è soggetto alle norme ENPI.

In particolare i cantieri devono essere organizzati con il rispetto delle norme sulla prevenzione degli infortuni, sulla sicurezza delle opere provvisionali e dei mezzi d'opera di qualsiasi tipo, sull'uso dell'energia elettrica, dei combustibili e dei macchinari e sulla prevenzione degli incendi.

I cantieri devono essere cintati e mantenuti liberi da materiali inutili e dannosi per tutta la durata dei lavori.

Le recinzioni devono essere decorose e dotate in ogni angolo di lanterne rosse, facilmente visibili a media distanza, mantenute accese, durante l'intero orario della pubblica illuminazione stradale, ed avere porte apribili verso l'interno munite di serratura o catenacci che ne assicurino la chiusura nelle ore di sospensione dei lavori.

La concessione edilizia, o copia di essa, unitamente all'esemplare dei disegni vistati dall'ufficio tecnico comunale dovrà sempre trovarsi nel cantiere dei lavori per essere esibita in ogni circostanza all'Autorità Comunale o ai suoi funzionari agenti incaricati.

Per quanto non contenuto nelle presenti avvertenze si rimanda alle prescrizioni del vigente R.E.

Prescrizioni speciali:

SORSO, lì 07 FEB 2006

IL RESPONSABILE DEL SERVIZIO

Dott. Ing. Marco Delrio

COMUNE DI SORSO - UFFICIO URBANISTICA

Visto, per accettazione e ricevuta della presente concessione

IL CONCESSIONARIO

SORSO, lì 30 GIU 2004

_____

RELAZIONE DI NOTIFICA

PUBBLICAZIONE ALL'ALBO

La presente concessione è stata messa in pubblicazione dal _____ al _____ registrata al n° _____ R.P.

PROROGA DEI TERMINI

IL RESPONSABILE DEL SERVIZIO

- Vista la domanda di _____ in data _____ prot. n° _____;
- Ritenute valide le motivazioni che hanno ritardato l'esecuzione dei lavori previsti nella presente concessione;
- Visto l'art. 15 del D.P.R. 6 giugno 2001 n° 380,

CONCEDE

la proroga del termine di validità della presente concessione, al fine di consentire l'ultimazione dei lavori, per un periodo di _____ a partire dal _____

SORSO, lì _____

IL RESPONSABILE DEL SERVIZIO

_____

VOLTURA DELLA CONCESSIONE

IL RESPONSABILE DEL SERVIZIO

- Vista la richiesta di _____ in data _____ prot. n° _____, tendente ad ottenere il trasferimento della titolarità della presente concessione, con allegata documentazione comprovante l'avvenuta acquisizione del titolo ad edificare;
- Visto l'art. 11 del D.P.R. 6 giugno 2001 n° 380,

TRASFERISCE IL TITOLO DELLA PRESENTE CONCESSIONE A

(generalità del concessionario) *(codice fiscale)*

SORSO, lì _____

IL RESPONSABILE DEL SERVIZIO

_____

Pratica Edilizia n° **26** anno **2004**

marca da bollo di € 10,33

COMUNE DI SORSO

Provincia di Sassari

CONCESSIONE EDILIZIA n° 70 del 29 GIU 2004

IL RESPONSABILE DEL SERVIZIO URBANISTICA

VISTA la **domanda** in data **24/02/2004** protocollo n° 3327 presentata dal Sig. **in qualità di rappresentante legale della società "** **"** per ottenere il rilascio di concessione edilizia per l'esecuzione dei lavori di **costruzione di un capannone da destinare ad attività artigianale per deposito di materiali edili nell'area del P.I.P. lotto n° 9, Comparto di Lottizzazione "D13"** in **Località Prunosa**

VISTO che il richiedente ha diritto alla concessione in qualità di **avente titolo** come risulta da documentazione esibita ;

_____

VISTI i pareri:

- della Azienda Sanitaria Locale di Sassari n° 1 in data **24/02/04;**
- dell'Ufficio Tecnico Comunale in data **06/04/04**;

PRESO ATTO che la Commissione Edilizia Comunale ha espresso parere favorevole nella seduta del **14/04/04**

VISTA / / / / in data / / / / prot. U.T.U. / / / /;

VISTO lo strumento urbanistico comunale vigente;

VISTI i regolamenti comunali di edilizia, igiene e polizia urbana;

VISTO il T.U. delle disposizioni legislative e regolamentari in materia edilizia (D.P.R. n° 380/2001);

VISTE le leggi regionali 11 ottobre 1985 n° 23, 22 dicembre 1989 n° 45 e successive modifiche e integrazioni;

- ;

VISTO che, agli effetti del contributo di concessione di cui all'art. 16 del T.U. delle disposizioni legislative e regolamentari in materia edilizia (D.P.R. n° 380/2001)

a) il contributo riferito agli oneri di urbanizzazione II di € 45,50

IMPORTO VERSTO A SALDO DI € 45,50, AFFERENTE GLI ONERI DI URBANIZZAZIONE II, MEDIANTE C.C.P. 12527073 INTESTATO AL COMUNE DI SORSO IN DATA 28/06/2004 N° 76.

b) il contributo riferito al costo di costruzione (Circolare 20.03.78 n° 5/D del D.Ass. 31.01.78 art. 3)

RILASCIA CONCESSIONE EDILIZIA A

C.F.

per l'esecuzione dei lavori di **costruzione capannone da destinare ad attività artigianale per deposito di materiali edili nell'area del P.I.P. lotto n° 9, comparto di lottizzazione "D13"** in **Località Prunosa** catasto **terreni** foglio **56** mappale/i n° **559-563-574** quali risultano dal progetto redatto dal **Dott. Ing.** C.F. composto di n° **3** tavole che, vistate, si allegano alla presente concessione come parte integrante.

I lavori dovranno essere iniziati entro 1 anno dalla data di rilascio della presente ed ultimati entro 3 anni sempre dalla data d' inizio dei lavori.

I lavori stessi dovranno essere eseguiti nel rispetto del progetto e delle destinazioni d'uso approvate nonché con osservanza delle leggi e regolamenti e prescrizioni di seguito riportate.

Avvertenze e prescrizioni

La presente concessione è rilasciata fatti salvi i diritti di terzi.

Il concessionario, il direttore dei lavori e il costruttore sotto la loro piena ed esclusiva responsabilità, devono adottare tutti quei mezzi ed accorgimenti necessari per evitare pericoli di qualsiasi genere che possono derivare dall'esecuzione delle opere. Essi sono responsabili d'ogni inosservanza sia delle norme generali di leggi e regolamenti che delle modalità d'esecuzione della concessione.

Il titolare della concessione non può comunque dare inizio ai lavori se non abbia prima comunicato al responsabile del Servizio il nominativo, la qualifica è l'indirizzo del direttore dei lavori, del costruttore ed eventualmente del tecnico dell'impresa, e tale comunicazione non sia stata confermata dalla firma di questo ultimo, e non abbia provveduto all'adempimento di cui all'art. 8 della legge 5.11.1971 n° 1086 e successive modifiche ed integrazioni.

Ogni variazione successiva deve essere cominciata dagli interessati al responsabile del Servizio entro 8 giorni.

Il titolare della concessione e il direttore dei lavori devono comunicare la data d'effettivo inizio dei lavori entro 5 giorni dall'effettivo inizio.

Il direttore dei lavori ed il concessionario, deve comunicare la fine dei lavori ad ultimazione avvenuta degli stessi, nel caso di mancata ultimazione dei lavori nel termine prescritto, salvo il caso di proroga consentita dalle vigenti disposizioni, dovrà essere richiesta una nuova concessione per la parte non ultimata, ed il concessionario deve chiedere al comune la visita definitiva per il rilascio del certificato di abitabilità e /o agibilità.

In tutti i cantieri di lavoro deve essere affissa, in vista del pubblico, una tabella delle dimensioni di cm 40x60, chiaramente leggibile, in cui siano indicati: 1) cognome e nome del proprietario committente ed eventualmente dell'Amministrazione pubblica interessata ai lavori. 2) cognome, nome e titolo professionale del progettista e del direttore dei lavori e del calcolatore delle opere in cemento armato. 3) denominazione dell'impresa assuntrice dei lavori ed eventualmente indicazione che i lavori sono eseguiti in economia diretta. 4) nome, cognome e qualifica dall'assistente. 5) estremi della concessione con la data del rilascio. 6) data dell'inizio dei lavori ufficialmente comunicata.

Ogni cantiere è soggetto alle norme ENPI.

In particolare i cantieri devono essere organizzati con il rispetto delle norme sulla prevenzione degli infortuni, sulla sicurezza delle opere provvisionali e dei mezzi d'opera di qualsiasi tipo, sull'uso dell'energia elettrica, dei combustibili e dei macchinari e sulla prevenzione degli incendi.

I cantieri devono essere cintati e mantenuti liberi da materiali inutili e dannosi per tutta la durata dei lavori.

Le recinzioni devono essere decorose e dotate in ogni angolo di lanterne rosse, facilmente visibili a media distanza, mantenute accese, durante l'intero orario della pubblica illuminazione stradale, ed avere porte apribili verso l'interno munite di serratura o catenacci che ne assicurino la chiusura nelle ore di sospensione dei lavori.

La concessione edilizia, o copia di essa, unitamente all'esemplare dei disegni vistati dall'ufficio tecnico comunale dovrà sempre trovarsi nel cantiere dei lavori per essere esibita in ogni circostanza all'Autorità Comunale o ai suoi funzionari agenti incaricati.

Per quanto non contenuto nelle presenti avvertenze si rimanda alle prescrizioni del vigente R.E.

Prescrizioni speciali:
L'utilizzo del fabbricato di cui alla presente concessione edilizia potrà avvenire solo esclusivamente al rilascio di certificato di agibilità, che verrà rilasciato dopo che le infrastrutture della lottizzazione saranno realizzate e collaudate.

SORSO, lì 29 GIU 2004

COMUNE DI SORSO - UFFICIO URBANISTICA

IL RESPONSABILE DEL SERVIZIO
Geom. Giuseppe Secchi