TRIBUNALE DI SASSARI

SEZIONE EE.II.

Perizia dell'Esperto ex art. 568 c.p.c. Ing. Pinna Alessio, nell'Esecuzione Immobiliare 190/2021 del R.G.E.

promossa da

******* Omissis *******

******* Omissis *******

contro

******* Omissis *******

******* Omissis *******

Firmato Da: PINNA ALESSIO Emesso Da: ARUBAPEC S.P.A. NG CA 3 Serial#: 4fbdc9933702dd1ac3c2f53e17f48968

SOMMARIO

Incarico 3
Premessa 3
Descrizione 3
Lotto Unico 3
Completezza documentazione ex art. 567 3
Titolarità 3
Confini 4
Consistenza 4
Cronistoria Dati Catastali 5
Dati Catastali 5
Precisazioni 5
Patti 6
Stato conservativo 6
Parti Comuni 6
Servitù, censo, livello, usi civici 6
Caratteristiche costruttive prevalenti 6
Stato di occupazione 6
Provenienze Ventennali 7
Formalità pregiudizievoli 7
Normativa urbanistica 8
Regolarità edilizia 8
Vincoli od oneri condominiali 9
Stima / Formazione lotti 9
Riepilogo bando d'asta 12
Lotto Unico 12
Schema riassuntivo Esecuzione Immobiliare 190/2021 del R.G.E. 13
Lotto Unico 13
Formalità da cancellare con il decreto di trasferimento 14

Firmato Da: PINNA ALESSIO Emesso Da: ARUBAPEC S.P.A. NG CA 3 Serial#: 4fbdc9933702dd1ac3c2f53e17f48968

INCARICO

All'udienza del 21/05/2024, il sottoscritto Ing. Pinna Alessio, con studio in Via Nino Campus, 2 - 07100 - Sassari (SS), email alessio.ing.pinna@gmail.com, PEC alessio.pinna@ingpec.eu, Tel. 377/2621907, veniva nominato Esperto ex art. 568 c.p.c. e in data 27/05/2024 accettava l'incarico e prestava giuramento di rito.

PREMESSA

I beni oggetto di pignoramento sono costituiti dai seguenti immobili:

- **Bene N° 1** - Appartamento ubicato a Sennori (SS) - VIA SALVADOR ALLENDE 15

DESCRIZIONE

L'immobile pignorato è una abitazione indipendente costituita da due livelli fuori terra e un livello interrato. Si accede direttamente al bene dalla via Allende n.15, posta alla periferia sud est del paese di Sennori, zona a prevalenza residenziale. Sono presenti i servizi essenziali concentrati perlopiù nella zona centrale del paese.
Al piano terra è situata la zona giorno comprendente il soggiorno, cucina con accesso diretto al cortile, bagno e scala centrale. Sono anche presenti una veranda chiusa adiacente alla cucina, e una tettoia sul lato sinistro soggiorno. Il piano primo ospita la zona notte, costituita da tre letto, bagno e ripostiglio. La zona interrata comprende due locali cantina e wc.

La vendita del bene non è soggetta IVA.

Per il bene in questione non è stato effettuato un accesso forzoso.

LOTTO UNICO

Il lotto è formato dai seguenti beni:

- **Bene N° 1** - Appartamento ubicato a Sennori (SS) - VIA SALVADOR ALLENDE 15

COMPLETEZZA DOCUMENTAZIONE EX ART. 567

Si attesta che la documentazione di cui all'art. 567 c.p.c., comma 2 risulta completa.

La documentazione catastale risulta integrale, si attesta pertanto che la documentaizone di cui all'art. 567 c.p.c. comma 2 risulta completa. In particolare è presente agli atti il certificato notarile a firma del notaio Trotta Antonio in Pavia (PV) che certifica i documenti ipo-catastali.

TITOLARITÀ

Firmato Da: PINNA ALESSIO Emesso Da: ARUBAPEC S.P.A. NG CA 3 Serial#: 4fbdc9933702dd1ac3c2f53e17f48968

L'immobile oggetto dell'esecuzione, appartiene ai seguenti esecutati:

- **** Omissis **** (Proprietà 1/2)
- **** Omissis **** (Proprietà 1/2)

L'immobile viene posto in vendita per i seguenti diritti:

- **** Omissis **** (Proprietà 1/2)
- **** Omissis **** (Proprietà 1/2)

Regime patrimoniale di comunione legale dei beni.

CONFINI

L'immobile confina a nord-est con la strada via Allende, a nord-ovest con il lotto mappale 1409, a sud-est con il mappale 942, a sud-ovest con il mappale 589.

CONSISTENZA

Destinazione	Superficie Netta	Superficie Lorda	Coefficiente	Superficie Convenzionale	Altezza	Piano
Box	26,80 mq	34,40 mq	0,5	17,20 mq	0,00 m	1s
Cantina	31,35 mq	40,79 mq	0,50	20,39 mq	0,00 m	1s
bagno	8,36 mq	11,66 mq	0,5	5,83 mq	0,00 m	1s
Abitazione	66,65 mq	86,50 mq	1	86,50 mq	0,00 m	pt
Terrazzo 1	4,82 mq	4,82 mq	0,3	1,45 mq	0,00 m	pt
tettoia	21,90 mq	21,90 mq	0,3	6,57 mq	0,00 m	pt
veranda chiusa	21,55 mq	21,55 mq	0,3	6,46 mq	0,00 m	pt
Abitazione	66,99 mq	85,51 mq	1	85,51 mq	0,00 m	1p
Terrazzo 2	18,71 mq	18,71 mq	0,3	5,61 mq	0,00 m	1p
Terrazzo 3	3,98 mq	3,98 mq	0,3	1,19 mq	0,00 m	1p
Giardino	161,55 mq	161,55 mq	0,18	36,90 mq	0,00 m	pt
			Totale superficie convenzionale:	**273,61 mq**		
			Incidenza condominiale:	**0,00**	**%**	
			Superficie convenzionale complessiva:	**273,61 mq**		

Firmato Da: PINNA ALESSIO Emesso Da: ARUBAPEC S.P.A. NG CA 3 Serial#: 4fbdc9933702dd1ac3c2f53e17f48968

I beni non sono comodamente divisibili in natura.

Il giardino catastalmente misura 205 mq incluse le superfici occupate abusivamente dalla tettoia e dalla veranda chiusa. Pertanto sottraendo le due superfici occupate pari a 43,45 mq si ottiene 161,55 mq.

CRONISTORIA DATI CATASTALI

Periodo	Proprietà	Dati catastali
Dal **19/10/2001** al **09/08/2024**	**** Omissis ****	Catasto **Fabbricati** Fg. 22, Part. 2185 Categoria A2 Cl.U, Cons. 8 vani Superficie catastale 231 mq Rendita € 640,41

I titolari catastali corrispondono a quelli reali.
L'immobie è stato accatastato il 19/10/2001 a seguito della sua edificazione e da allora è rimasto invariato.

DATI CATASTALI

Catasto fabbricati (CF)											
Dati identificativi				Dati di classamento							
Sezione	Foglio	Part.	Sub.	Zona Cens.	Categoria	Classe	Consistenza	Superficie catastale	Rendita	Piano	Graffato
	22	2185			A2	U	8 VANI	231 mq	640,41 €		

Corrispondenza catastale

Non sussiste corrispondenza catastale.

Il confornto tra le planimetrie catastali con lo stato dei luoghi hanno riscontrato delle difformità catastali.
la tettoia e la veranda chiusa (costituente volumetria non assentita) non sono rappresente graficamente.
Sarà necessario presentare una variazione catastale previo accertamento di conformità urbanistica e autorizzazione del comune.

PRECISAZIONI

Firmato Da: PINNA ALESSIO Emesso Da: ARUBAPEC S.P.A. NG CA 3 Serial#: 4fbdc9933702dd1ac3c2f53e17f48968

Sono stati esaminati gli atti del procedimento e controllata la completezza dei documenti di cui all'art. 567 secondo comma c.p.c. In particolare è presente agli atti il certificato notarile a firma di Trotta Antonio notaio in Pavia.

PATTI

Non risultano contratti di locazione in essere

STATO CONSERVATIVO

L'immobile si trova in buono stato di conservazione, sia internamente che esternamente. Non sono stati rilevati elementi o parti in distacco, umidità, o degradi di qualunque tipo. Gli impianti idrico-fognari, come l'impianto elettrico risultano funzionanti e in buone condizioni di manutenzione. è anche presente l'impianto di riscaldamento a termosifoni alimentato da caldaia a gas e due pompe di calore tipo split, oltre un impianto fotovoltaico senza accumulo, tutti funzionanti.

PARTI COMUNI

L'immobile pignorato non risulta avere parti comuni con altre proprità o essere inserito in contesto condominiale

SERVITÙ, CENSO, LIVELLO, USI CIVICI

Sono stati verificati gli elenchi degli usi civici della Regione Sardegna e il bene oggetto di pignoramento non è presente tra questi, e neanche servitù.

CARATTERISTICHE COSTRUTTIVE PREVALENTI

L'immobile pignorato è costituito da 2 piani fuori terra e 1 piano interrato. Tutti i piani sono collegati da scala interna. La struttura del corpo di fabbrica, libero su tre lati, è del tipo a muratura portante e solai in laterocemnto. la copertura è del tipo a padiglione su tre falde con tegole in cotto. l'altezza utile interna è di 2,70 m. Sono presenti rifiniture in legno per le scale, e porte interne. Gli infissi sono anchessi in legno con vetrocamera e persiane esterne. Sono presenti gli impianti elettrico, idrico-fognario, riscaldamento a termosifoni, tutti sottotraccia;è presente un'area esterna a giardino esclusivo.

STATO DI OCCUPAZIONE

Allo stato dei luoghi l'immobile è occupato dai coniugi esecutati **** Omissis **** e **** Omissis ****

Firmato Da: PINNA ALESSIO Emesso Da: ARUBAPEC S.P.A. NG CA 3 Serial#: 4fbdc9933702dd1ac3c2f53e17f48968

PROVENIENZE VENTENNALI

Periodo	Proprietà	Atti			
Dal **08/10/1987**	**** Omissis ****	**Compravendita**			
		Rogante	**Data**	**Repertorio N°**	**Raccolta N°**
		Gaetano Porcheddu	08/10/1987	24902	
		Trascrizione			
		Presso	**Data**	**Reg. gen.**	**Reg. part.**
		sassari	26/10/1987	11469	7742
		Registrazione			
		Presso	**Data**	**Reg. N°**	**Vol. N°**

Per quanto riguarda l'immobile oggetto di pignoramento:

- Sussiste continuità nelle trascrizioni per il ventennio precedente alla data di trascrizione del pignoramento;
- La situazione della proprietà antecedente il ventennio della trascrizione del pignoramento risulta invariata;
- La situazione della proprietà risulta attualmente invariata.

FORMALITÀ PREGIUDIZIEVOLI

Dalle visure ipotecarie effettuate presso l'Agenzia delle entrate di SASSARI aggiornate al 31/01/2022, sono risultate le seguenti formalità pregiudizievoli:

Iscrizioni

- **ipoteca volontaria** derivante da concessione a garanzia di mutuo
  Iscritto a Sassari il 24/10/2001
  Reg. gen. 61603 - Reg. part. .
  Quota: 1/1
  Importo: € 216.911,90
  A favore di **** Omissis ****
  Contro **** Omissis ****, **** Omissis ****
  Formalità a carico dell'acquirente
  Capitale: € 108.455,95
  Data: 25/10/2001
  N° repertorio: 18120
  N° raccolta: 1989

Firmato Da: PINNA ALESSIO Emesso Da: ARUBAPEC S.P.A. NG CA 3 Serial#: 4fbdc9933702dd1ac3c2f53e17f48968

- **Ipoteca legale** derivante da atto rogiti Equitalia
  Iscritto a Sassari il 16/07/2009
  Reg. gen. 27821 - Reg. part. 2009
  Quota: 1/2
  Importo: € 398.039,08
  A favore di **** Omissis ****
  Contro **** Omissis ****
  Capitale: € 199.019,54

Trascrizioni

- **Pignoramento immobiliare**
  Trascritto a Sassari il 28/05/2013
  Reg. gen. 7355 - Reg. part. 5242
  Quota: 1/2
  A favore di **** Omissis ****
  Contro **** Omissis ****
  Formalità a carico della procedura
- **Pignoramento immobiliare**
  Trascritto a Sassari il 23/12/2021
  Reg. gen. 20520 - Reg. part. 15472
  Quota: 1/1
  A favore di **** Omissis ****
  Contro **** Omissis ****, **** Omissis ****

i dati sono stati estrapolati dal certificato notarile a firma del notaio Trotta Antonio in Pavia.

NORMATIVA URBANISTICA

L'immobile pignorato ricade nel Piano Urbanistico Comunale di Sennori approvato con delibera comunale del 31/05/2017.
In particolare l'immobile appartine alla zona C1.1.F del puc. Le zone C sono le parti del territorio destinate a nuovi complessi residenziali, che risultino inedificate o nelle quali l'edificazione preesistente non raggiunga i limiti di superficie utilizzata richiesti per le zone B. Continuano ad essere classificate come zone C quelle previste negli strumenti urbanistici vigenti e già oggetto di attuazione.
Il P.U.C. identifica come zone C le parti di abitato cresciute in espansione della città compatta e le parti di territorio inedificate nelle quali si prevede di indirizzare lo sviluppo futuro rispondendo ad esigenze insediative di tipo prevalentemente residenziale. Le sottozone C1 sono quelle zone di espansione pianificate attraverso piani di lottizzazione attuati o in corso di attuazione.

REGOLARITÀ EDILIZIA

L'immobile non risulta regolare per la legge n° 47/1985. La costruzione non è antecedente al 01/09/1967. Non sono presenti vincoli artistici, storici o alberghieri. Non sono presenti diritti demaniali o usi civici. L'immobile non risulta agibile.

Firmato Da: PINNA ALESSIO Emesso Da: ARUBAPEC S.P.A. NG CA 3 Serial#: 4fbdc9933702dd1ac3c2f53e17f48968

L'immobile pignorato è stato autorizzato con una prima concessione edilizia n. 19/87 del 09/12/1987 rilasciata dal Comune di Sennori a nome di **** Omissis **** relativa a lavori di costruzione di una casa per civile abitazione lottizzazione Montigeddu. Una seconda concessione n. 19/87 bis del 21/04/1989 relativa a variazioni di progetto. La terza concessione n. 19/87 quater, e ultima concessione (ultimo stato assentito) concessione n. 19/87 quinques del 22/08/1990.
La pratica edilizia visionata non contiene il certificato di agibilità.

Non si ha notizia della concessione "ter".

Confrontando l'ultimo stato assentito (concessione n. 19/87 quinques presente agli atti) con il rilievo eseguito, si riscontrono diverse difformità.
1) Nel progetto al piano terra facciata principale, viene descritto l'ingresso con una scala frontale e un parapetto; questi elementi non sono rappresentati;
2) Al piano terra lato sinistro del rilievo è stata realizzata una tettoia non assentita (è assente graficamente);
3) Al pinao terra lato opposto all'ingresso è stata realizzata una veranda chiusa non assentita (è assente graficamente);
4) Al piano primo lato ingresso principale è stato realizzato un balcone continuo lungo tutta la facciata principale più parte del lato sinistro (il balcone non risulta rappresentato ne in pinata ne in prospetto);
5) il vano ripostiglio nel letto 1 al piano primo non è riportato in progetto;
6) la porzione di prospetto tra il piano primo e il tetto presenta una difformità rispetto allo stato dei luoghi rappresentata da una doppia gronda non realizzata.
Per sanare tali difformità è necessario presentare un accertamento di conformità.

VINCOLI OD ONERI CONDOMINIALI

Non sono presenti vincoli od oneri condominiali.

STIMA / FORMAZIONE LOTTI

Il valore commerciale dei beni pignorati è stato determinato sulla base delle seguenti variabili: ubicazione dell'immobile, caratteristiche e peculiarità della zona oltre che dalla facilità di raggiungimento, stato di manutenzione, conservazione, finitura e confort, consistenza, regolarità geometrica della forma, sussistenza di eventuali vincoli e servitù passive o attive, suoi dati metrici ed infine la situazione del mercato e della domanda e dell'offerta. Tutti questi elementi, in coesistenza all'esame di alcune documentazioni ufficiali ed esperita un'attenta e puntuale ricerca volta a determinare l'attuale valore di mercato indicando sia il valore per metro quadro che il valore complessivo, tenendo conto altresì di eventuali adeguamenti e correzioni della stima, hanno concorso a determinare il più probabile valore di compravendita da attribuire agli immobili oggetto della stima.

Firmato Da: PINNA ALESSIO Emesso Da: ARUBAPEC S.P.A. NG CA 3 Serial#: 4fbdc9933702dd1ac3c2f53e17f48968

Lo scrivente ha ritenuto opportuno procedere alla formazione di un lotto unico cosi costituito:

- **Bene N° 1** - Appartamento ubicato a Sennori (SS) - VIA SALVADOR ALLENDE 15
  L'immobile pignorato è una abitazione indipendente costituita da due livelli fuori terra e un livello interrato. Si accede direttamente al bene dalla via Allende n.15, posta alla periferia sud est del paese di Sennori, zona a prevalenza residenziale. Sono presenti i servizi essenziali concentrati perlopiù nella zona centrale del paese. Al piano terra è situata la zona giorno comprendente il soggiorno, cucina con accesso diretto al cortile, bagno e scala centrale. Sono anche presenti una veranda chiusa adiacente alla cucina, e una tettoia sul lato sinistro soggiorno. Il piano primo ospita la zona notte, costituita da tre letto, bagno e ripostiglio. La zona interrata comprende due locali cantina e wc.
  Identificato al catasto Fabbricati - Fg. 22, Part. 2185, Categoria A2
  L'immobile viene posto in vendita per il diritto di Proprietà (1/1)
  Valore di stima del bene: € 266.769,75
  Il metodo di stima utilizzato è quello sintetico per comparabili. I dati comparabili sono stati ricercati presso l'Agenzia delle Entrate di Sassari nella sezione consultazione valori dichiarati. I soli dati disponibili a seguito della ricerca sono la categoria catastale (A/2), la consistenza in vani o in metri quadrati,
  la quota di proprietà riferita, e naturalmente il corrispettivo in euro dichiarato nell'atto. La ricerca è stata eseguita
  includendo un arco temporale compreso tra gennaio e dicembre 2023. Il numero di atti trovati corrispondenti per similitudine sono stati 1. In particolare l'atto del comparabile presente risulta essere in una via vicino a quello oggetto di stima con una metratura paria a 278 mq su due livelli, Cat A/2 e un importo dichiarato di € 245.000, pari a 881€/mq. Per tale immobile non sono noti altri elementi di comparazione, quali la presenza e la grandezza di giardino esclusivo, anno di edificazione (vetustà immobile) e altri elementi utili per l'omogeneizzazione del comparabile.
  Si sottolinea che la banca dati dell'AdE non mette a disposizione altre informazioni quali il piano, la posizione rispetto alla strada, quantità e tipologia dei vani, il livello tecnologico, e soprattutto lo stato di manutenzione dello stesso immobile. Pertanto le informazioni disponibili consentono di fare delle valutazioni solo parziali per mettere a sistema gli immobili. A tal proposito altro elemento di riferimento è quello delle Quotazioni immobiliari dell'Osservatorio OMI. Nel merito, per la zona di interesse le quotazioni oscillano tra i 1000-1500 €/mq per le abitazioni civili (A2) in condizioni normali, identificando la media sui 1250 €/mq. La ricerca del più probabile valore di mercato, è stata condotta anche sugli immobili di nuova costruizone, riscontrando un trilocale a Sennori con caratteristiche simili ma più piccolo, del valore di 800 €/mq. Tenendo conto che la classificazione catastale non è un dato oggettivo ai fini della valutazione ma solo un riferimento, considerando che la categoria edilizia è del tipo unità immobiliare singola, tenuto conto l'ubicazione periferica del paese di Sennori, visto che i valori di riferimento non sono classificati secondo la vetustà dell'immobile o la qualità dello stesso, viste le buone condizioni generali dell'immobile e qualche elemento di pregio impiantistico, si ritiene congruo considerare come riferimento di partenza la media del valore OMI ovvero 1250 €/mq, a cui vanno tuttavia detratte alcune percentuali di deprezzamento:
  - Vetustà dell'immobile 0,5% anno (totale anni 23) pari 11,5%;
  - Oneri di regolarizzazione per opere non conformi 10,5%
  Totale decurtazione 22%. 1250*22% = 975 €/mq

Identificativo corpo	Superficie convenzionale	Valore unitario	Valore complessivo	Quota in vendita	Totale

Firmato Da: PINNA ALESSIO Emesso Da: ARUBAPEC S.P.A. NG CA 3 Serial#: 4fbdc9933702dd1ac3c2f53e17f48968

Bene N° 1 - Appartamento Sennori (SS) - VIA SALVADOR ALLENDE 15	273,61 mq	975,00 €/mq	€ 266.769,75	100,00%	€ 266.769,75
				Valore di stima:	€ 266.769,75

Assolto il proprio mandato, il sottoscritto Esperto ex art. 568 c.p.c. deposita la relazione di stima presso questo Spettabile Tribunale, tanto in assolvimento dell'incarico conferitogli dalla S.V. e resta a disposizione per eventuali chiarimenti.

Sassari, li 06/11/2024

L'Esperto ex art. 568 c.p.c.
Ing. Pinna Alessio

ELENCO ALLEGATI:

- ✓ Foto
- ✓ Tavola del progetto
- ✓ Concessione edilizia
- ✓ Estratti di mappa
- ✓ Visure e schede catastali
- ✓ Altri allegati - stalcio PUC
- ✓ Google maps

Firmato Da: PINNA ALESSIO Emesso Da: ARUBAPEC S.P.A. NG CA 3 Serial#: 4fbdc9933702dd1ac3c2f53e17f48968

RIEPILOGO BANDO D'ASTA

LOTTO UNICO

- **Bene N° 1** - Appartamento ubicato a Sennori (SS) - VIA SALVADOR ALLENDE 15
  L'immobile pignorato è una abitazione indipendente costituita da due livelli fuori terra e un livello interrato. Si accede direttamente al bene dalla via Allende n.15, posta alla periferia sud est del paese di Sennori, zona a prevalenza residenziale. Sono presenti i servizi essenziali concentrati perlopiù nella zona centrale del paese. Al piano terra è situata la zona giorno comprendente il soggiorno, cucina con accesso diretto al cortile, bagno e scala centrale. Sono anche presenti una veranda chiusa adiacente alla cucina, e una tettoia sul lato sinistro soggiorno. Il piano primo ospita la zona notte, costituita da tre letto, bagno e ripostiglio. La zona interrata comprende due locali cantina e wc.
  Identificato al catasto Fabbricati - Fg. 22, Part. 2185, Categoria A2
  L'immobile viene posto in vendita per il diritto di Proprietà (1/1)
  Destinazione urbanistica: L'immobile pignorato ricade nel Piano Urbanistico Comunale di Sennori approvato con delibera comunale del 31/05/2017. In particolare l'immobile appartine alla zona C1.1.F del puc. Le zone C sono le parti del territorio destinate a nuovi complessi residenziali, che risultino inedificate o nelle quali l'edificazione preesistente non raggiunga i limiti di superficie utilizzata richiesti per le zone B. Continuano ad essere classificate come zone C quelle previste negli strumenti urbanistici vigenti e già oggetto di attuazione. Il P.U.C. identifica come zone C le parti di abitato cresciute in espansione della città compatta e le parti di territorio inedificate nelle quali si prevede di indirizzare lo sviluppo futuro rispondendo ad esigenze insediative di tipo prevalentemente residenziale. Le sottozone C1 sono quelle zone di espansione pianificate attraverso piani di lottizzazione attuati o in corso di attuazione.

Firmato Da: PINNA ALESSIO Emesso Da: ARUBAPEC S.P.A. NG CA 3 Serial#: 4fbdc9933702dd1ac3c2f53e17f48968

SCHEMA RIASSUNTIVO
ESECUZIONE IMMOBILIARE 190/2021 DEL R.G.E.

LOTTO UNICO

Bene N° 1 - Appartamento			
Ubicazione:	Sennori (SS) - VIA SALVADOR ALLENDE 15		
Diritto reale:	Proprietà	**Quota**	1/1
Tipologia immobile:	Appartamento Identificato al catasto Fabbricati - Fg. 22, Part. 2185, Categoria A2	**Superficie**	273,61 mq
Stato conservativo:	L'immobile si trova in buono stato di conservazione, sia internamente che esternamente. Non sono stati rilevati elementi o parti in distacco, umidità, o degradi di qualunque tipo. Gli impianti idrico-fognari, come l'impianto elettrico risultano funzionanti e in buone condizioni di manutenzione. è anche presente l'impianto di riscaldamento a termosifoni alimentato da caldaia a gas e due pompe di calore tipo split, oltre un impianto fotovoltaico senza accumulo, tutti funzionanti.		
Descrizione:	L'immobile pignorato è una abitazione indipendente costituita da due livelli fuori terra e un livello interrato. Si accede direttamente al bene dalla via Allende n.15, posta alla periferia sud est del paese di Sennori, zona a prevalenza residenziale. Sono presenti i servizi essenziali concentrati perlopiù nella zona centrale del paese. Al piano terra è situata la zona giorno comprendente il soggiorno, cucina con accesso diretto al cortile, bagno e scala centrale. Sono anche presenti una veranda chiusa adiacente alla cucina, e una tettoia sul lato sinistro soggiorno. Il piano primo ospita la zona notte, costituita da tre letto, bagno e ripostiglio. La zona interrata comprende due locali cantina e wc.		
Vendita soggetta a IVA:	NO		
Continuità trascrizioni ex art. 2650 c.c.:	SI		
Stato di occupazione:	Allo stato dei luoghi l'immobile è occupato dai coniugi esecutati **** Omissis **** e **** Omissis ****		

Firmato Da: PINNA ALESSIO Emesso Da: ARUBAPEC S.P.A. NG CA 3 Serial#: 4fbdc9933702dd1ac3c2f53e17f48968

FORMALITÀ DA CANCELLARE CON IL DECRETO DI TRASFERIMENTO

Iscrizioni

- **ipoteca volontaria** derivante da concessione a garanzia di mutuo
  Iscritto a Sassari il 24/10/2001
  Reg. gen. 61603 - Reg. part. .
  Quota: 1/1
  Importo: € 216.911,90
  A favore di **** Omissis ****
  Contro **** Omissis ****, **** Omissis ****
  Formalità a carico dell'acquirente
  Capitale: € 108.455,95
  Data: 25/10/2001
  N° repertorio: 18120
  N° raccolta: 1989
- **Pignoramento immobiliare**
  Trascritto a Sassari il 23/12/2021
  Reg. gen. 20520 - Reg. part. 15472
  Quota: 1/1
  A favore di **** Omissis ****
  Contro **** Omissis ****, **** Omissis ****

Firmato Da: PINNA ALESSIO Emesso Da: ARUBAPEC S.P.A. NG CA 3 Serial#: 4fbdc9933702dd1ac3c2f53e17f48968

Allegato fotografico e rilievi

COMUNE DI SENNORI Via SALVATORE ALLENDE, 15 F. 22 - M. 2185

Immagine 1: Google Maps

Immagine 2: Sovrapposizione catastale Stimatix

Immagine 3: Stralcio PUC

Foto 1 – Cortile facciata principale - ingresso

Foto 2 – facciata laterale e cortile retro

Foto 3 – ingresso

Foto 4 – tettoia

ATTESTATO DI PRESTAZIONE ENERGETICA

Area geografica

Regione **Sardegna**

Provincia di **Sassari**

Comune di **SENNORI**

Ubicazione intervento

Via Salvador Allende , 15

Proprietà

Progettista

Costruttore

Tecnico
Dott. Ing. Alessio Pinna

CODICE CERTIFICATO

051124

Data elaborazione: 05/11/2024

ATTESTATO DI PRESTAZIONE ENERGETICA DEGLI EDIFICI

CODICE CERTIFICATO: 301124 **VALIDO FINO AL: 30/11/2034**

APE 2015

DATI GENERALI

Destinazione d'uso	Oggetto dell'attestato	
[X] Residenziale	[ ] Intero edificio	[ ] Nuova costruzione
		[X] Passaggio di proprietà

☐ Non residenziale Classificazione D.P.R. 412/93: E.1.1	X Unità immobiliare ☐ Gruppo di unità immobiliari numero di unità immobiliari di cui è composto l'edificio:	☐ Locazione ☐ Ristrutturazione importante ☐ Riqualificazione energetica ☐ Altro:

Dati identificativi

Regione:	Sardegna	**Zona climatica:**	D
Comune:	SENNORI	**Anno di costruzione:**	2001
Indirizzo:	Via Salvador Allende , n. 15	**Superficie utile riscaldata (m^2):**	201,96
Piano:		**Superficie utile raffrescata (m^2):**	0,00
Interno:		**Volume lordo riscaldato (m^3):**	820,08
Coordinate GIS:	40,784773 ; 8,593663	**Volume lordo raffrescato (m^3):**	0,00

Comune catastale			SENNORI						Sezione		22		Foglio		2185		Particella			
Subalterni	da		a			da		a			da		a			da		a		
Altri subalterni																				

Servizi energetici presenti

- X Climatizzazione invernale
- ☐ Ventilazione meccanica
- ☐ Illuminazione
- ☐ Climatizzazione estiva
- X Prod. acqua calda sanitaria
- ☐ Trasporto di persone o cose

PRESTAZIONE ENERGETICA GLOBALE E DEL FABBRICATO

La sezione riporta l'indice di prestazione energetica globale non rinnovabile in funzione del fabbricato e dei servizi energetici presenti, nonché la prestazione energetica del fabbricato, al netto del rendimento degli impianti presenti.

Prestazione energetica del fabbricato

INVERNO	ESTATE

Prestazione energetica globale

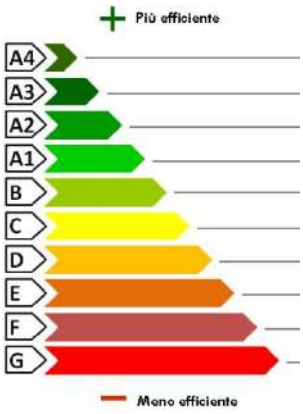

EDIFICIO A ENERGIA QUASI ZERO ☐

CLASSE ENERGETICA

G

353,74 kWh/m^2 anno

Riferimenti

Gli immobili simili a questo avrebbero in media la seguente classificazione:

se nuovi:

A1

85,82 kWh/m^2 anno

PRESTAZIONE ENERGETICA DEGLI IMPIANTI E CONSUMI STIMATI

La sezione riporta l'indice di prestazione energetica rinnovabile e non rinnovabile, nonchè una stima dell'energia annua consumata annualmente dall'immobile secondo un uso standard.

Prestazioni energetiche degli impianti e stima dei consumi di energia

	FONTI ENERGETICHE UTILIZZATE	Quantità annua consumata in uso standard
☐	Energia elettrica da rete	-
X	Gas naturale	2.403,55 m^3
X	GPL	1.692,52 m^3
☐	Carbone	-
☐	Gasolio	-
☐	Olio combustibile	-
☐	Propano	-
☐	Butano	-
☐	Kerosene	-
☐	Antracite	-
☐	Biomasse	-
X	Solare fotovoltaico	-
☐	Solare termico	-
☐	Eolico	-
☐	Teleriscaldamento	-
☐	Teleraffrescamento	-
☐	Altro	-

Indici di prestazione energetica globali ed emissioni

Indice della prestazione energetica non rinnovabile
EPgl,nren
kWh/m^2 anno
353,74

Indice della prestazione energetica rinnovabile
EPgl,ren
kWh/m^2 anno
0,00

Emissioni di CO_2
kg/m^2 anno
77,48

RACCOMANDAZIONI

La sezione riporta gli interventi raccomandati e la stima dei risultati conseguibili, con il singolo intervento o con la realizzazione dell'insieme di essi, esprimendo una valutazione di massima del potenziale di miglioramento dell'edificio o dell'immobile oggetto dell'attestato di prestazione energetica.

RIQUALIFICAZIONE ENERGETICA E RISTRUTTURAZIONE IMPORTANTE

INTERVENTI RACCOMANDATI E RISULTATI CONSEGUIBILI

Codice	TIPO DI INTERVENTO RACCOMANDATO	Comporta una ristrutturazione importante	Tempo di ritorno dell'investimento [anni]	Classe energetica raggiungibile con l'intervento [EPgl,nren - kWh/m^2 anno]	CLASSE ENERGETICA raggiungibile se si realizzano tutti gli interventi raccomandati
REN1	Pareti verso esterno (Esterno)	Sì	15,2	F - 270,42	A2 55,07 kWh/m^2 anno 12 anni
REN2					
REN3	Rimozione dell'impianto/i CALDAIA A GAS e installazione dei seguenti nuovi impianti: Generatore alimentato a biomassa, Caldaia a condensazione	No	3,6	A1 - 75,01	
REN4					
REN5					
REN6	Installazione dei seguenti impianti: Solare termico	No	27,0	G - 355,12	

ALTRI DATI ENERGETICI GENERALI

Energia esportata	0,00 kWh/anno	Vettore energetico: -

ALTRI DATI DI DETTAGLIO DEL FABBRICATO

V - Volume riscaldato	820,080	m^3
S - Superficie disperdente	876,991	m^2
Rapporto S/V	1,069	
$EP_{H,nd}$	231,8	kWh/m^2 anno
$A_{sol,est}/A_{sup,utile}$	0,07	-
Y_{IE}	0,52	W/m^2K

DATI DI DETTAGLIO DEGLI IMPIANTI

Servizio energetico	Tipo di impianto	Anno di installazione	Codice catasto regionale impianti termici	Vettore energetico utilizzato	Potenza Nominale kW	Efficienza media stagionale		EPren kWh/m^2 anno	EPnren kWh/m^2 anno
Climatizzazione invernale						0,689	η_H	0,0	336,4
Climatizzazione estiva							η_C		
Prod. acqua calda sanitaria						0,756	η_W	0,0	17,3
Impianti combinati	CALDAIA A GAS			GPL	24,0	0,857	η_{gn}		
Produzione da fonti rinnovabili	Fotovoltaico (Silicio mono cristallino, mq. 30,0)			Energia solare	4,50				
Ventilazione meccanica									
Illuminazione									
Trasporto di persone o cose									

INFORMAZIONI SUL MIGLIORAMENTO DELLA PRESTAZIONE ENERGETICA

La sezione riporta informazioni sulle opportunità, anche in termini di strumenti di sostegno nazionali o locali, legate all'esecuzione di diagnosi energetiche e interventi di riqualificazione energetica, comprese le ristrutturazioni importanti.

SOGGETTO CERTIFICATORE

☐ Ente / Organismo pubblico	☒ Tecnico abilitato	☐ Organismo / Società

Nome e Cognome / Denominazione	Dott. Ing. Alessio Pinna
Indirizzo	
E-mail	
Telefono	
Titolo	
Ordine/Iscrizione	
Dichiarazione di indipendenza	*Consapevole delle responsabilità assunte in relazione ai contenuti del presente attestato di prestazione energetica, ai sensi degli artt. 359, 481 del Codice Penale, DICHIARO di poter svolgere con indipendenza ed imparzialità di giudizio, l'attività di soggetto certificatore per il sistema edificio/impianto di cui al punto 1 "informazioni generali" vista l'assenza di conflitti di interesse come esplicitati nel DPR n. 75 del 16 aprile 2013, articolo 3, comma 1, lettere a) e b).*
Informazioni aggiuntive	

SOPRALLUOGHI E DATI DI INGRESSO

E' stato eseguito almeno un sopralluogo/rilievo sull'edificio obbligatorio per la redazione del presente APE?	Sì

SOFTWARE UTILIZZATO

Il software utilizzato risponde ai requisiti di rispondenza e garanzia di scostamento massimo dei risultati conseguiti rispetto ai valori ottenuti per mezzo dello strumento di riferimento nazionale?	Sì
Ai fini della redazione del presente attestato è stato utilizzato un software che impieghi un metodo di calcolo semplificato?	No

Il presente attestato è reso, dal sottoscritto, in forma di dichiarazione sostitutiva di atto notorio ai sensi dell'articolo 47 del D.P.R. 445/2000 e dell'articolo 15, comma 1 del D.Lgs. 192/2005 così come modificato dall'articolo 12 del D.L. 63/2013

Data di emissione 05/11/2024 Firma e timbro del tecnico o firma digitale

ORDINE INGEGNERI PROVINCIA CAGLIARI N. 6873 Dott. Ing. ALESSIO PINNA

Il presente documento attesta la **prestazione** e la **classe energetica** dell'edificio o dell'unità immobiliare, ovvero la quantità di energia necessaria ad assicurare il confort attraverso i diversi servizi erogati dai sistemi tecnici presenti, in condizioni convenzionali d'uso. Al fine di individuare le potenzialità di miglioramento della prestazione energetica, l'attestato riporta informazioni specifiche sulle prestazioni energetiche del fabbricato e degli impianti. Viene altresì indicata la classe energetica più elevata raggiungibile in caso di realizzazione delle misure migliorative consigliate, così come descritte nella sezione "**raccomandazioni**" (pag. 2).

PRIMA PAGINA

Informazioni generali: tra le informazioni generali è riportata la motivazione alla base della redazione dell'APE. Nell'ambito del periodo di validità, ciò non preclude l'uso dell'APE stesso per i fini di legge, anche se differenti da quelli ivi indicati.
Prestazione energetica globale (EPgl,nren): fabbisogno annuale di energia primaria non rinnovabile relativa a tutti i servizi erogati dai sistemi tecnici presenti, in base al quale è identificata la classe di prestazione dell'edificio in una scala da A4 (edificio più efficiente) a G (edificio meno efficiente).
Prestazione energetica del fabbricato: indice qualitativo del fabbisogno di energia necessario per il soddisfacimento del confort interno, indipendente dalla tipologia e dal rendimento degli impianti presenti. Tale indice da un'indicazione di come l'edificio, d'estate e d'inverno, isola termicamente gli ambienti interni rispetto all'ambiente esterno. La scala di valutazione qualitativa utilizzata osserva il seguente criterio:

QUALITA' ALTA	QUALITA' MEDIA	QUALITA' BASSA

I valori di soglia per la definizione del livello di qualità, suddivisi per tipo di indicatore, sono riportati nelle Linee guida per l'attestazione energetica degli edifici di cui al decreto previsto dall'articolo 6, comma 12 del D.Lgs. 192/2005.
Edificio a energia quasi zero: edificio ad altissima prestazione energetica, calcolata conformemente alle disposizioni del decreto legislativo 19 agosto 2005, n. 192 e del decreto ministeriale sui requisiti minimi previsto dall'articolo 4, comma 1 del D.Lgs. 192/2005. Il fabbisogno energetico molto basso o quasi nullo è coperto in misura significativa da energia da fonti rinnovabili, prodotta all'interno del confine del sistema (in situ). Una spunta sull'apposito spazio adiacente alla scala di classificazione indica l'appartenenza dell'edificio oggetto dell'APE a questa categoria.
Riferimenti: raffronto con l'indice di prestazione globale non rinnovabile di un edificio simile ma dotato dei requisiti minimi degli edifici nuovi, nonchè con la media degli indici di prestazione degli edifici esistenti simili, ovvero contraddistinti da stessa tipologia d'uso, tipologia costruttiva, zona climatica, dimensioni ed esposizione di quella oggetto dell'attestato.

SECONDA PAGINA

Prestazioni energetiche degli impianti e consumi stimati: la sezione riporta l'indice di prestazione energetica rinnovabile e non rinnovabile dell'immobile oggetto di attestazione. Tali indici informano sulla percentuale di energia rinnovabile utilizzata dall'immobile rispetto al totale. La sezione riporta infine una stima del quantitativo di energia consumata annualmente dall'immobile secondo un uso standard, suddivisi per tipologia di fonte energetica utilizzata.
Raccomandazioni: di seguito si riporta la tabella che classifica le tipologie di intervento raccomandate per la riqualificazione energetica e la ristrutturazione importante.

RIQUALIFICAZIONE ENERGETICA E RISTRUTTURAZIONE IMPORTANTE EDIFICIO/UNITA' IMMOBILIARE - Tabella dei Codici

Codice	TIPO DI INTERVENTO
REN1	FABBRICATO - INVOLUCRO OPACO
REN2	FABBRICATO - INVOLUCRO TRASPARENTE
REN3	IMPIANTO CLIMATIZZAZIONE - INVERNO
REN4	IMPIANTO CLIMATIZZAZIONE - ESTATE
REN5	ALTRI IMPIANTI
REN6	FONTI RINNOVABILI

TERZA PAGINA

La terza pagina riporta la quantità di energia prodotta in situ ed esportata annualmente, nonchè la sua tipologia.
Riporta infine, suddivise in due sezioni relative rispettivamente al fabbricato e agli impianti, i dati di maggior dettaglio alla base del calcolo.

PRESCRIZIONI PARTICOLARI DA OSSERVARE

A) **Contributi per il rilascio della concessione** (Art. 3 legge 28-1-1977 n. 10)

1) CONTRIBUTO COMMISURATO ALL'INCIDENZA DELLE OPERE DI URBANIZZAZIONE:

2) CONTRIBUTO A PERCENTUALE SUL COSTO DI COSTRUZIONE:

3) GARANZIA:

B) **Obblighi diversi:**

Le opere di urbanizzazione primaria mancanti o non previste nei programmi comunali di attuazione per il triennio in corso, debbono essere realizzate a cura e spese del concessionario a scomputo degli oneri di urbanizzazione primaria.

Dalla Residenza Municipale, li 22 DIC. 1990

IL SINDACO

Il sottoscritto concessionario si obbliga all'osservanza di tutte le prescrizioni contenute nella presente concessione edilizia.

Addì, 22 DIC. 1990

IL CONCESSIONARIO

N.B. - Qualora nel corso della realizzazione delle opere o comunque di lavori coevi e successivi vengano in luce documenti e beni culturali soggetti alla tutela della legge 1-6-1939, n. 1089 e successive modifiche, dovranno essere rispettate le prescrizioni della legge suddetta informandone tempestivamente la competente Soprintendenza Archeologica.

All. 3

COMUNE DI SENNORI

PROVINCIA DI SASSARI

COMUNE DI SENNORI - Ufficio Tecnico

Pratica Edilizia N. 19/87 Quinqies

CONCESSIONE EDILIZIA N. 19/87 Quinquies

IL SINDACO

— Vista la domanda di concessione in data 20.06.1990, prot. n. 4807, presentata da: , nato a il e residente a in

Cod. Fisc.

relativa alla esecuzione di lavori di variante al progetto per la costruzione di una casa per civile abitazione

in territorio di questo Comune Via S. Allende (località), su area distinta in catasto C.T. (C.T. - N.C.E.U.) al Foglio 22 Mapp. 945 Particella =;

— Visti i disegni di progetto allegati alla domanda, a firma del Geom.;

— Vista la relazione-parere dell'Ufficio Tecnico Comunale;

— Visti i pareri dell'Ufficiale Sanitario e della Commissione Edilizia Comunale, collegialmente espressi nella seduta del 10.07.1990 verbale n. 7;

— Visto

— Visti i regolamenti comunali di edilizia, igiene e polizia urbana in vigore;

— Viste le leggi 17-8-1942 n. 1150; 6-8-1967 n. 765 e le successive modificazioni e integrazioni;

— Vista la legge 28-1-1977 n. 10;

— Vista la legge 28-2-1985 n. 47 e successive modificazioni e integrazioni;

— Vista la legge reg. 11-10-1985 n. 23 e successive modificazioni e integrazioni;

— Accertata, sulla base della documentazione in atti, la sussistenza di legittimo titolo ad ottenere il rilascio della concessione da parte del richiedente;

— Preso atto della conformità degli atti progettuali allo strumento urbanistico vigente;

CONCEDE

al richiedente nominato in premessa di eseguire i lavori e le opere di cui in narrativa, **salvi e riservati i diritti di terzi**, sotto l'osservanza delle vigenti disposizioni in materia di edilizia, di igiene e di polizia locale, in conformità del progetto approvato che si allega come parte integrante e sostanziale della presente concessione, secondo le migliori norme dell'arte, affinchè l'opera riesca solida, igienica, decorosa e atta alla sua destinazione, tanto per i materiali usati quanto per il sistema costruttivo adottato.

E' fatto obbligo al concessionario del rispetto e adempimento delle prescrizioni generali e particolari, e delle clausole di seguito riportate:

COMUNE DI SENNORI
PROVINCIA DI SASSARI

IL SINDACO

Visto il parere espresso dalla commissione edilizia in seduta del 10-07-90 verbale N. 7 autorizza Solit

Sennori, li 11-07-1990

Il Sindaco

-STUDIO - TECNICO - TEL.		
-GEOM. - VIA DEL FIORE N° 5 SENNORI.		
PROGETTO: DI VARIANTE IN CORSO D'OPERA DELLA CASA DI CIVILE ABITAZIONE SITA IN VIA S. ALLIENDE LOTT. NE . C.E. 19-87 QUATER DEL 19.05.90.		
COMUNE DI SENNORI	PROV. DI SASSARI	DATA 20 GIU. 1990
ELABORATO PIANTE - PROSPETTI - SEZIONI.		SCALA 1 : 100
TAV. UNICA	IL COMMITTENTE CONIUGI	IL TECNICO

COLLEGIO PROVINCIALE GEOMETRI N. 1933 SASSARI



COMUNE DI SENNORI

FOGLIO 22 M.LE 945

SCALA 1 : 2000

Planimetria catastale

Stralcio Planivolumetrico

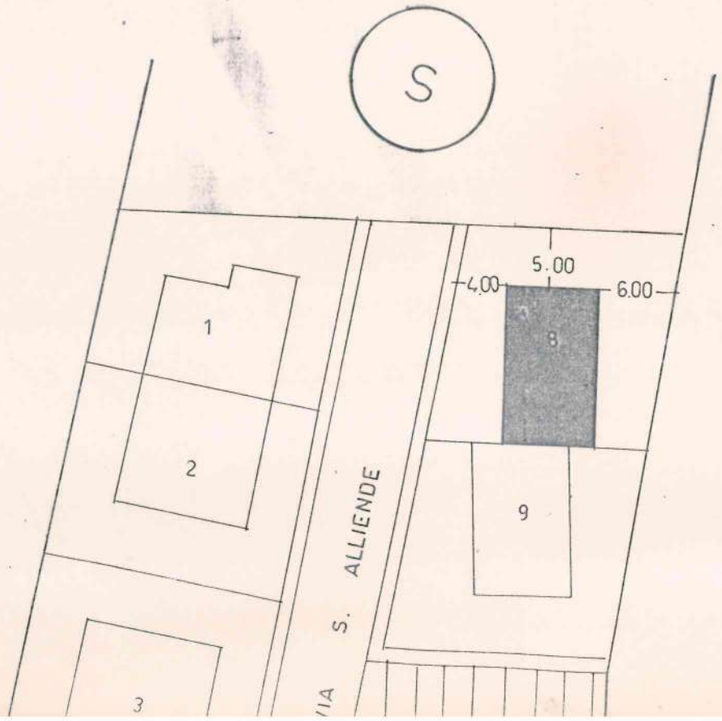

Seminterrato

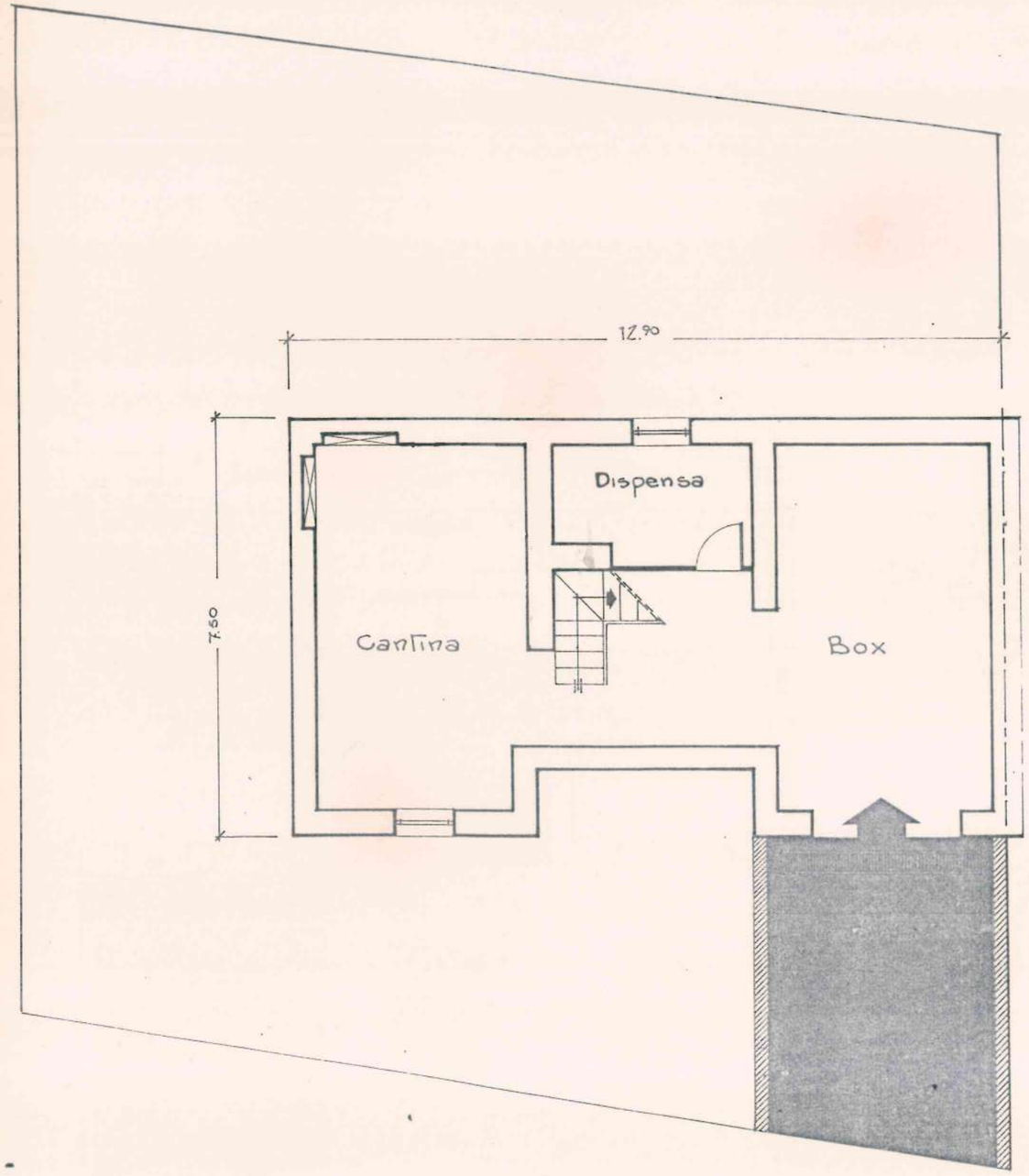

Piano Terra

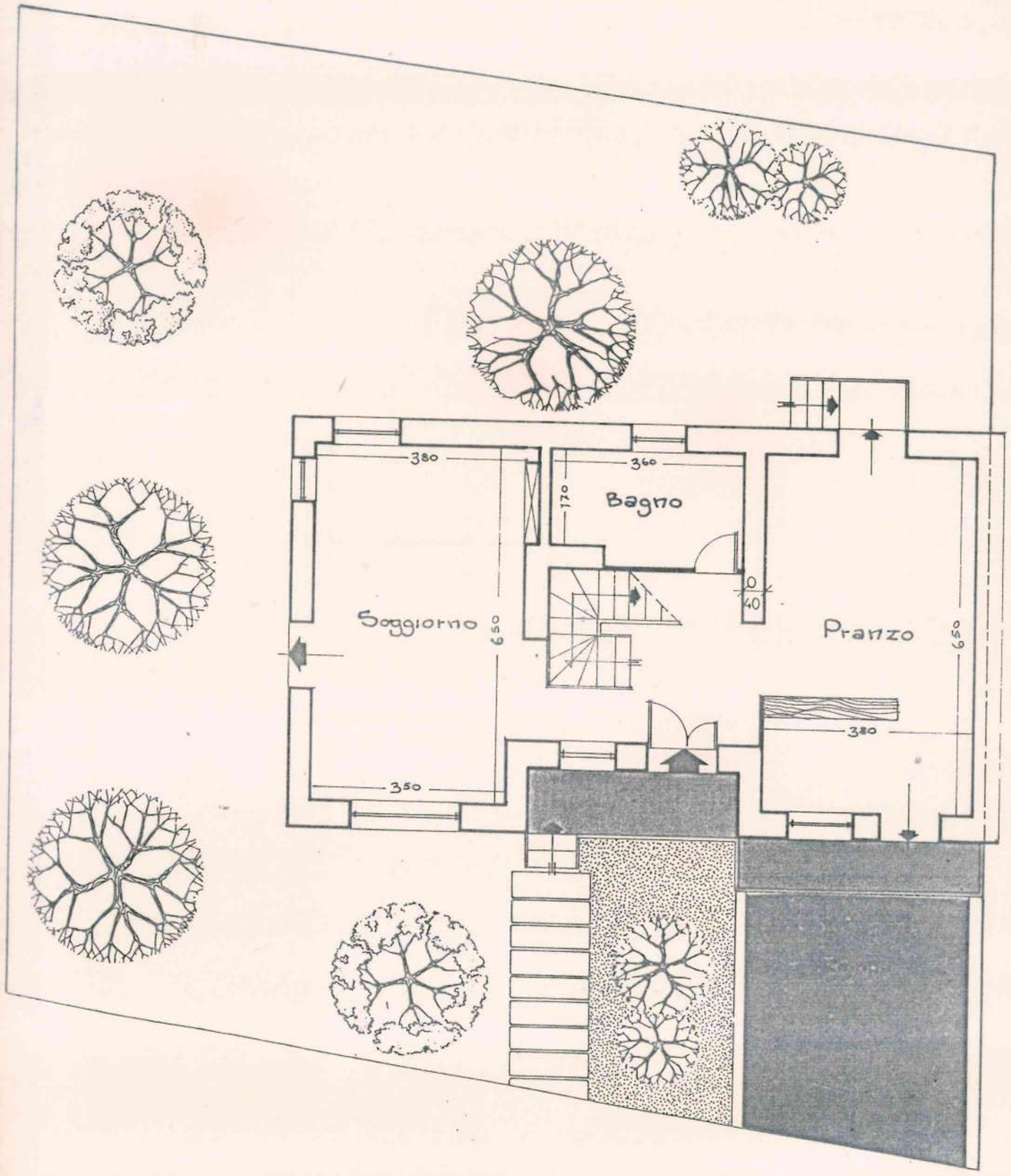

Primo Piano

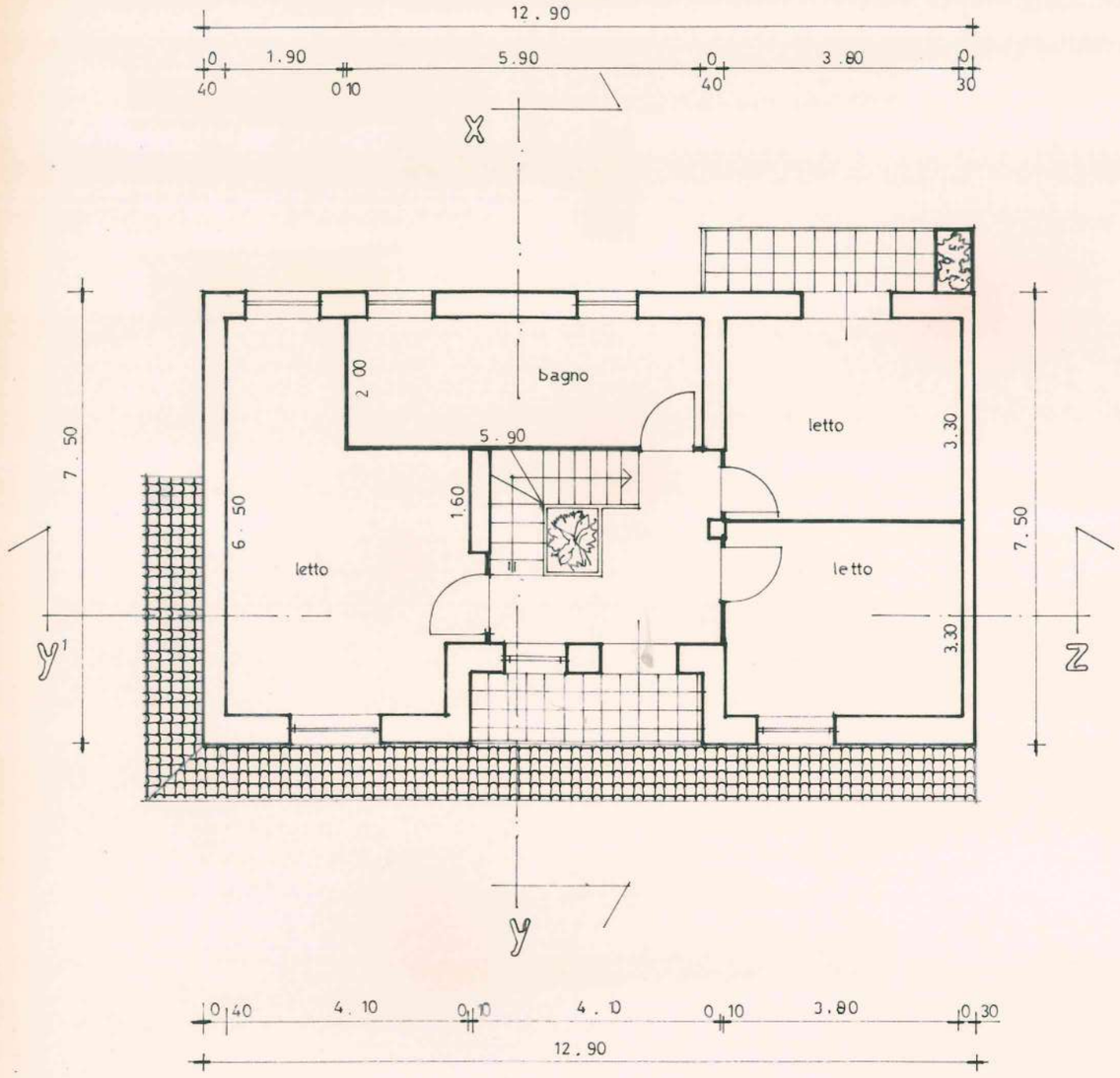

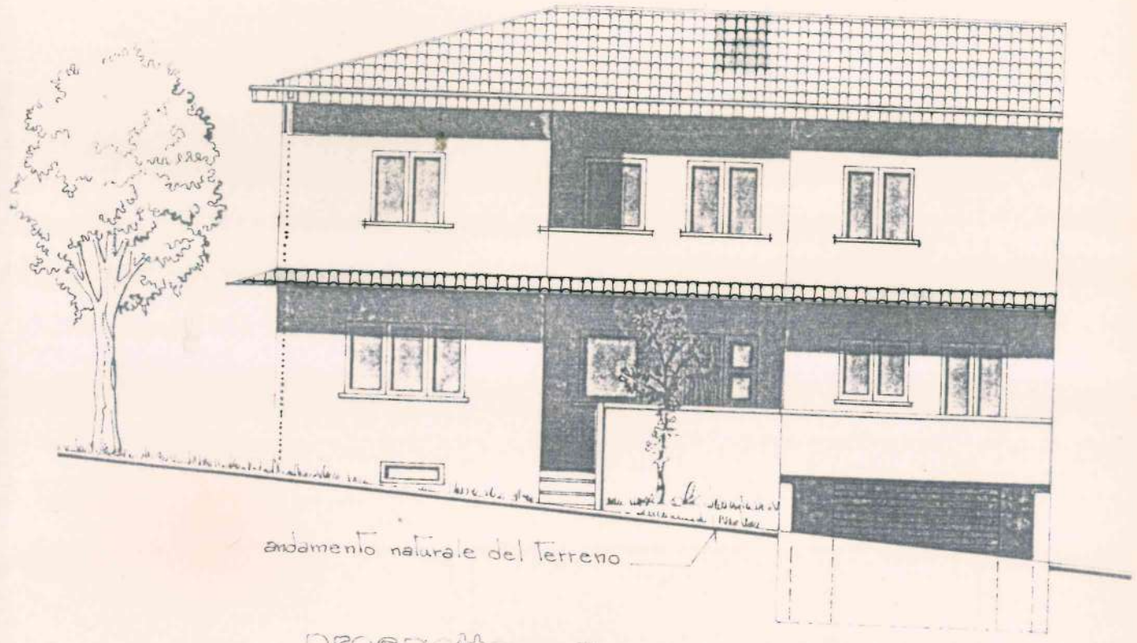

prospetto a

Prospetto B





prospetto c

sezione x y

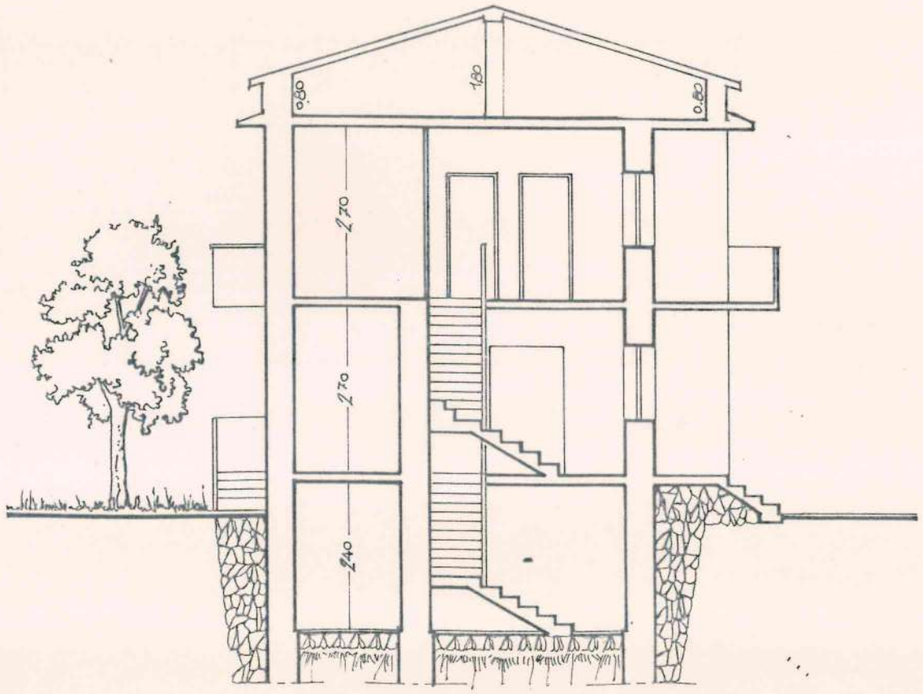

sezione y'z

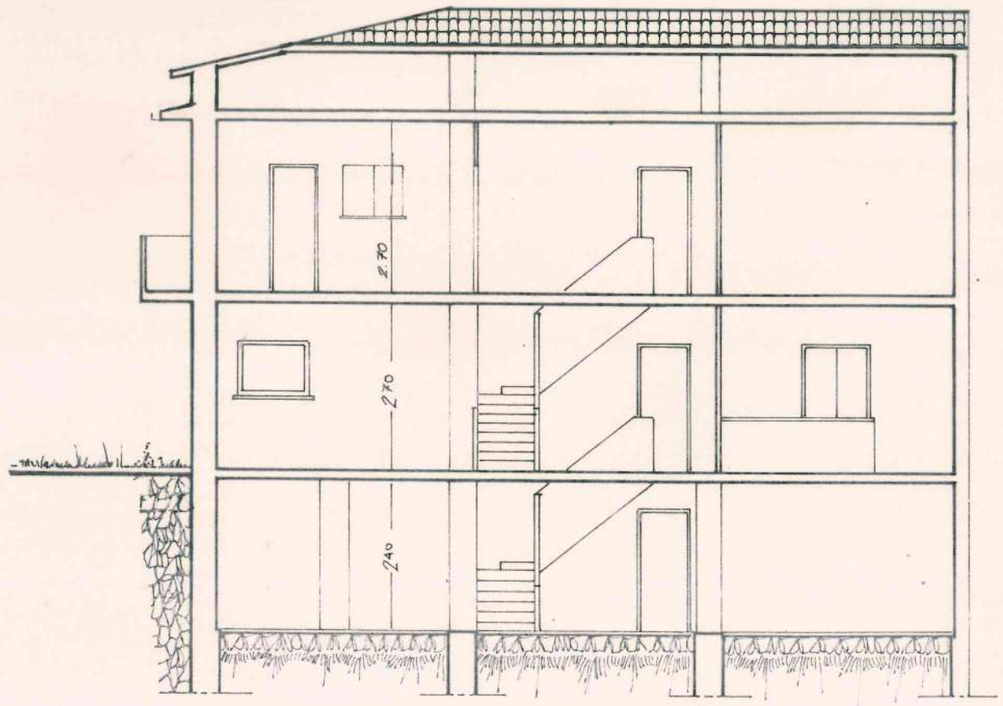

Coperture

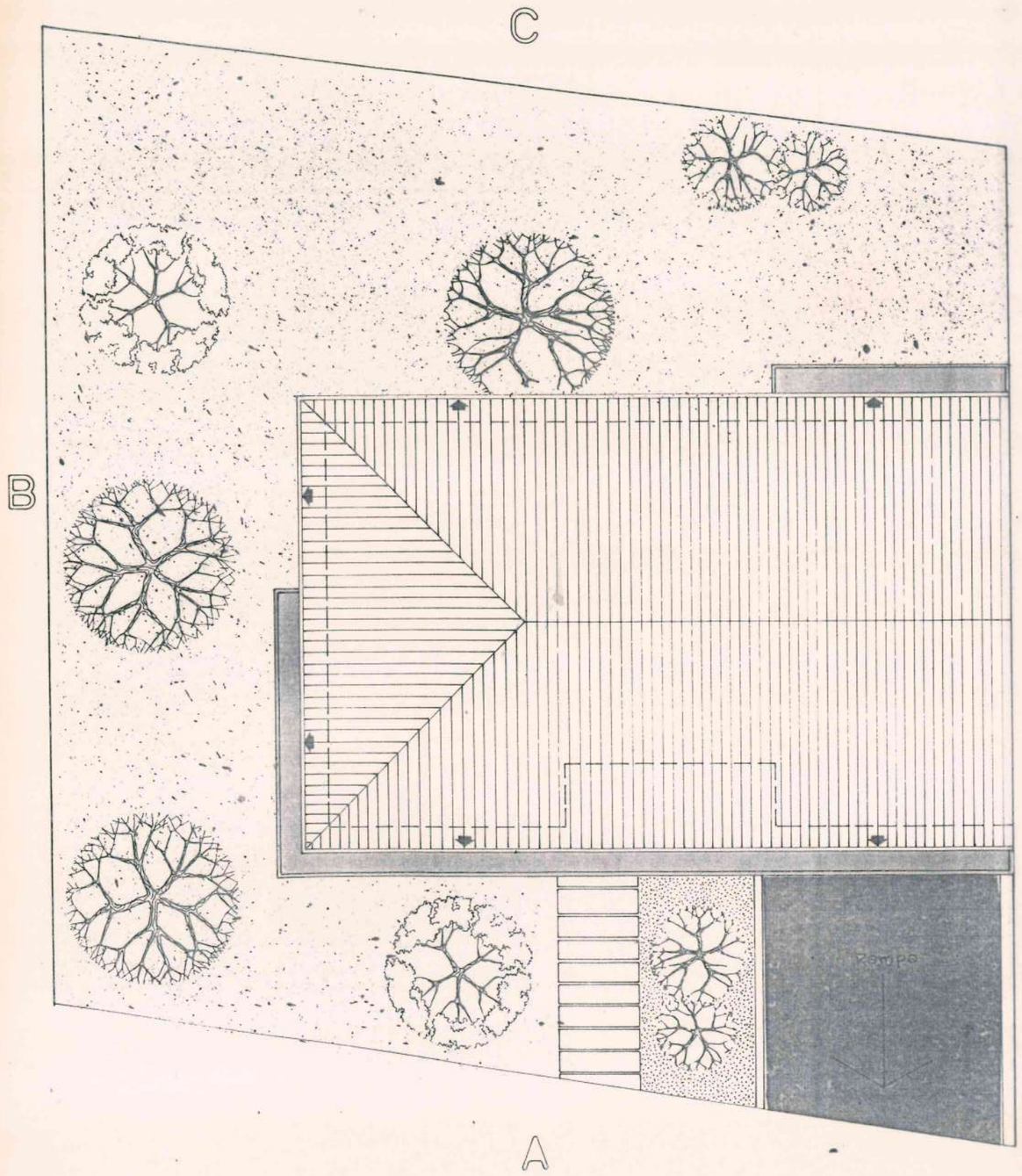

Calcolo dei Volumi

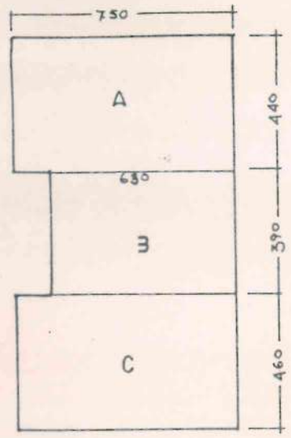

PIANO SEMINTERRATO

	Sup. mq.	h. mL	Vol. mc.
A	33 . 00	2 . 60	85 . 80
B	24 . 57	2 . 60	63 . 88
C	34 . 50	2 . 60	89 . 70
Totale	92 . 07		239 . 38

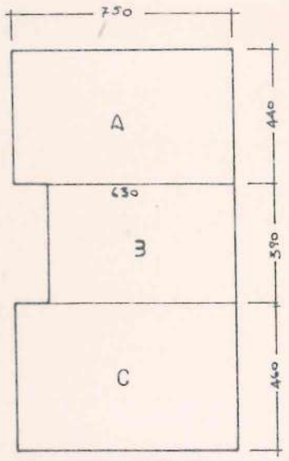

PIANO TERRA

	Sup. mq.	h. m L	Vol. mc.
A	33 . 00	2 . 90	95 . 70
B	24 . 57	2 . 90	71 . 25
C	34 . 50	2 . 90	100 . 05
Totale	92 . 07		267 . 00

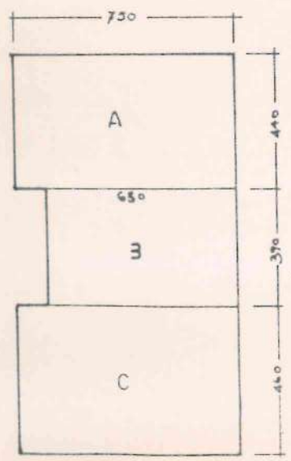

PIANO PRIMO

	Sup. mq.	h. m.L	Vol. mc.
A	33 . 00	2 . 90	95 . 70
B	24 . 57	2 . 90	71 . 25
C	34 . 50	2 . 90	100 . 05
Totale	92 . 07		267 . 00

VOLUME TOTALE MC. 588 . 86

PIANO SOTTOTETTO

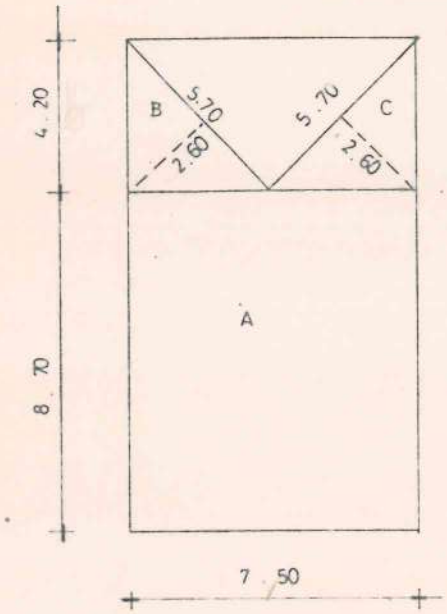

	SUP. MQ	H. ML.	VOL. MC.
A	65 . 25	0 . 80	52 . 20
B	7 . 41	0 . 80	5 . 93
C	7 . 41	0 . 80	5 . 93
TOT	80 . 07		64 . 06